Donnerstag 05.02.2026

Veröffentlicht am 04.02.2026 um 17:00

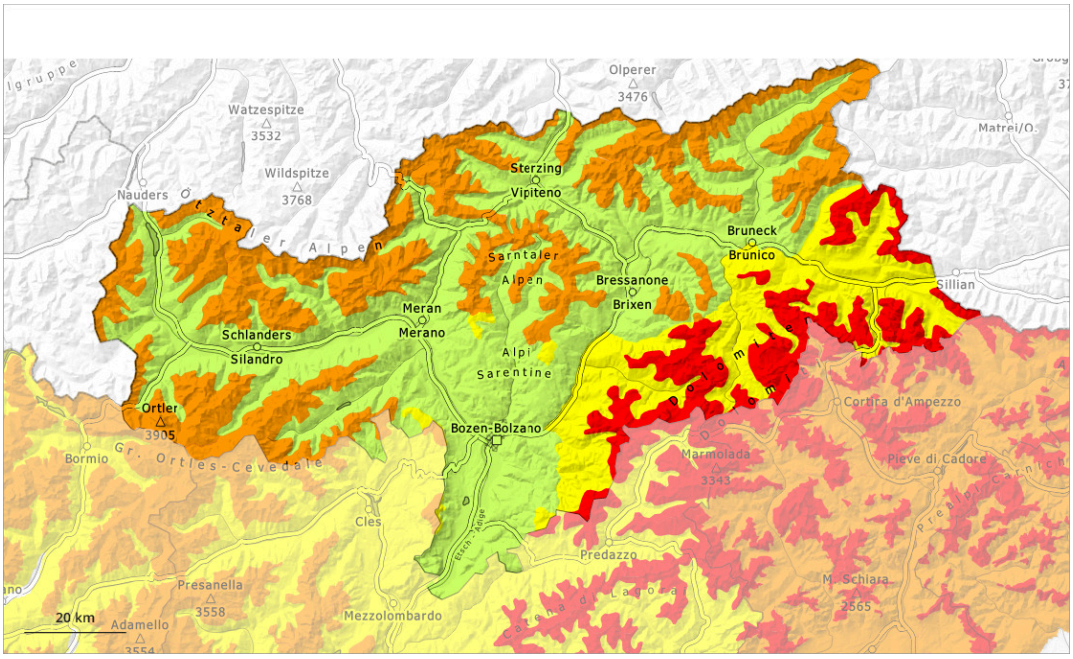

1	2	3	4	5
gering	mäßig	erheblich	groß	sehr groß

Gefahrenstufe 4 - Groß

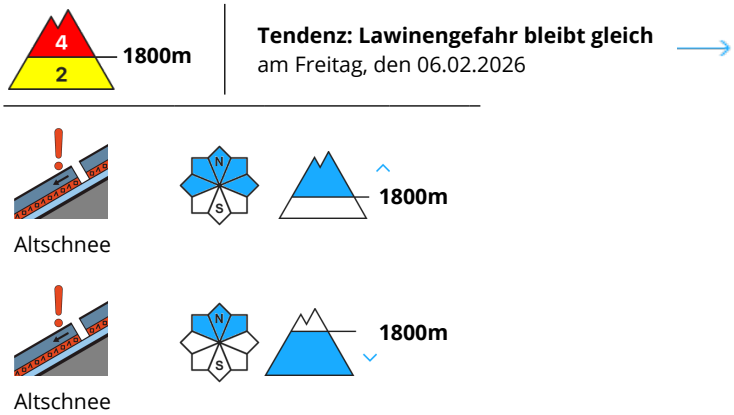

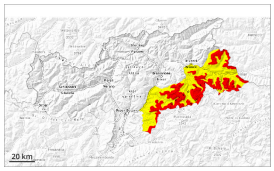

Die Verhältnisse für Schneesport abseits gesicherter Pisten sind kritisch.

Vor allem an West-, Nord- und Osthängen sind in der ersten Nachthälfte vermehrt mittlere und vereinzelt große spontane Lawinen möglich. Dies besonders in den Hauptniederschlagsgebieten. Lawinen können vielerorts im Altschnee ausgelöst werden.

Die Gefährdung bezieht sich vor allem auf alpines Schneesportgelände. Spontane Lawinenabgänge sowie Wummgeräusche sind deutliche Zeichen eines schwachen Schneedeckenaufbaus. Fernauslösungen sind wahrscheinlich. Die Gefahrenstellen sind häufig und kaum zu erkennen.

Schneedecke

Gefahrenmuster gm.1: bodennahe schwachschicht | gm.8: eingeschneiter oberflächenreif

Seit Dienstag fielen 10 bis 25 cm Schnee. Es fallen 20 bis 40 cm Schnee, lokal auch mehr. Der Neuschnee wird auf eine schwache Altschneedecke abgelagert. In der Altschneedecke sind ausgeprägte Schwachschichten vorhanden.

Tendenz

Die Lawinenverhältnisse bleiben heikel.

Gefahrenstufe 3 - Erheblich

Waldgrenze

Tendenz: Lawinengefahr bleibt gleich
am Freitag, den 06.02.2026

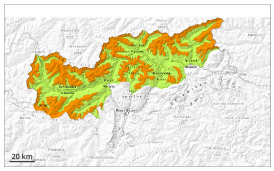

Altschnee

Waldgrenze

Triebschnee

Waldgrenze

Heimtückische Lawinensituation. Vorsicht vor Triebschnee und schwachem Altschnee.

Ausgeprägte Schwachschichten im unteren Teil der Schneedecke können von einzelnen Wintersportlern leicht ausgelöst werden. Zudem sind die frischen Triebschneeansammlungen sehr leicht auslösbar. Lawinen können den schwachen Altschnee mitreißen und mittlere Größe erreichen.
Vorsicht vor allem an steilen West-, Nord- und Osthängen oberhalb der Waldgrenze.

Wummgeräusche und Risse beim Betreten der Schneedecke sowie spontane Lawinenabgänge sind Alarmzeichen und weisen auf die Gefahr hin. Die Gefahrenstellen sind teils überschneit und damit schwer zu erkennen. Fernauslösungen sind möglich.
Vorsicht und Zurückhaltung sind empfohlen.

Schneedecke

Gefahrenmuster gm.1: bodennahe schwachschicht | gm.8: eingeschneiter oberflächenreif

Es fallen bis zu 15 cm Schnee, lokal auch mehr.
Neu- und Triebschnee werden auf eine ungünstige Altschneeoberfläche abgelagert. In der Altschneedecke sind ausgeprägte Schwachschichten vorhanden. Dies besonders an West-, Nord- und Osthängen.

Tendenz

Die Lawinenverhältnisse bleiben heimtückisch.

Gefahrenstufe 2 - Mäßig

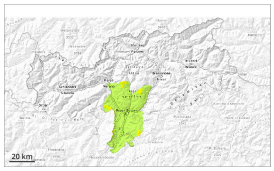

Waldgrenze

Tendenz: Lawinengefahr bleibt gleich
am Freitag, den 06.02.2026

Triebschnee

Waldgrenze

Vorsicht vor frischem Triebschnee.

Die frischen Triebschneeansammlungen können teils leicht ausgelöst werden. Dies besonders an steilen Schattenhängen sowie in Kammlagen, Rinnen und Mulden oberhalb der Waldgrenze. Lawinen sind vereinzelt mittelgroß. Die Gefahrenstellen sind teils überschneit und damit schwer zu erkennen.

Nebst der Verschüttungsgefahr sollte vor allem die Mitreiß- und Absturzgefahr beachtet werden.

Schneedecke

Gefahrenmuster gm.6: lockerer schnee und wind

Die frischen Triebschneeansammlungen werden in der Höhe auf eine ungünstige Altschneeoberfläche abgelagert. Die Altschneedecke ist aufbauend umgewandelt.

Die Schneedecke ist allgemein kleinräumig sehr unterschiedlich.

Tendenz

Mäßige Lawinengefahr. Frischen Triebschnee beachten.