ICGC Institut Cartogràfic i Geològic de Catalunya

Servei Meteorològic de Catalunya meteo.cat

Boletín de peligro de aludes para el Pirineo de Catalunya
Del 04/02/2026 al 05/02/2026

(Válido fuera pistas de esquí y zonas no controladas)

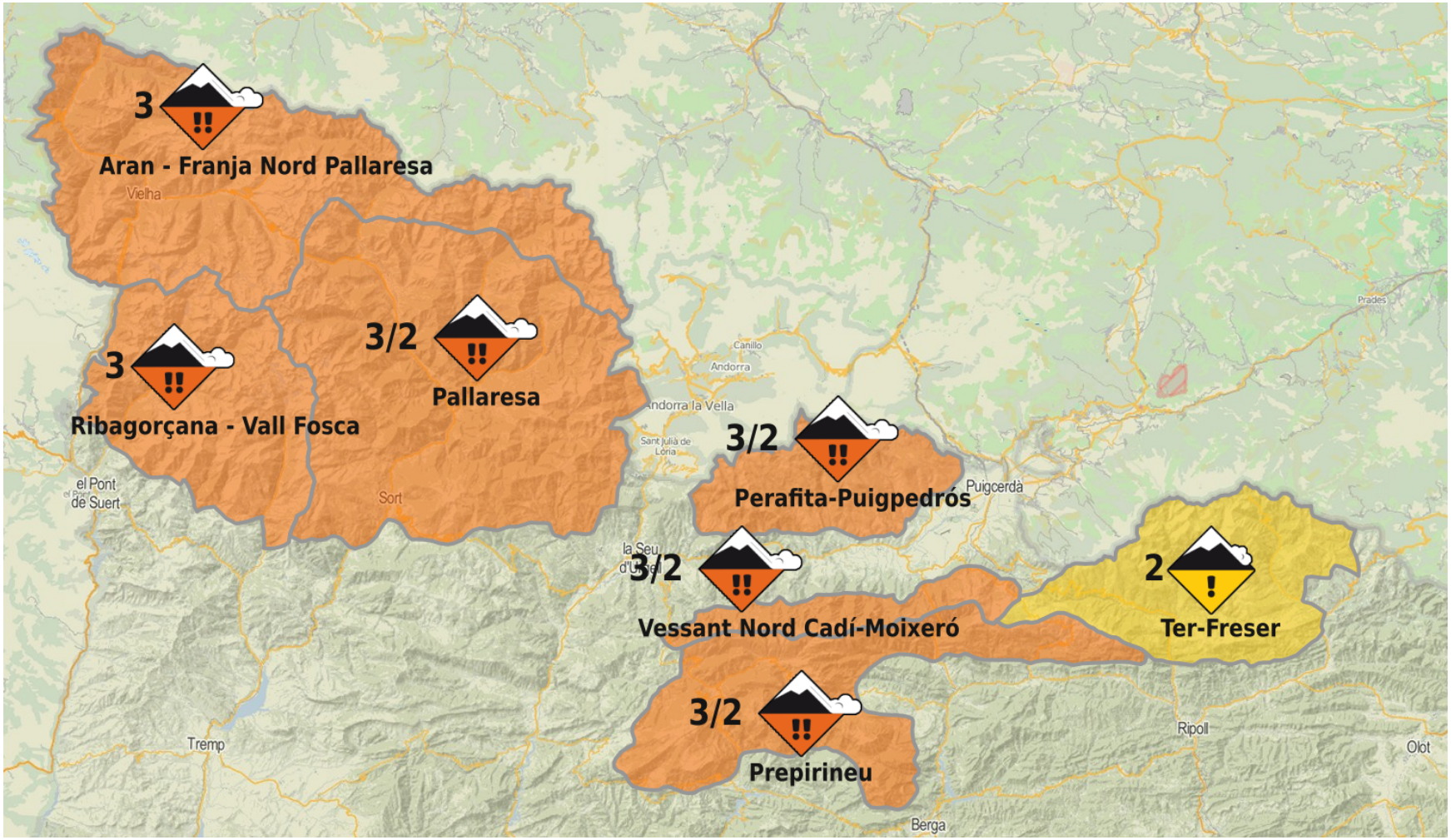

5 MUY FUERTE	4 FUERTE	3 NOTABLE	2 LIMITADO	1 DÉBIL

ICGC Institut Cartogràfic i Geològic de Catalunya

meteo.cat Servei Meteorològic de Catalunya

Boletín de peligro de aludes Aran - Franja Nord Pallaresa Del 04/02/2026 al 05/02/2026

(Válido fuera pistas de esquí y zonas no controladas)

NOTABLE (3)

Situación primaria

Nieve venteada

Distribución

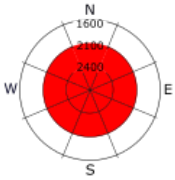

Tamaño

Origen

Tendencia

Situación secundaria

Deslizamientos basales

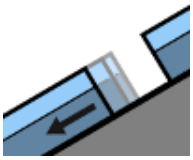

Distribución

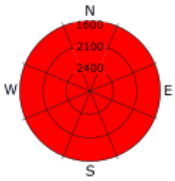

Tamaño

Origen

Tendencia

Estado del manto nivoso

El miércoles se prevén nevadas débiles y viento moderado. El jueves las precipitaciones pueden ser moderadas, sobre todo en el S, con cota de nieve que subirá hacia los 2.000 m en las horas centrales del día, puntualmente más arriba, y fuerte viento del W-SW.

Se formarán nuevas placas, en cualquier orientación pero preferentemente en N y E, por encima del límite del bosque. Las placas nuevas serán frágiles y podrán romperse fácilmente al paso de una persona -localmente de forma natural-, generando aludes en general de tamaño medio. Aumenta la probabilidad de deslizamientos basales en cualquier orientación y cota, más probables en S. Estos podrán ser de hasta tamaño medio, sin descartar alguno, muy localmente, de tamaño 3, grande.

Asimismo, también son probables purgas o aludes pequeños de nieve húmeda por debajo del nivel de bosque en cualquier orientación, sobre todo a partir de mediodía y por la tarde, donde al final podrían ser de tamaño medio puntualmente al S del sector.

Distribución del manto nivoso

Hay nieve en el suelo a 1.000 m. El manto es esquiable por encima de unos 1.500 m. Los espesores a unos 2.200 m rondan los 100-135 cm en el norte de Arán y 130-180 cm en la Franja Norte Pallaresa y en el sur de Aran, y son superiores a los normales por estas fechas.

Tendencia para las próximas 48-72h

La nubosidad y bajada de temperatura podrá ir estabilizando el manto. Peligro EN DESCENSO.

El próximo boletín será emitido el día 2026-02-05

5 MUY FUERTE	4 FUERTE	3 NOTABLE	2 LIMITADO	1 DÉBIL

EAWS EUROPEAN AVALANCHE WARNING SERVICES

ICGC Institut Cartogràfic i Geològic de Catalunya

meteo.cat Servei Meteorològic de Catalunya

Boletín de peligro de aludes Ribagorçana - Vall Fosca Del 04/02/2026 al 05/02/2026

(Válido fuera pistas de esquí y zonas no controladas)

NOTABLE (3)

Situación primaria

Nieve venteada

Distribución

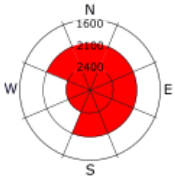

Tamaño

Origen

Tendencia

Situación secundaria

Nieve húmeda

Distribución

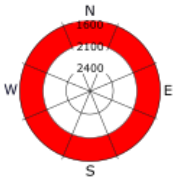

Tamaño

Origen

Tendencia

Estado del manto nivoso

El manto nivoso irá inestabilizando progresivamente el jueves por las nevadas y el viento previstos. La cota de nieve subirá hasta los 2.000 m aprox. en las horas centrales del día y viento fuerte en cotas altas del W-SW. Se prevé formación de nuevas placas por encima del nivel del bosque. Es posible actividad de aludes de placa en cualquier orientación, más probables, sin embargo, en orientaciones N y E. Los aludes de placa en general serán por desencadenamiento accidental, muy localmente natural, y serían de tamaño 2, medio, en general, sin descartar alguna muy puntual de tamaño 3, grande.

Las lluvias previstas por la mañana y mediodía del jueves hasta unos 2.000 m también harán que, por debajo de esta cota, sean probables aludes de nieve húmeda en cualquier orientación. Serán frecuentes purgas y caídas de bolas, o incluso aludes de tamaño 2 en lugares de fuerte pendiente y donde la nieve no se encontrara muy placada.

Distribución del manto nivoso

Hay nieve en el suelo a 1.500 m. El manto es esquiable por encima de unos 1500-1600 m. Los grosores alcanzan los 120-150 cm. Estos valores son muy superiores a los normales en la época.

Tendencia para las próximas 48-72h

La nubosidad y bajada de temperatura podrá ir estabilizando el manto. Peligro EN DESCENSO.

El próximo boletín será emitido el día 2026-02-05

5 MUY FUERTE	4 FUERTE	3 NOTABLE	2 LIMITADO	1 DÉBIL

EAWS EUROPEAN AVALANCHE WARNING SERVICES

ICGC Institut Cartogràfic i Geològic de Catalunya

Servei Meteorològic de Catalunya

Boletín de peligro de aludes Pallaresa
Del 04/02/2026 al 05/02/2026

(Válido fuera pistas de esquí y zonas no controladas)

NOTABLE (3) por encima de 2.200 m.
LIMITADO (2) por debajo.

Situación primaria

Nieve venteada

Distribución

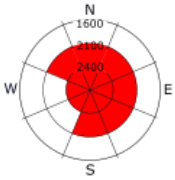

Tamaño

Origen

Tendencia

Situación secundaria

Nieve húmeda

Distribución

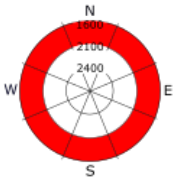

Tamaño

Origen

Tendencia

Estado del manto nivoso

El miércoles ha nevado débilmente en el sector. El jueves se esperan precipitaciones moderadas con cota de nieve que irá subiendo hasta los 2000 m aprox. en las horas centrales del día y viento fuerte en cotas altas del W-SW. El manto nivoso se irá inestabilizando progresivamente el jueves. Se prevé formación de nuevas placas por encima del nivel del bosque.

Es posible actividad de aludes de placa en cualquier orientación, más probables, sin embargo, en orientaciones N y E. Los aludes de placa en general serán por desencadenamiento accidental, sin descartar naturales muy localmente, y serían de tamaño 2, medio, en general.

Son probables también aludes de nieve húmeda por debajo del nivel de bosque, a cualquier orientación y preferentemente en laderas inclinadas. Estos aludes serían por lo general de tamaño pequeño, puntualmente de hasta tamaño medio, más probables por la tarde.

Distribución del manto nivoso

Hay nieve desde 1500 m, esquiable a 1500-1600 m. Los espesores en cotas altas y medias superan los 140 cm. Estos valores son superiores a los normales para la época.

Tendencia para las próximas 48-72h

La nubosidad y bajada de temperatura podrá ir estabilizando el manto. Peligro EN DESCENSO.

El próximo boletín será emitido el día 2026-02-05

5 MUY FUERTE	4 FUERTE	3 NOTABLE	2 LIMITADO	1 DÉBIL

EAWS EUROPEAN AVALANCHE WARNING SERVICES

ICGC Institut Cartogràfic i Geològic de Catalunya

meteo.cat Servei Meteorològic de Catalunya

Boletín de peligro de aludes Perafita-Puigpedrós Del 04/02/2026 al 05/02/2026

(Válido fuera pistas de esquí y zonas no controladas)

NOTABLE (3) por encima de 2.300 m.
LIMITADO (2) por debajo.

Situación primaria

Nieve venteada

Distribución

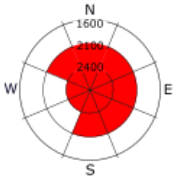

Tamaño

Origen

Tendencia

Situación secundaria

Nieve húmeda

Distribución

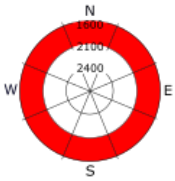

Tamaño

Origen

Tendencia

Estado del manto nivoso

El miércoles se prevén nevadas débiles y viento flojo. El jueves las precipitaciones pueden ser moderadas, con cota de nieve que subirá hacia los 2.000 m en las horas centrales del día, y fuerte viento del W-SW. Las placas viejas formadas el lunes pueden presentarse menos sensibles pero con el nuevo episodio de nieve se formarán nuevas, sobre todo en cotas altas y orientaciones N y E.
Las placas nuevas serán frágiles y podrán romper fácilmente al paso de una persona, generando aludes en general de tamaño medio o pequeño. Localmente, algún alud podría desencadenarse de forma natural.
Por debajo del límite de bosque aproximadamente, el humedecimiento del manto será progresivo a medida que la cota de nieve aumente, pudiendo provocar caída de bolas y aludes de nieve húmeda de tamaño 1, pequeño, en general, en vertientes inclinadas de cualquier orientación.

Distribución del manto nivoso

Hay nieve en el suelo por encima de 1.300 m, y el manto es esquiable por encima de 1.500-1.600 m. Los grosores alcanzan los 120-140 cm a 2.200 m. Son grosores muy por encima de los habituales por la época.

Tendencia para las próximas 48-72h

La nubosidad y bajada de temperatura podrá ir estabilizando el manto. Peligro EN DESCENSO.

El próximo boletín será emitido el día 2026-02-05

5 MUY FUERTE	4 FUERTE	3 NOTABLE	2 LIMITADO	1 DÉBIL

EAWS EUROPEAN AVALANCHE WARNING SERVICES

ICGC Institut Cartogràfic i Geològic de Catalunya

Servei Meteorològic de Catalunya

Boletín de peligro de aludes Vessant Nord Cadí-Moixeró Del 04/02/2026 al 05/02/2026

(Válido fuera pistas de esquí y zonas no controladas)

NOTABLE (3) por encima de 2.200 m.
LIMITADO (2) por debajo.

Situación primaria

Nieve venteada

Distribución

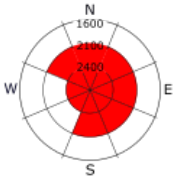

Tamaño

Origen

Tendencia

Situación secundaria

Nieve húmeda

Distribución

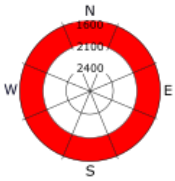

Tamaño

Origen

Tendencia

Estado del manto nivoso

El miércoles se prevén nevadas débiles y viento flojo. El jueves las precipitaciones pueden ser moderadas, con cota de nieve que subirá hacia los 2.000 m en las horas centrales del día, y fuerte viento del W-SW.
Las placas viejas formadas el lunes pueden presentarse menos sensibles pero con el nuevo episodio de nieve se formarán nuevas, sobre todo en cotas altas, en lo alto de las canales y bajo collados y cordales, en orientaciones N y E. Las placas nuevas serán frágiles y podrán romper fácilmente al paso de una persona, generando aludes en general de tamaño medio o pequeño. Localmente, algún alud podría desencadenarse de forma natural.
Por debajo del límite de bosque aproximadamente, el humedecimiento del manto puede provocar caída de bolas y aludes de nieve húmeda de tamaño 1, pequeño, en vertientes inclinadas de cualquier orientación, sobre todo a partir de mediodía y por la tarde, a medida que la cota de nieve aumente.

Distribución del manto nivoso

Hay nieve desde 1.200 a 1.300 m, esquiable por encima de unos 1.500 m. Los grosores están alrededor de 110-150 cm a 2.200 m después de la nevada de lunes a martes. Estos valores son muy excedentarios por la época del año.

Tendencia para las próximas 48-72h

La nubosidad y bajada de temperatura podrá ir estabilizando el manto. Peligro EN DESCENSO

El próximo boletín será emitido el día 2026-02-05

5 MUY FUERTE	4 FUERTE	3 NOTABLE	2 LIMITADO	1 DÉBIL

EAWS EUROPEAN AVALANCHE WARNING SERVICES

ICGC Institut Cartogràfic i Geològic de Catalunya

Servei Meteorològic de Catalunya

Boletín de peligro de aludes Prepirineu
Del 04/02/2026 al 05/02/2026

(Válido fuera pistas de esquí y zonas no controladas)

NOTABLE (3) por encima de 2.200 m.
LIMITADO (2) por debajo.

Situación primaria

Nieve venteada

Distribución

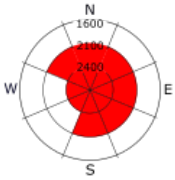

Tamaño

Origen

Tendencia

Situación secundaria

Nieve húmeda

Distribución

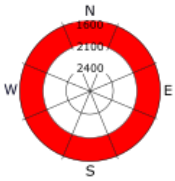

Tamaño

Origen

Tendencia

Estado del manto nivoso

El miércoles se prevén nevadas débiles y viento flojo. El jueves las precipitaciones pueden ser moderadas, con cota de nieve que subirá hacia los 2.000 m en las horas centrales del día, y fuerte viento del W-SW. Las placas viejas formadas el lunes pueden presentarse menos sensibles pero con el nuevo episodio de nieve se formarán de nuevas, sobre todo en cotas altas y orientaciones N y E. Las placas nuevas serán frágiles y podrán romper fácilmente al paso de una persona, generando aludes en general de tamaño medio o pequeño. Localmente, algún alud podría desencadenarse de forma natural.

Por debajo del límite de bosque aproximadamente, el humedecimiento del manto puede provocar caída de bolas y aludes de nieve húmeda de tamaño 1, pequeño, en laderas inclinadas de cualquier orientación, sobre todo a partir de mediodía y por la tarde.

Distribución del manto nivoso

Hay nieve desde 1400-1500 m. El manto es esquiable a partir de 1600 m. Los grosores están alrededor de 100-120 cm a unos 2.200 m; son superiores a los habituales.

Tendencia para las próximas 48-72h

La nubosidad y bajada de temperatura podrá ir estabilizando el manto. Peligro EN DESCENSO.

El próximo boletín será emitido el día 2026-02-05

5 MUY FUERTE	4 FUERTE	3 NOTABLE	2 LIMITADO	1 DÉBIL

EAWS EUROPEAN AVALANCHE WARNING SERVICES

ICGC Institut Cartogràfic i Geològic de Catalunya

Servei Meteorològic de Catalunya meteo.cat

Boletín de peligro de aludes Ter-Freser
Del 04/02/2026 al 05/02/2026

(Válido fuera pistas de esquí y zonas no controladas)

LIMITADO (2)

Situación primaria

Nieve venteada

Distribución

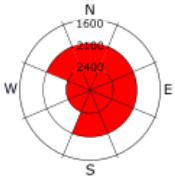

Tamaño

Origen

Tendencia

Estado del manto nivoso

El miércoles se prevén nevadas muy débiles, y el jueves también, con cota de nieve que subirá hacia los 2.000 m en las horas centrales del día, y fuerte viento del W-SW. Las placas viejas serán menos sensibles y se podrán formar nuevas, sobre todo en cotas altas, de pequeño tamaño. Las orientaciones más afectadas serán las N y E.
Es posible actividad de aludes de placa de forma accidental por encima del límite de bosque. Los aludes serán de tamaño 1, pequeño, en caso de que afecten a las placas de nueva formación, y podrán alcanzar tamaño 2, medio, si involucran las placas viejas. Por debajo de unos 2.000 m, el humedecimiento del manto puede provocar caída de purgas húmedas en laderas inclinadas de cualquier orientación.

Distribución del manto nivoso

El manto nivoso presenta grosores muy excedentarios para la época del año. En lugares no afectados por el viento, los espesores oscilan entre 100-140 cm a unos 2.000 m, siendo esquiable a partir de unos 1.500 m.

Tendencia para las próximas 48-72h

La nubosidad y bajada de temperatura podrá ir estabilizando el manto. Peligro EN DESCENSO.

El próximo boletín será emitido el día 2026-02-05

5 MUY FUERTE	4 FUERTE	3 NOTABLE	2 LIMITADO	1 DÉBIL

EAWS EUROPEAN AVALANCHE WARNING SERVICES