MINISTERO DELLA DIFESA

meteomont Servizio Nazionale di previsione neve e valanghe

EAWS EUROPEAN AVALANCHE WARNING SERVICES

CARABINIERI

In collaborazione con: arpav

# DOLOMITI SETTENTRIONALI

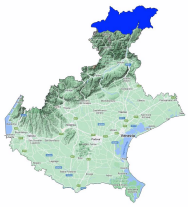

Bollettino Valanghe N. 335/2026 del 04/02/2026 ore 14.00
Validità 48 ore prossima emissione 05/02/2026

**A cura del Servizio METEOMONT dell'ARMA dei CARABINIERI**
**In collaborazione con Servizio Meteorologico dell'Aeronautica militare**

## SITUAZIONE alle 14:00 del 04/02/2026

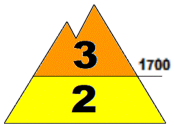


**SITUAZIONE TIPO: neve a debole coesione e vento.**




**SITUAZIONE TIPO: neve a debole coesione e vento.**

| Quota neve (mslm) | Nord | Sud |
|---|---|---|
| | 800 - 900 | 800 - 1000 |

| Altezza Neve (cm) | Neve al suolo | Neve Fresca | Quota (mslm) |
|---|---|---|---|
| | 73 | 05 | 2119 |
| | 58 | 08 | 1530 |

**VALANGHE OSSERVATE: Nessuna valanga.**

## PREVISIONI 05/02/2026

# GRADO DI PERICOLO: MARCATO 3

## SITUAZIONE TIPO: neve a debole coesione e vento.

## SITUAZIONE TIPO: neve a debole coesione e vento.

**MANTO NEVOSO: La stabilità del manto nevoso è molto scarsa su alcuni punti (aree) per tutte le esposizioni al di sopra di 1700 mslm, possibili valanghe di dimensioni medie.**
**La stabilità del manto nevoso è molto scarsa su pochi punti (aree) per tutte le esposizioni al di sotto di 1700 mslm, possibili valanghe di dimensioni medie.**

## AVVERTENZE

In considerazione dei recenti apporti di neve fresca, è richiesta un'ottima valutazione locale della stabilità ed individuazione dell'itinerario.

## SCALA EUROPEA DEL GRADO DI PERICOLO VALANGHE

## LEGENDA PROBLEMA

**Bollettino realizzato su scala sinottica-regionale (standard EAWS). La sua valutazione non può escludere in alcun modo la necessità di una seria e capace valutazione locale del pericolo (singolo pendio) che può essere anche sensibilmente diverso. Le previsioni meteorologiche sono relative all'orario UTC (per l'Italia +1 in inverno e +2 in estate).**

MINISTERO DELLA DIFESA

meteomont
Servizio Nazionale di previsione neve e valanghe

EAWS EUROPEAN AVALANCHE WARNING SERVICES

CARABINIERI

In collaborazione con: arpav

# DOLOMITI SETTENTRIONALI

## PREVISIONE METEO

| Quota | | 05/02/2026 h6:00 | 05/02/2026 h12:00 | 05/02/2026 h18:00 |
|---|---|---|---|---|
| 1000 | Venti | 01 Nodi da Est | 01 Nodi da Sud | 01 Nodi da Sud |
| | Temperature | -01 °C | +00 °C | -01 °C |
| | Temp.percepita | -1 °C | 0 °C | -1 °C |
| 2000 | Venti | 02 Nodi da Est | 01 Nodi da S-Est | 01 Nodi da Sud |
| | Temperature | -02 °C | -01 °C | -02 °C |
| | Temp.percepita | -2 °C | -1 °C | -2 °C |
| 3000 | Venti | 05 Nodi da Est | 01 Nodi da S-Est | 04 Nodi da Ovest |
| | Temperature | -07 °C | -07 °C | -07 °C |
| | Temp.percepita | -11 °C | -7 °C | -11 °C |
| Zero termico | | 1600-1800 m. | 1700-1900 m. | 1600-1800 m. |
| Fenomeno | | | | |
| Stato del cielo | | | | |

## LEGENDA FENOMENI

Assenza Fenomeni · Nebbia · Foschia · Pioggia debole · Pioggia moderata · Pioggia forte · Temporali

Nevicata debole · Nevicata moderata · Nevicata forte

## STATO DEL CIELO

Sereno · Poco nuvoloso · Nuvoloso · Molto nuvoloso · Coperto

## Parametri meteonivometrici registrati presso i campi di rilevamento il 04/02/2026.

| Località | Comune | Quota (m.s.l.m.) | Altezza neve (cm) | Neve caduta nelle 24 ore (cm) | Temp. Min (°C) | Temp. Max (°C) | Condizioni del tempo |
|---|---|---|---|---|---|---|---|
| MISURINA | Auronzo di Cadore (BL) | 1759 | 54 | 4 | -9 | +11 | Nevicata moderata |
| MONTE AGUDO | Auronzo di Cadore (BL) | 1530 | 58 | 8 | -6 | +1 | Nevicata debole continua |
| MONTE FALORIA | Cortina d'Ampezzo (BL) | 2119 | 73 | 5 | -8 | -1 | Assenza di precipitazioni |
| COL DELLA TENDA | Comelico Superiore (BL) | 1930 | 79 | 6 | -5 | 0 | Nevicata debole continua |
| FORCELLA DELLA NEVE * | Auronzo di Cadore (BL) | 2464 | 74 | 2 | -7 | -6 | Nevicata moderata |

(*) Rilievi fuori campo

**L'INFORMAZIONE E' PREVENZIONE - LEGGI L'ATTUALE GRADO DI PERICOLO VALANGHE!**

IL CAPO DEL CENTRO NAZIONALE METEOMONT
(Ten. Col. RFI Emanuela Gini)
FIRMA AUTOGRAFA OMESSA AI SENSI
DELL'ART.3 DEL D.LGS N.39/1993

Bollettino realizzato su scala sinottica-regionale (standard EAWS). La sua valutazione non può escludere in alcun modo la necessità di una seria e capace valutazione locale del pericolo (singolo pendio) che può essere anche sensibilmente diverso. Le previsioni meteorologiche sono relative all'orario UTC (per l'Italia +1 in inverno e +2 in estate).