MINISTERO DELLA DIFESA

meteomont Servizio Nazionale di previsione neve e valanghe

EAWS EUROPEAN AVALANCHE WARNING SERVICES

CARABINIERI

AERONAUTICA MILITARE SERVIZIO METEOROLOGICO

PREALPI LOMBARDE

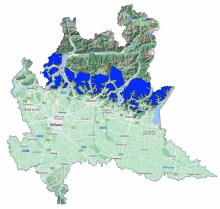

Bollettino Valanghe N. 334/2026 del 04/02/2026 ore 14.00
Validità 48 ore prossima emissione 05/02/2026

A cura del Servizio METEOMONT dell'ARMA dei CARABINIERI
In collaborazione con Servizio Meteorologico dell'Aeronautica militare

SITUAZIONE alle 14:00 del 04/02/2026

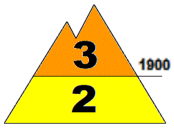

SITUAZIONE TIPO: brina di superficie sepolta.



SITUAZIONE TIPO: strato debole persistente basale.

Quota neve (mslm)	Nord	Sud
	400	400

Altezza Neve (cm)	Neve al suolo	Neve Fresca	Quota (mslm)
	50-70	6	2000
	55-95	5	1750

VALANGHE OSSERVATE: -.

PREVISIONI 05/02/2026

GRADO DI PERICOLO: MARCATO 3

SITUAZIONE TIPO: brina di superficie sepolta.

SITUAZIONE TIPO: brina di superficie sepolta.

MANTO NEVOSO: La stabilità del manto nevoso è molto scarsa su molti punti (aree) per tutte le esposizioni al di sopra di 1900 mslm, possibili valanghe di dimensioni medie.
La stabilità del manto nevoso è scarsa su alcuni punti (aree) per versanti da ovest a est al di sotto di 1900 mslm, possibili valanghe di dimensioni medie.

AVVERTENZE

Viste le condizioni del manto nevoso, le attività al di fuori delle piste battute e segnalate richiedono ottime capacità di valutazione del pericolo locale.

SCALA EUROPEA DEL GRADO DI PERICOLO VALANGHE

LEGENDA PROBLEMA

Bollettino realizzato su scala sinottica-regionale (standard EAWS). La sua valutazione non può escludere in alcun modo la necessità di una seria e capace valutazione locale del pericolo (singolo pendio) che può essere anche sensibilmente diverso. Le previsioni meteorologiche sono relative all'orario UTC (per l'Italia +1 in inverno e +2 in estate).

MINISTERO DELLA DIFESA

meteomont
Servizio Nazionale di previsione neve e valanghe

EAWS EUROPEAN AVALANCHE WARNING SERVICES

CARABINIERI

PREALPI LOMBARDE

PREVISIONE METEO

Quota		05/02/2026 h6:00	05/02/2026 h12:00	05/02/2026 h18:00
1000	Venti	01 nodi da N-Ovest	01 Nodi da Sud	02 Nodi da Sud
	Temperature	+00 °C	+00 °C	+01 °C
	Temp.percepita	0 °C	0 °C	1 °C
2000	Venti	03 nodi da N-Ovest	01 Nodi da S-Ovest	02 Nodi da S-Ovest
	Temperature	-01 °C	-01 °C	-01 °C
	Temp.percepita	-3 °C	-1 °C	-1 °C
3000	Venti	04 Nodi da Nord	02 nodi da N-Ovest	05 Nodi da S-Ovest
	Temperature	-07 °C	-07 °C	-07 °C
	Temp.percepita	-11 °C	-7 °C	-11 °C
Zero termico		1700-1900 m.	1700-1900 m.	1500-1700 m.
Fenomeno		—	—	—
Stato del cielo				

LEGENDA FENOMENI

— Assenza Fenomeni · Nebbia · Foschia · Pioggia debole · Pioggia moderata · Pioggia forte · Temporali

Nevicata debole · Nevicata moderata · Nevicata forte

STATO DEL CIELO

Sereno · Poco nuvoloso · Nuvoloso · Molto nuvoloso · Coperto

Parametri meteonivometrici registrati presso i campi di rilevamento il 04/02/2026.

Località	Comune	Quota (m.s.l.m.)	Altezza neve (cm)	Neve caduta nelle 24 ore (cm)	Temp. Min (°C)	Temp. Max (°C)	Condizioni del tempo
PIANI DI BOBBIO	Barzio (LC)	1724	95	N.P.	-3	0	Precipitazioni all'orizzonte (pioggia, neve, grandine, temporali) ma non sulla stazione
PIAN DELLE BETULLE	Margno (LC)	1445	38	2	-4	+2	Nevicata debole continua

(*) Rilievi fuori campo

L'INFORMAZIONE E' PREVENZIONE - LEGGI L'ATTUALE GRADO DI PERICOLO VALANGHE!

IL CAPO DEL CENTRO NAZIONALE METEOMONT
(Ten. Col. RFI Emanuela Gini)
FIRMA AUTOGRAFA OMESSA AI SENSI
DELL'ART.3 DEL D.LGS N.39/1993

Bollettino realizzato su scala sinottica-regionale (standard EAWS). La sua valutazione non può escludere in alcun modo la necessità di una seria e capace valutazione locale del pericolo (singolo pendio) che può essere anche sensibilmente diverso. Le previsioni meteorologiche sono relative all'orario UTC (per l'Italia +1 in inverno e +2 in estate).