MINISTERO DELLA DIFESA

meteomont
Servizio Nazionale di previsione neve e valanghe

EAWS EUROPEAN AVALANCHE WARNING SERVICES

CARABINIERI

AERONAUTICA MILITARE SERVIZIO METEOROLOGICO

## ALPI PENNINE

Bollettino Valanghe N. 336/2026 del 04/02/2026 ore 14.00
Validità 48 ore prossima emissione 05/02/2026

**A cura del Servizio METEOMONT dell'ARMA dei CARABINIERI**
**In collaborazione con Servizio Meteorologico dell'Aeronautica militare**

## SITUAZIONE alle 14:00 del 04/02/2026

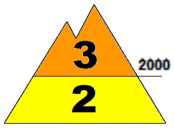


**SITUAZIONE TIPO: neve a debole coesione e vento.**




**SITUAZIONE TIPO: nessuna situazione tipo evidente.**

| Quota neve (mslm) | Nord | Sud |
|---|---|---|
| | 600 | 600 |

| Altezza Neve (cm) | Neve al suolo | Neve Fresca | Quota (mslm) |
|---|---|---|---|
| | 086 | 005 | 2820 |
| | 064 | 001 | 1360 |

**VALANGHE OSSERVATE: -.**

## PREVISIONI 05/02/2026

# GRADO DI PERICOLO: MARCATO 3

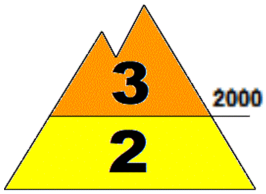


## SITUAZIONE TIPO: neve a debole coesione e vento.

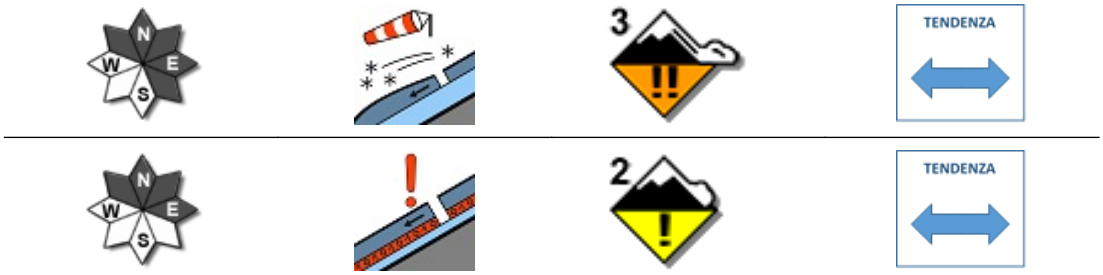


## SITUAZIONE TIPO: nessuna situazione tipo evidente.

**MANTO NEVOSO: La stabilità del manto nevoso è scarsa su molti punti (aree) per versanti da nord ovest a sud est compresi al di sopra di 2000 mslm, possibili valanghe di dimensioni medie.**
**La stabilità del manto nevoso è scarsa su alcuni punti (aree) per versanti in ombra al di sotto di 2000 mslm, possibili valanghe di dimensioni medie.**

## AVVERTENZE

A seguito dell'attività eolica registrata sono da evitare le zone di accumulo, conche, canaloni, cambi di pendenza e pendii sotto vento in genere.

## SCALA EUROPEA DEL GRADO DI PERICOLO VALANGHE

## LEGENDA PROBLEMA

**Bollettino realizzato su scala sinottica-regionale (standard EAWS). La sua valutazione non può escludere in alcun modo la necessità di una seria e capace valutazione locale del pericolo (singolo pendio) che può essere anche sensibilmente diverso. Le previsioni meteorologiche sono relative all'orario UTC (per l'Italia +1 in inverno e +2 in estate).**

# ALPI PENNINE

## PREVISIONE METEO

| Quota | | 05/02/2026 h6:00 | 05/02/2026 h12:00 | 05/02/2026 h18:00 |
|---|---|---|---|---|
| 1000 | Venti | 03 nodi da N-Ovest | 00 Calma | 01 Nodi da Nord |
| | Temperature | +00 °C | +02 °C | +01 °C |
| | Temp.percepita | -2 °C | 2 °C | 1 °C |
| 2000 | Venti | 02 nodi da N-Ovest | 01 Nodi da Ovest | 02 Nodi da Sud |
| | Temperature | +00 °C | +00 °C | -01 °C |
| | Temp.percepita | 0 °C | 0 °C | -1 °C |
| 3000 | Venti | 04 nodi da N-Ovest | 04 nodi da Ovest | 05 Nodi da S-Ovest |
| | Temperature | -07 °C | -07 °C | -06 °C |
| | Temp.percepita | -11 °C | -11 °C | -10 °C |
| Zero termico | | 1800-2000 m. | 1900-2100 m. | 1100-1300 m. |
| Fenomeno | | — | — | — |
| Stato del cielo | | | | |

## LEGENDA FENOMENI

— Assenza Fenomeni · Nebbia · Foschia · Pioggia debole · Pioggia moderata · Pioggia forte · Temporali

Nevicata debole · Nevicata moderata · Nevicata forte

## STATO DEL CIELO

Sereno · Poco nuvoloso · Nuvoloso · Molto nuvoloso · Coperto

## Parametri meteonivometrici registrati presso i campi di rilevamento il 04/02/2026.

| Località | Comune | Quota (m.s.l.m.) | Altezza neve (cm) | Neve caduta nelle 24 ore (cm) | Temp. Min (°C) | Temp. Max (°C) | Condizioni del tempo |
|---|---|---|---|---|---|---|---|
| ALPE LUSENTINO * | Domodossola (VB) | 1138 | 37 | 4 | N.P. | N.P. | Pioggia debole intermittente |
| OPACO DI PECETTO | Macugnaga (VB) | 1330 | 70 | 1 | N.P. | N.P. | Nevicata debole intermittente |
| PIANALUNGA | Alagna Valsesia (VC) | 2025 | 84 | 12 | -7 | -4 | Nevicata debole continua |

**(*) Rilievi fuori campo**

**L'INFORMAZIONE E' PREVENZIONE - LEGGI L'ATTUALE GRADO DI PERICOLO VALANGHE!**

**IL CAPO DEL CENTRO NAZIONALE METEOMONT**
**(Ten. Col. RFI Emanuela Gini)**
**FIRMA AUTOGRAFA OMESSA AI SENSI**
**DELL'ART.3 DEL D.LGS N.39/1993**

**Bollettino realizzato su scala sinottica-regionale (standard EAWS). La sua valutazione non può escludere in alcun modo la necessità di una seria e capace valutazione locale del pericolo (singolo pendio) che può essere anche sensibilmente diverso. Le previsioni meteorologiche sono relative all'orario UTC (per l'Italia +1 in inverno e +2 in estate).**