MINISTERO DELLA DIFESA

meteomont Servizio Nazionale di previsione neve e valanghe

EAWS EUROPEAN AVALANCHE WARNING SERVICES

CARABINIERI

In collaborazione con: MARCHE

APPENNINO UMBRO-MARCHIG. MERID. - MONTI SIBILLINI

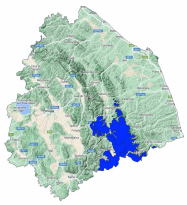

Bollettino Valanghe N. 289/2026 del 04/02/2026 ore 14.00
Validità 48 ore prossima emissione 05/02/2026

A cura del Servizio METEOMONT dell'ARMA dei CARABINIERI
In collaborazione con Servizio Meteorologico dell'Aeronautica militare

SITUAZIONE alle 14:00 del 04/02/2026

SITUAZIONE TIPO: pioggia su neve.

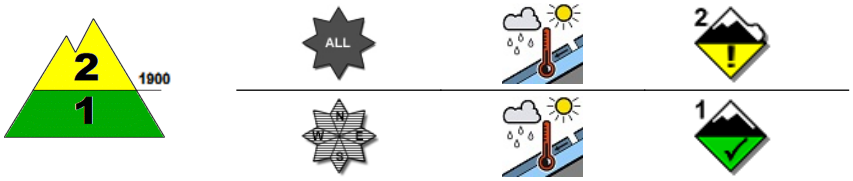

SITUAZIONE TIPO: pioggia su neve.

Quota neve (mslm)	Nord	Sud
	1400	1700

Altezza Neve (cm)	Neve al suolo	Neve Fresca	Quota (mslm)
	80-120	000	2100
	20 -30	000	1700

VALANGHE OSSERVATE: Valanghe di piccole dimensioni, Valanghe di neve a debole coesione di superficie.

PREVISIONI 05/02/2026

GRADO DI PERICOLO: MODERATO 2

SITUAZIONE TIPO: situazione primaverile.



SITUAZIONE TIPO: pioggia su neve.

MANTO NEVOSO: La stabilità del manto nevoso è discreta su alcuni punti (aree) per tutte le esposizioni al di sopra di 1800 mslm, possibili valanghe di dimensioni medie.
La stabilità del manto nevoso è discreta su pochi punti (aree) per isolati pendii al di sotto di 1800 mslm, possibili valanghe di dimensioni piccole.

AVVERTENZE

Meteomont ricorda ARTVA, pala e sonda sempre al seguito.

SCALA EUROPEA DEL GRADO DI PERICOLO VALANGHE

5 - MOLTO FORTE | 4 - FORTE | 3 - MARCATO | 2 - MODERATO | 1 - DEBOLE | NO NEVE | NO INFO

LEGENDA PROBLEMA

NEVE FRESCA | LASTRONI DA VENTO | STRATI DEBOLI PERSISTENTI | NEVE BAGNATA | SLITTAMENTO | CORNICI | NESSUN PROBLEMA VALANGHIVO EVIDENTE | NO_INFO

Bollettino realizzato su scala sinottica-regionale (standard EAWS). La sua valutazione non può escludere in alcun modo la necessità di una seria e capace valutazione locale del pericolo (singolo pendio) che può essere anche sensibilmente diverso. Le previsioni meteorologiche sono relative all'orario UTC (per l'Italia +1 in inverno e +2 in estate).

MINISTERO DELLA DIFESA

meteomont
Servizio Nazionale di previsione neve e valanghe

EAWS EUROPEAN AVALANCHE WARNING SERVICES

CARABINIERI

In collaborazione con: MARCHE

APPENNINO UMBRO-MARCHIG. MERID. - MONTI SIBILLINI

PREVISIONE METEO

Quota		05/02/2026 h6:00	05/02/2026 h12:00	05/02/2026 h18:00
1000	Venti	06 Nodi da Ovest	07 Nodi da Ovest	04 Nodi da Ovest
	Temperature	+00 °C	+01 °C	+02 °C
	Temp.percepita	-4 °C	-3 °C	-0 °C
2000	Venti	15 Nodi da Ovest	19 Nodi da Ovest	09 Nodi da Ovest
	Temperature	-04 °C	-03 °C	-02 °C
	Temp.percepita	-11 °C	-11 °C	-7 °C
3000	Venti	19 Nodi da Ovest	17 Nodi da Ovest	16 nodi da N-Ovest
	Temperature	-07 °C	-05 °C	-03 °C
	Temp.percepita	-16 °C	-13 °C	-10 °C
Zero termico		1400-1600 m.	1500-1700 m.	1700-1900 m.
Fenomeno			—	—
Stato del cielo				

LEGENDA FENOMENI

— Assenza Fenomeni · Nebbia · Foschia · Pioggia debole · Pioggia moderata · Pioggia forte · Temporali

Nevicata debole · Nevicata moderata · Nevicata forte

STATO DEL CIELO

Sereno · Poco nuvoloso · Nuvoloso · Molto nuvoloso · Coperto

Parametri meteonivometrici registrati presso i campi di rilevamento il 04/02/2026.

Località	Comune	Quota (m.s.l.m.)	Altezza neve (cm)	Neve caduta nelle 24 ore (cm)	Temp. Min (°C)	Temp. Max (°C)	Condizioni del tempo
FORCA DI GUALDO	Castelsantangelo sul Nera (MC)	1496	25 cm di neve fresca mista a pioggia	Pioggia e assenza di neve	+2	+5	Pioggia debole intermittente
LA VALLETTA	Bolognola (MC)	1352	0	0	+1	+7	Pioggia debole continua
COLLE	Montegallo (AP)	1036	0	0	+3	+11	Pioggia debole continua
PARCO GUARNIERI	Montemonaco (AP)	980	0	0	+4	+12	Pioggia debole intermittente
FRONTIGNANO *	Castelsantangelo sul Nera (MC)	1703	14	0	-2	+8	Pioggia mista a neve
MONTE PRATA *	Castelsantangelo sul Nera (MC)	1750	41	N.P.	N.P.	N.P.	Assenza di precipitazioni

(*) Rilievi fuori campo

L'INFORMAZIONE E' PREVENZIONE - LEGGI L'ATTUALE GRADO DI PERICOLO VALANGHE!

IL CAPO DEL CENTRO NAZIONALE METEOMONT
(Ten. Col. RFI Emanuela Gini)
FIRMA AUTOGRAFA OMESSA AI SENSI
DELL'ART.3 DEL D.LGS N.39/1993

Bollettino realizzato su scala sinottica-regionale (standard EAWS). La sua valutazione non può escludere in alcun modo la necessità di una seria e capace valutazione locale del pericolo (singolo pendio) che può essere anche sensibilmente diverso. Le previsioni meteorologiche sono relative all'orario UTC (per l'Italia +1 in inverno e +2 in estate).