MINISTERO DELLA DIFESA

meteomont
Servizio Nazionale di previsione neve e valanghe

EAWS EUROPEAN AVALANCHE WARNING SERVICES

CARABINIERI

GRAN SASSO EST - LAGA EST

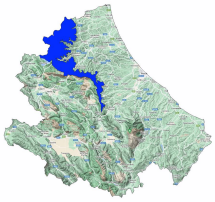

Bollettino Valanghe N. 323/2026 del 03/02/2026 ore 14.00
Validità 48 ore prossima emissione 04/02/2026

A cura del Servizio METEOMONT dell'ARMA dei CARABINIERI
In collaborazione con Servizio Meteorologico dell'Aeronautica militare

SITUAZIONE alle 14:00 del 03/02/2026

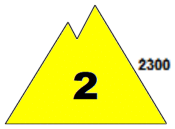

SITUAZIONE TIPO: passaggio da poca a molta neve.



SITUAZIONE TIPO: situazione primaverile.

Quota neve (mslm)	Nord	Sud
	1100 - 1400	1100 - 1500

Altezza Neve (cm)	Neve al suolo	Neve Fresca	Quota (mslm)
	019	000	1497
	016	000	1355

VALANGHE OSSERVATE: Nessuna valanga.

PREVISIONI 04/02/2026

GRADO DI PERICOLO: MODERATO 2

SITUAZIONE TIPO: passaggio da poca a molta neve.

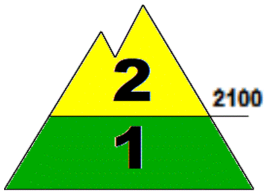

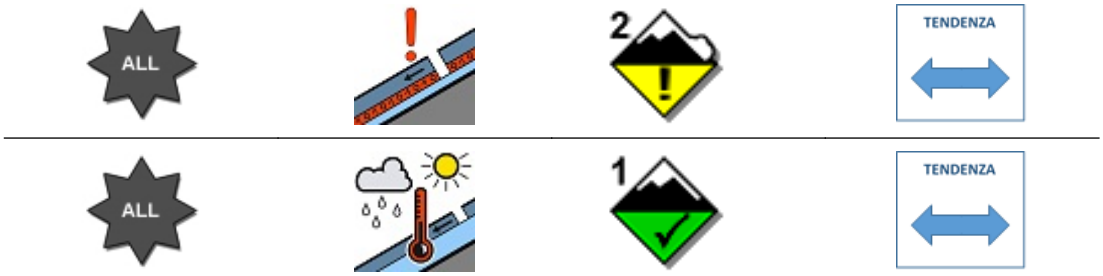

SITUAZIONE TIPO: situazione primaverile.

MANTO NEVOSO: La stabilità del manto nevoso è scarsa su pochi punti (aree) per tutte le esposizioni al di sopra di 2100 mslm, possibili valanghe di dimensioni grandi.
La stabilità del manto nevoso è discreta su pochi punti (aree) per tutte le esposizioni al di sotto di 2100 mslm, possibili valanghe di dimensioni medie.

AVVERTENZE

Attenzione alla presenza di accumuli eolici di difficile individuazione.

SCALA EUROPEA DEL GRADO DI PERICOLO VALANGHE

LEGENDA PROBLEMA

Bollettino realizzato su scala sinottica-regionale (standard EAWS). La sua valutazione non può escludere in alcun modo la necessità di una seria e capace valutazione locale del pericolo (singolo pendio) che può essere anche sensibilmente diverso. Le previsioni meteorologiche sono relative all'orario UTC (per l'Italia +1 in inverno e +2 in estate).

MINISTERO DELLA DIFESA

meteomont
Servizio Nazionale di previsione neve e valanghe

EAWS EUROPEAN AVALANCHE WARNING SERVICES

CARABINIERI

GRAN SASSO EST - LAGA EST

PREVISIONE METEO

Quota		04/02/2026 h6:00	04/02/2026 h12:00	04/02/2026 h18:00
1000	Venti	04 Nodi da Sud	03 Nodi da Sud	04 Nodi da S-Ovest
	Temperature	+03 °C	+04 °C	+02 °C
	Temp.percepita	1 °C	3 °C	-0 °C
2000	Venti	14 Nodi da Sud	09 Nodi da Sud	10 Nodi da Ovest
	Temperature	+00 °C	+00 °C	-03 °C
	Temp.percepita	-6 °C	-5 °C	-9 °C
3000	Venti	23 Nodi da Sud	12 Nodi da Sud	12 Nodi da Ovest
	Temperature	-04 °C	-06 °C	-06 °C
	Temp.percepita	-13 °C	-13 °C	-13 °C
Zero termico		1900-2100 m.	1900-2100 m.	1500-1700 m.
Fenomeno		—		
Stato del cielo				

LEGENDA FENOMENI

— Assenza Fenomeni · Nebbia · Foschia · Pioggia debole · Pioggia moderata · Pioggia forte · Temporali

Nevicata debole · Nevicata moderata · Nevicata forte

STATO DEL CIELO

Sereno · Poco nuvoloso · Nuvoloso · Molto nuvoloso · Coperto

Parametri meteonivometrici registrati presso i campi di rilevamento il 03/02/2026.

Località	Comune	Quota (m.s.l.m.)	Altezza neve (cm)	Neve caduta nelle 24 ore (cm)	Temp. Min (°C)	Temp. Max (°C)	Condizioni del tempo
FAVACCHIOLE	Crognaleto (TE)	1016	0	0	-2	+8	Assenza di precipitazioni
PRATO SELVA	Fano Adriano (TE)	1355	16	0	0	+8	Assenza di precipitazioni
PIANO SAN PIETRO	Isola del Gran Sasso d'Italia (TE)	950	0	0	N.P.	N.P.	Assenza di precipitazioni
PRATI DI TIVO	Pietracamela (TE)	1380	31	0	-2	+9	Assenza di precipitazioni
SANT' EGIDIO *	Rocca Santa Maria (TE)	1497	19	0	-3	+6	Assenza di precipitazioni
SAN PAOLO	Acquasanta Terme (AP)	960	0	0	-2	+9	Assenza di precipitazioni
COLLE SAN GIACOMO	Civitella del Tronto (TE)	1075	0	0	-1	+9	Assenza di precipitazioni

(*) Rilievi fuori campo

L'INFORMAZIONE E' PREVENZIONE - LEGGI L'ATTUALE GRADO DI PERICOLO VALANGHE!

IL CAPO DEL CENTRO NAZIONALE METEOMONT
(Ten. Col. RFI Emanuela Gini)
FIRMA AUTOGRAFA OMESSA AI SENSI
DELL'ART.3 DEL D.LGS N.39/1993

Bollettino realizzato su scala sinottica-regionale (standard EAWS). La sua valutazione non può escludere in alcun modo la necessità di una seria e capace valutazione locale del pericolo (singolo pendio) che può essere anche sensibilmente diverso. Le previsioni meteorologiche sono relative all'orario UTC (per l'Italia +1 in inverno e +2 in estate).