# GRAN SASSO EST - LAGA EST

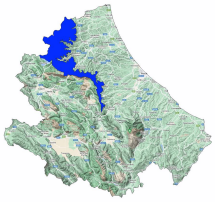

Bollettino Valanghe N. 324/2026 del 04/02/2026 ore 14.00
Validità 48 ore prossima emissione 05/02/2026

**A cura del Servizio METEOMONT dell'ARMA dei CARABINIERI**
**In collaborazione con Servizio Meteorologico dell'Aeronautica militare**

## SITUAZIONE alle 14:00 del 04/02/2026

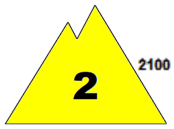


**SITUAZIONE TIPO: passaggio da poca a molta neve.**




**SITUAZIONE TIPO: pioggia su neve.**

| Quota neve (mslm) | Nord | Sud |
|---|---|---|
| | 1300 - 1400 | 1400 - 1500 |

| Altezza Neve (cm) | Neve al suolo | Neve Fresca | Quota (mslm) |
|---|---|---|---|
| | 062 | 000 | 1915 |
| | 021 | 000 | 1380 |

**VALANGHE OSSERVATE: Nessuna valanga.**

## PREVISIONI 05/02/2026

## GRADO DI PERICOLO: MODERATO 2

## SITUAZIONE TIPO: passaggio da poca a molta neve.

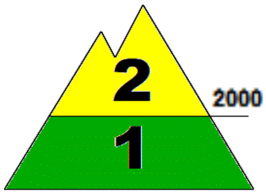


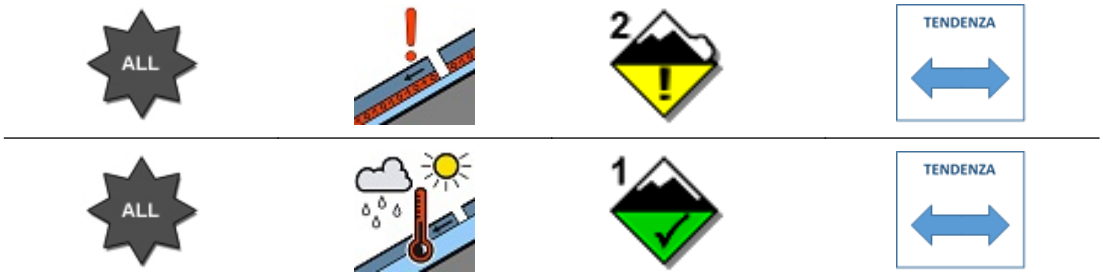


## SITUAZIONE TIPO: situazione primaverile.

**MANTO NEVOSO: La stabilità del manto nevoso è discreta su alcuni punti (aree) per tutte le esposizioni al di sopra di 2000 mslm, possibili valanghe di dimensioni medie.**
**La stabilità del manto nevoso è discreta su pochi punti (aree) per tutte le esposizioni al di sotto di 2000 mslm, possibili valanghe di dimensioni medie.**

## AVVERTENZE

In considerazione delle avverse condizioni meteorologiche in atto, e della scarsa visibilità, risulterà difficoltosa l'individuazione dell'itinerario e della valutazione del singolo pendio.

## SCALA EUROPEA DEL GRADO DI PERICOLO VALANGHE

## LEGENDA PROBLEMA

**Bollettino realizzato su scala sinottica-regionale (standard EAWS). La sua valutazione non può escludere in alcun modo la necessità di una seria e capace valutazione locale del pericolo (singolo pendio) che può essere anche sensibilmente diverso. Le previsioni meteorologiche sono relative all'orario UTC (per l'Italia +1 in inverno e +2 in estate).**

MINISTERO DELLA DIFESA

meteomont
Servizio Nazionale di previsione neve e valanghe

EAWS EUROPEAN AVALANCHE WARNING SERVICES

CARABINIERI

# GRAN SASSO EST - LAGA EST

## PREVISIONE METEO

| Quota | | 05/02/2026 h6:00 | 05/02/2026 h12:00 | 05/02/2026 h18:00 |
|---|---|---|---|---|
| 1000 | Venti | 05 Nodi da Ovest | 06 Nodi da Ovest | 04 Nodi da S-Ovest |
| | Temperature | +00 °C | +02 °C | +02 °C |
| | Temp.percepita | -3 °C | -1 °C | -0 °C |
| 2000 | Venti | 14 nodi da Ovest | 15 Nodi da Ovest | 11 Nodi da Ovest |
| | Temperature | -03 °C | -03 °C | -02 °C |
| | Temp.percepita | -10 °C | -10 °C | -8 °C |
| 3000 | Venti | 15 Nodi da Ovest | 16 Nodi da Ovest | 17 nodi da N-Ovest |
| | Temperature | -08 °C | -09 °C | -04 °C |
| | Temp.percepita | -17 °C | -18 °C | -12 °C |
| Zero termico | | 1400-1600 m. | 1500-1700 m. | 1600-1800 m. |
| Fenomeno | | | — | — |
| Stato del cielo | | | | |

## LEGENDA FENOMENI

— Assenza Fenomeni · Nebbia · Foschia · Pioggia debole · Pioggia moderata · Pioggia forte · Temporali

Nevicata debole · Nevicata moderata · Nevicata forte

## STATO DEL CIELO

Sereno · Poco nuvoloso · Nuvoloso · Molto nuvoloso · Coperto

## Parametri meteonivometrici registrati presso i campi di rilevamento il 04/02/2026.

| Località | Comune | Quota (m.s.l.m.) | Altezza neve (cm) | Neve caduta nelle 24 ore (cm) | Temp. Min (°C) | Temp. Max (°C) | Condizioni del tempo |
|---|---|---|---|---|---|---|---|
| FAVACCHIOLE | Crognaleto (TE) | 1016 | 0 | 0 | +5 | +10 | Pioggia debole intermittente |
| PRATO SELVA | Fano Adriano (TE) | 1355 | 0 | 0 | +3 | +9 | Nebbia con cielo non visibile |
| RIGOPIANO | Farindola (PE) | 1135 | 0 | 0 | -1 | +5 | Nebbia con cielo non visibile |
| PIANO SAN PIETRO | Isola del Gran Sasso d'Italia (TE) | 950 | 0 | 0 | N.P. | N.P. | Assenza di precipitazioni |
| PRATI DI TIVO | Pietracamela (TE) | 1380 | 21 | 0 | +2 | +10 | Nebbia con cielo non visibile |
| CEPPO | Rocca Santa Maria (TE) | 1349 | Tracce di neve | 0 | +4 | +10 | Pioggia debole intermittente |
| SAN PAOLO | Acquasanta Terme (AP) | 960 | 0 | 0 | +4 | +14 | Pioggia debole intermittente |
| COLLE SAN GIACOMO | Civitella del Tronto (TE) | 1075 | 0 | 0 | 0 | +6 | Pioggia debole intermittente |
| COLLE DELL'ASINO * | Pietracamela (TE) | 1915 | 62 | 0 | N.P. | N.P. | Assenza di precipitazioni |

(*) Rilievi fuori campo

**L'INFORMAZIONE E' PREVENZIONE - LEGGI L'ATTUALE GRADO DI PERICOLO VALANGHE!**

IL CAPO DEL CENTRO NAZIONALE METEOMONT
(Ten. Col. RFI Emanuela Gini)
FIRMA AUTOGRAFA OMESSA AI SENSI
DELL'ART.3 DEL D.LGS N.39/1993

Bollettino realizzato su scala sinottica-regionale (standard EAWS). La sua valutazione non può escludere in alcun modo la necessità di una seria e capace valutazione locale del pericolo (singolo pendio) che può essere anche sensibilmente diverso. Le previsioni meteorologiche sono relative all'orario UTC (per l'Italia +1 in inverno e +2 in estate).