MINISTERO DELLA DIFESA

meteomont Servizio Nazionale di previsione neve e valanghe

EAWS EUROPEAN AVALANCHE WARNING SERVICES

CARABINIERI

TERMINILLO MONTI REATINI E LAGA OVEST

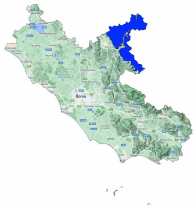

Bollettino Valanghe N. 277/2026 del 04/02/2026 ore 14.00
Validità 48 ore prossima emissione 05/02/2026

A cura del Servizio METEOMONT dell'ARMA dei CARABINIERI
In collaborazione con Servizio Meteorologico dell'Aeronautica militare

SITUAZIONE alle 14:00 del 04/02/2026

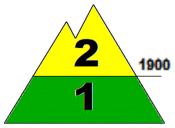

SITUAZIONE TIPO: neve a debole coesione e vento.



SITUAZIONE TIPO: pioggia su neve.

	Nord	Sud
Quota neve (mslm)	*1400 - 1500*	*1700*

	Neve al suolo	Neve Fresca	Quota (mslm)
Altezza Neve (cm)	*044*	*000*	*1748*
	020	*000*	*1350*

VALANGHE OSSERVATE: Nessuna valanga.

PREVISIONI 05/02/2026

GRADO DI PERICOLO: MODERATO 2

SITUAZIONE TIPO: neve a debole coesione e vento.

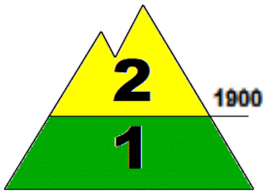

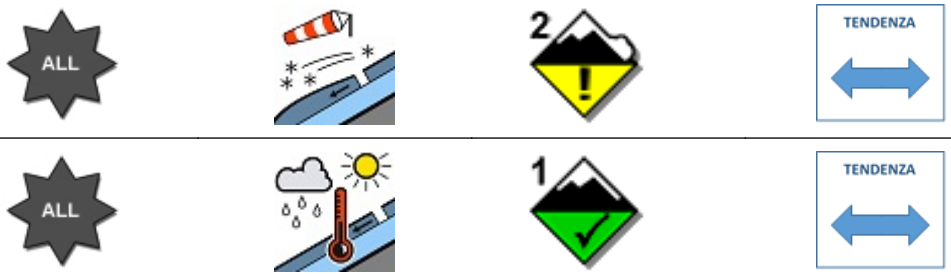

SITUAZIONE TIPO: pioggia su neve.

MANTO NEVOSO: La stabilità del manto nevoso è scarsa su alcuni punti (aree) per tutte le esposizioni al di sopra di 1900 mslm, possibili valanghe di dimensioni medie.
La stabilità del manto nevoso è discreta su alcuni punti (aree) per tutte le esposizioni al di sotto di 1900 mslm, possibili valanghe di dimensioni piccole.

AVVERTENZE

In considerazione delle avverse condizioni meteorologiche previste, le attività al di fuori delle piste battute e segnalate sono limitate. Se effettuate, richiedono ottime capacità di valutazione del pericolo locale.

SCALA EUROPEA DEL GRADO DI PERICOLO VALANGHE

LEGENDA PROBLEMA

Bollettino realizzato su scala sinottica-regionale (standard EAWS). La sua valutazione non può escludere in alcun modo la necessità di una seria e capace valutazione locale del pericolo (singolo pendio) che può essere anche sensibilmente diverso. Le previsioni meteorologiche sono relative all'orario UTC (per l'Italia +1 in inverno e +2 in estate).

MINISTERO DELLA DIFESA

meteomont
Servizio Nazionale di previsione neve e valanghe

EAWS EUROPEAN AVALANCHE WARNING SERVICES

CARABINIERI

TERMINILLO MONTI REATINI E LAGA OVEST

PREVISIONE METEO

Quota		05/02/2026 h6:00	05/02/2026 h12:00	05/02/2026 h18:00
1000	Venti	04 Nodi da Ovest	04 Nodi da S-Ovest	03 Nodi da S-Ovest
	Temperature	+00 °C	+01 °C	+02 °C
	Temp.percepita	-3 °C	-1 °C	0 °C
2000	Venti	13 nodi da N-Ovest	12 Nodi da Ovest	08 Nodi da S-Ovest
	Temperature	-03 °C	-03 °C	-02 °C
	Temp.percepita	-10 °C	-9 °C	-7 °C
3000	Venti	15 nodi da Ovest	15 Nodi da Ovest	16 nodi da N-Ovest
	Temperature	-08 °C	-08 °C	-05 °C
	Temp.percepita	-17 °C	-17 °C	-13 °C
Zero termico		1300-1500 m.	1500-1700 m.	1600-1800 m.
Fenomeno				—
Stato del cielo				

LEGENDA FENOMENI

— Assenza Fenomeni · Nebbia · Foschia · Pioggia debole · Pioggia moderata · Pioggia forte · Temporali

Nevicata debole · Nevicata moderata · Nevicata forte

STATO DEL CIELO

Sereno · Poco nuvoloso · Nuvoloso · Molto nuvoloso · Coperto

Parametri meteonivometrici registrati presso i campi di rilevamento il 04/02/2026.

Località	Comune	Quota (m.s.l.m.)	Altezza neve (cm)	Neve caduta nelle 24 ore (cm)	Temp. Min (°C)	Temp. Max (°C)	Condizioni del tempo
PESCHIERE	Amatrice (RI)	1270	0	0	+3	+9	Pioggia moderata
M. CAIDURO	Cittareale (RI)	1300	10	0	+3	+7	Pioggia moderata
VALLONINA	Leonessa (RI)	1350	20	0	+2	+6	Pioggia moderata
ANELLO DI CAMPOFOROGNA - VILLA CLHIGI *	Rieti (RI)	1748	44	Tracce di neve	0	+2	Nevicata moderata

(*) Rilievi fuori campo

L'INFORMAZIONE E' PREVENZIONE - LEGGI L'ATTUALE GRADO DI PERICOLO VALANGHE!

IL CAPO DEL CENTRO NAZIONALE METEOMONT
(Ten. Col. RFI Emanuela Gini)
FIRMA AUTOGRAFA OMESSA AI SENSI
DELL'ART.3 DEL D.LGS N.39/1993