Bulletin d'estimation du risque d'avalanche

(valable en dehors des pistes balisées et ouvertes)

MASSIF : Cinto Rotondo

Rédigé le mercredi 4 février 2026 à 15h

Estimation des risques pour le : JEUDI 05 FÉVRIER

PERSISTANCE DE NOMBREUSES PLAQUES ÉPAISSES EN ALTITUDE

3

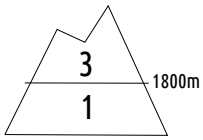

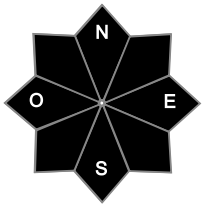

Au-dessus de 1800m indice de risque marqué, plus bas indice faible.

Départs spontanés : Rares coulées ou avalanches superficielles dans les pentes raides

Déclenchements provoqués : Au-dessus de 1800m, persistance de nombreuses plaques, épaisses, assez faciles à déclencher, en toutes orientations

Indices de risque : 5 très fort - 4 fort - 3 marqué - 2 limité - 1 faible -- En noir : les pentes les plus dangereuses

Stabilité du manteau neigeux

Situation avalancheuse typique : neige ventée couche fragile persistante

Déclenchements provoqués : Au-dessus de 1800 m le manteau neigeux est constitué d'un empilement de couches de neige ventée et non ventée avec de nombreuses couches fragiles (neige froide des derniers jours, présence de neige roulée et vieille neige sans cohésion plus enfouie). Ces plaques en place dans l'épaisse couche de neige récente sont présentes en toutes orientations, d'autant plus nombreuses en versants ombragés, situées parfois loin des crêtes. Elles sont souvent friables à l'abri du vent, plutôt dures dans les secteurs ventés. Faciles à déclencher par un seul skieur, elles génèrent des avalanches de taille moyenne à grande. En orientation Est à Nord d'altitude supérieure à 2000/2200 m, une avalanche de très grande taille n'est pas exclue, par sollicitation de couches fragiles enfouies. Le tassement des couches permet un début de stabilisation. Sous 1800 m, les plaques sont plus rares, peu épaisses et généralement plus difficiles à solliciter.

Départs spontanés : Avec les précipitations attendues mercredi tôt en matinée, on attend quelques coulées ou avalanches superficielles, localisées dans les pentes raides en neige récente sèche le matin. Elles peuvent se produire dans les pentes ensoleillées l'après-midi, en neige en voie d'humidification.

Qualité de la neige

Qualification de l'enneigement : Enneigement excellent pour la saison à toutes altitudes, avec des cumuls de neige récente atteignant ponctuellement les 40/60 cm en moyenne montagne. On relève 2m73 sur la Maniccia à 2350 m.

Limite d'enneigement skiable : Vers 1400/1500 m.

État de la neige : La neige récente est encore sèche et plutôt légère, localement humidifiée ou croûtée en dessous de 1800 m. Le vent soutenu qui a accompagné les différentes chutes rend l'enneigement toujours très hétérogène. La neige est froide et poudreuse à l'abri du vent, elle devient plus compacte, voire cartonnée dans les secteurs ventés. Des anciennes surfaces, souvent dures et glacées, réapparaissent près des crêtes.

Aperçu météo pour le jeudi 05 février

	nuit	matin	après-midi	soir

Après les chutes de la fin de nuit, amélioration en cours de matinée avant une nouvelle dégradation pluvieuse en soirée.

Pluie-Neige	1 300 m		1 800 m	2 000 m
Iso 0 °C	1 700 m	2 200 m	2 200 m	2 400 m
Vent 1500 m	→ 25 km/h	↗ 35 km/h	↗ 30 km/h	↗ 50 km/h
Vent 3000 m	→ 35 km/h	↗ 50 km/h	↗ 45 km/h	↗ 65 km/h

Épaisseur de neige hors-piste

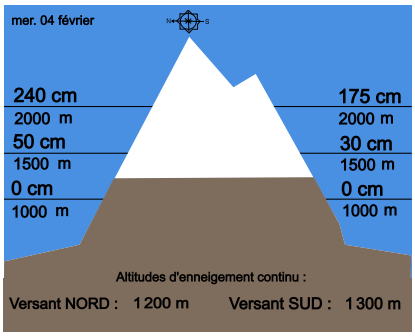

Précipitations à 1800 m

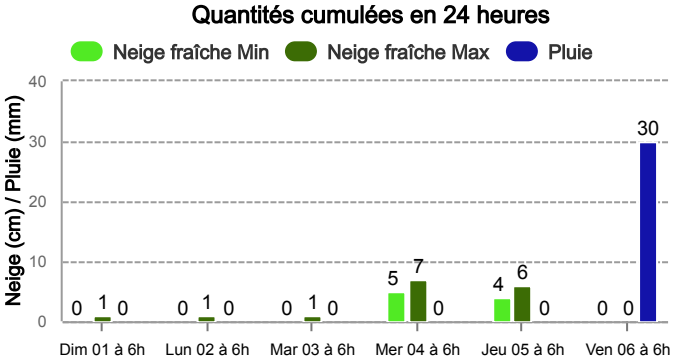

Tendance du vendredi 06 février

3 **Indice de risque marqué**

Fortes précipitations attendues sur l'Ouest des reliefs, sous forme de pluie jusqu'à haute altitude. Forts cumuls de neige au-dessus de 2100m, risque de fonte en dessous de 1800m. Le risque reste marqué.

Pour consulter la vigilance en cours, veuillez vous rendre sur le site https://vigilance.meteofrance.fr/fr

Météo-France - 73 avenue de Paris, 94165 Saint-Mandé cedex - Contact : contact@meteo.fr

Rédigé par Météo-France avec la contribution des observateurs du réseau nivo-météorologiques. Partenariat : ANMSM (Maires de Stations de Montagne), DSF (Domaines Skiables de France), ADSP (Directeurs de Pistes et de la Sécurité des Stations de Sports d'Hiver) et autres acteurs de la montagne.

Bulletin neige & avalanches par téléphone au **0 892 68 10 20** Service 0,35 € / min + prix appel

RÉPUBLIQUE FRANÇAISE
Liberté Égalité Fraternité

METEO FRANCE
À VOS CÔTÉS, DANS UN CLIMAT QUI CHANGE

Bulletin d'estimation du risque d'avalanche

(valable en dehors des pistes balisées et ouvertes)

MASSIF : Cinto Rotondo

Rédigé le mercredi 4 février 2026 à 15h

Conditions nivo-météo des 7 derniers jours

	jeu. 29/01				ven. 30/01				sam. 31/01				dim. 01/02				lun. 02/02				mar. 03/02				mer. 04/02			
	03h	09h	15h	21h	03h	09h	15h	21h	03h	09h	15h	21h	03h	09h	15h	21h	03h	09h	15h	21h	03h	09h	15h	21h	03h	09h	15h	21h
Météo																												
Vent (km/h)	90	80	80	60	50	55	65	60	50	25	30	20	25	20	30	40	50	40	40	50	60	60	35	20	25	60	50	25
à 3000m																												
Vent (km/h)	60	60	60	40	35	40	50	50	30	30	25	15	25	15	15	15	30	20	20	25	40	50	30	15	20	30	25	15
à 1500m																												

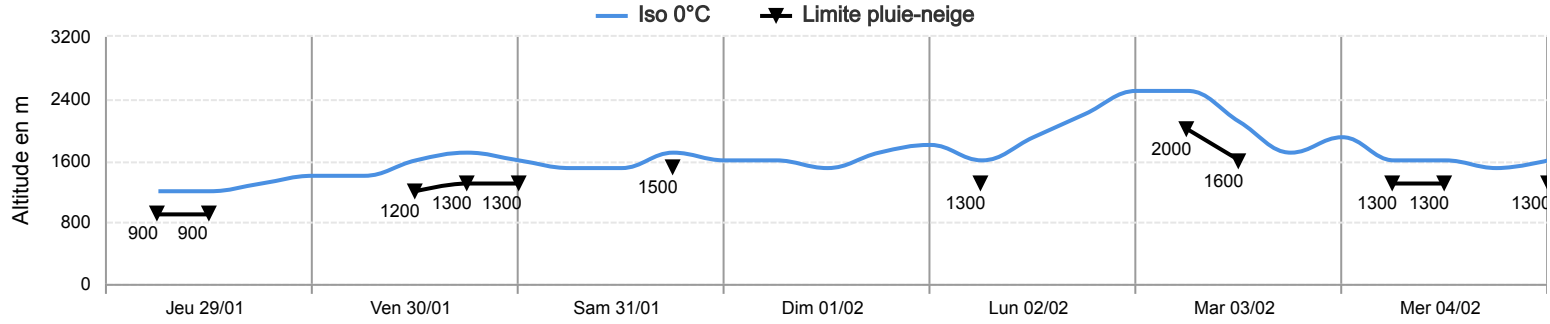

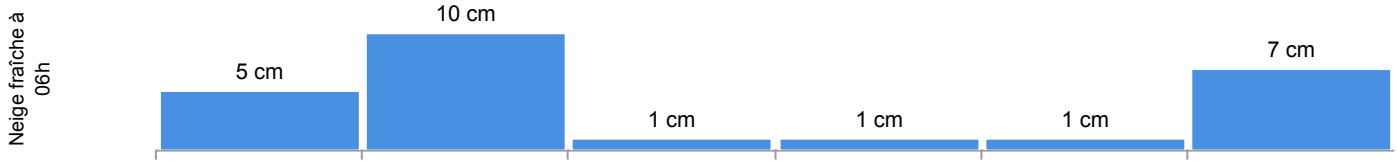

Risque d'avalanche	jeu. 29/01	ven. 30/01	sam. 31/01	dim. 01/02	lun. 02/02	mar. 03/02	mer. 04/02
	4	4	3	3	3	3	3

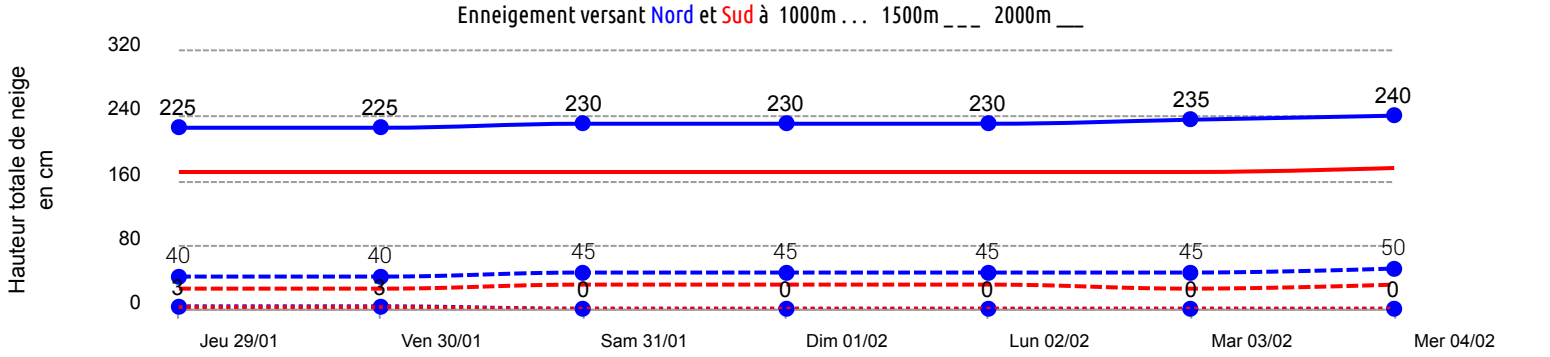

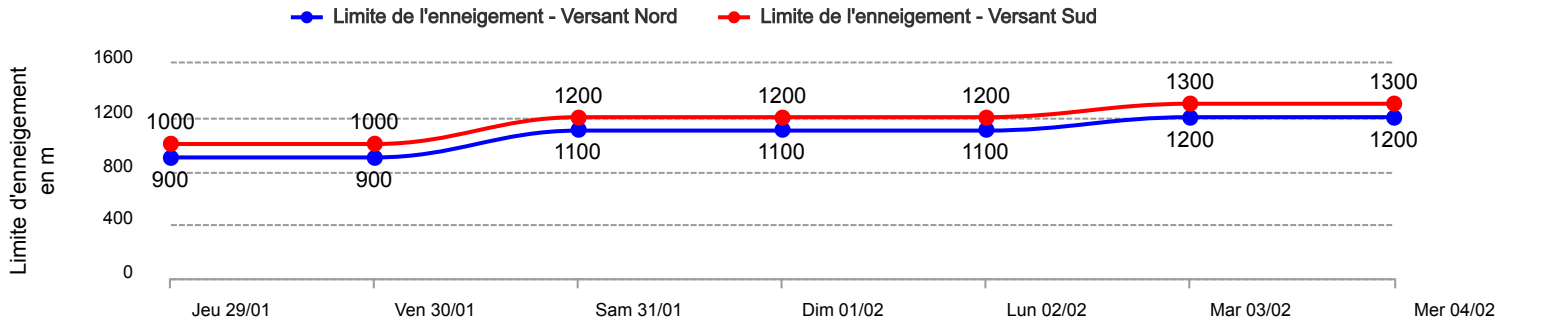

Pour consulter la vigilance en cours, veuillez vous rendre sur le site https://vigilance.meteofrance.fr/fr

Météo-France - 73 avenue de Paris, 94165 Saint-Mandé cedex - Contact : contact@meteo.fr

Rédigé par Météo-France avec la contribution des observateurs du réseau nivo-météorologiques. Partenariat : ANMSM (Maires de Stations de Montagne), DSF (Domaines Skiables de France), ADSP (Directeurs de Pistes et de la Sécurité des Stations de Sports d'Hiver) et autres acteurs de la montagne.

Bulletin neige & avalanches par téléphone au

0 892 68 10 20 Service 0,35 € / min + prix appel