RÉPUBLIQUE FRANÇAISE
Liberté Égalité Fraternité

METEO FRANCE
À VOS CÔTÉS, DANS UN CLIMAT QUI CHANGE

Bulletin d'estimation du risque d'avalanche
(valable en dehors des pistes balisées et ouvertes)

MASSIF : Aure Louron

Rédigé le mercredi 4 février 2026 à 16h

Estimation des risques pour le : JEUDI 05 FÉVRIER

NEIGE VENTEE EN ALTITUDE, HUMIDIFICATION LENTE PLUS BAS.

3

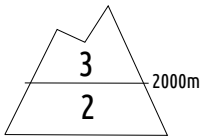

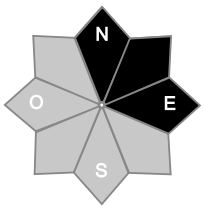

Au-dessus de 2000m indice de risque marqué, plus bas indice limité.

Départs spontanés : ponctuels en neige humide, cassures linéaires en neige ventée.

Déclenchements provoqués : plaques instables au-dessus de 2000m en nord à est.

Indices de risque : 5 très fort - 4 fort - 3 marqué - 2 limité - 1 faible -- En noir : les pentes les plus dangereuses

Stabilité du manteau neigeux

Situation avalancheuse typique : neige ventée neige humide

Déclenchements provoqués : probables par faible sollicitation des plaques au-dessus de 2000m formées et toujours en cours de formation dans les pentes nord à est.
Sur l'ensemble du massif, avec le vent fort, ces plaques se sont **formées loin des crêtes, cols et sommets** dans les secteurs déventés, la neige récente et sèche a été très éparpillée, ne permettant que de **faibles accumulations**. Un **seul skieur ou randonneur** peut donc **facilement y déclencher une avalanche de plaque de taille 1 à 2**. **Cependant en secteur frontalier**, chutes de neige et transport par le vent plus importants ont formé des **accumulations un peu plus épaisses. Avalanche de taille 3 possible :** surcharge du skieur et d'une avalanche de taille 2 peuvent, par sollicitation des plaques plus anciennes et plus épaisses présentes en contrebas, donner lieu à ces avalanches plus volumineuses.
Dans tous les **autres secteurs**, **neige très travaillée par le vent, dure et en cours d'humidification**, constituant un **manteau neigeux stable** et peu sensible au sollicitation.

Départs spontanés : départs **peu fréquents et en pentes raides**, se répartissant comme suit :
- **en neige sèche dans les versants nord à est** : départs **ponctuels en coulée ou petite avalanche partant d'une petite accumulation de neige sèche au-dessus de 1900 à 2100m**, quelques **cassures linéaires par déclenchement des plaques** décrites ci-dessus par **surcharge avec l'apport supplémentaire de neige transportée par le vent**, souvent de **petite taille**, **plus rarement de taille moyenne en partant d'une accumulation un peu plus importante** (constituée par exemple dans une combe ou un couloir raides nord à nord-est déventés en secteur frontalier).
- **en neige humide** : sous 1900/2000m d'altitude et dans tous les autres versants, l'humidification est à l'origine de départs ponctuels de neige alourdie.

Autres : à l'exception des pentes nord à est au-dessus de 2000/2100m, manteau neigeux dur et glissant en début de matinée (durci par le vent et tassé par l'humidification sous 1800/1900m, regelé au-dessus).

Observables : travail du vent visible en versants sud et ouest, pas facilement identifiable en nord à est si ce n'est les effets de sillage (petite accumulation rectiligne sous le vent d'un obstacle).

Qualité de la neige

Enneigement : assez correct pour la saison, mais les crêtes, cols et sommets sont souvent pelés par le vent dans les expositions ouest. Le manteau neigeux s'est bien humidifié sous 2000m, mais ne fond que très lentement.
Limites skiables : manteau neigeux skiable à partir de 1400/1500m avec sous couche portante.
État de la neige : neige durcie et portante, regelée au-dessus de 1800/1900m, tassée par le vent et l'humidification en dessous, très frittée près des cols, crêtes et sommets. Quelques centimètres de neige fraîche et encore sèche mais travaillée par le vent déposés au-dessus de 1800m dans les pentes nord à est. Peu d'évolution en journée du manteau neigeux en place dans ces mêmes pentes. Partout ailleurs, la neige ramollit et s'humidifie lentement sous 2000/2100m, n'évolue pas au-dessus de 2200m.

Aperçu météo pour le jeudi 05 février

	nuit	matin	après-midi	soir
Quelques averses, redoux léger, vent fort de sud-ouest à ouest.				
Pluie-Neige		1 900 m	1 800 m	1 700 m
Iso 0 °C	2 200 m	2 300 m	2 100 m	2 000 m
Vent 1500 m	↑ 30 km/h	↑ 60 km/h	↗ 40 km/h	↗ 30 km/h
Vent 3000 m	↗ 75 km/h	↗ 100 km/h	→ 85 km/h	→ 70 km/h

Pour consulter la vigilance en cours, veuillez vous rendre sur le site https://vigilance.meteofrance.fr/fr

Météo-France - 73 avenue de Paris, 94165 Saint-Mandé cedex - Contact : contact@meteo.fr

Rédigé par Météo-France avec la contribution des observateurs du réseau nivo-météorologiques. Partenariat : ANMSM (Maires de Stations de Montagne), DSF (Domaines Skiables de France), ADSP (Directeurs de Pistes et de la Sécurité des Stations de Sports d'Hiver) et autres acteurs de la montagne.

Bulletin neige & avalanches par téléphone au
0 892 68 10 20 Service 0,35 € / min + prix appel

Bulletin d'estimation du risque d'avalanche

(valable en dehors des pistes balisées et ouvertes)

MASSIF : Aure Louron

Rédigé le mercredi 4 février 2026 à 16h

Épaisseur de neige hors-piste

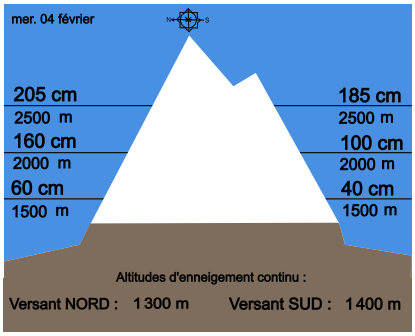

Précipitations à 1800 m

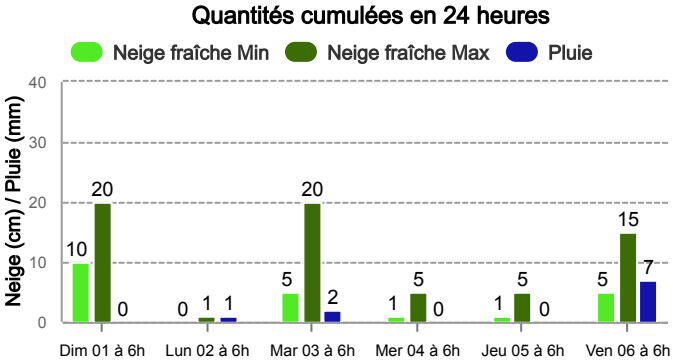

Tendance du vendredi 06 février

Indice de risque marqué

Maintien du risque marqué dans les pentes nord en altitude.

Pour consulter la vigilance en cours, veuillez vous rendre sur le site https://vigilance.meteofrance.fr/fr

Météo-France - 73 avenue de Paris, 94165 Saint-Mandé cedex - Contact : contact@meteo.fr

Rédigé par Météo-France avec la contribution des observateurs du réseau nivo-météorologiques. Partenariat : ANMSM (Maires de Stations de Montagne), DSF (Domaines Skiables de France), ADSP (Directeurs de Pistes et de la Sécurité des Stations de Sports d'Hiver) et autres acteurs de la montagne.

Bulletin neige & avalanches par téléphone au

0 892 68 10 20 Service 0,35 € / min + prix appel

RÉPUBLIQUE FRANÇAISE
Liberté Égalité Fraternité

METEO FRANCE
À VOS CÔTÉS, DANS UN CLIMAT QUI CHANGE

Bulletin d'estimation du risque d'avalanche

(valable en dehors des pistes balisées et ouvertes)

MASSIF : Aure Louron

Rédigé le mercredi 4 février 2026 à 16h

Conditions nivo-météo des 7 derniers jours

	jeu. 29/01				ven. 30/01				sam. 31/01				dim. 01/02				lun. 02/02				mar. 03/02				mer. 04/02			
	03h	09h	15h	21h	03h	09h	15h	21h	03h	09h	15h	21h	03h	09h	15h	21h	03h	09h	15h	21h	03h	09h	15h	21h	03h	09h	15h	21h
Météo																												
Vent (km/h)	70	100	70	90	100	90	60	90	100	100	100	70	40	40	45	50	70	125	120	80	65	45	45	90	95	100	60	55
à 3000m																												
Vent (km/h)	20	40	30	50	65	50	30	45	60	70	70	35	25	20	20	35	50	85	85	45	25	30	30	50	60	40	20	25
à 1500m																												

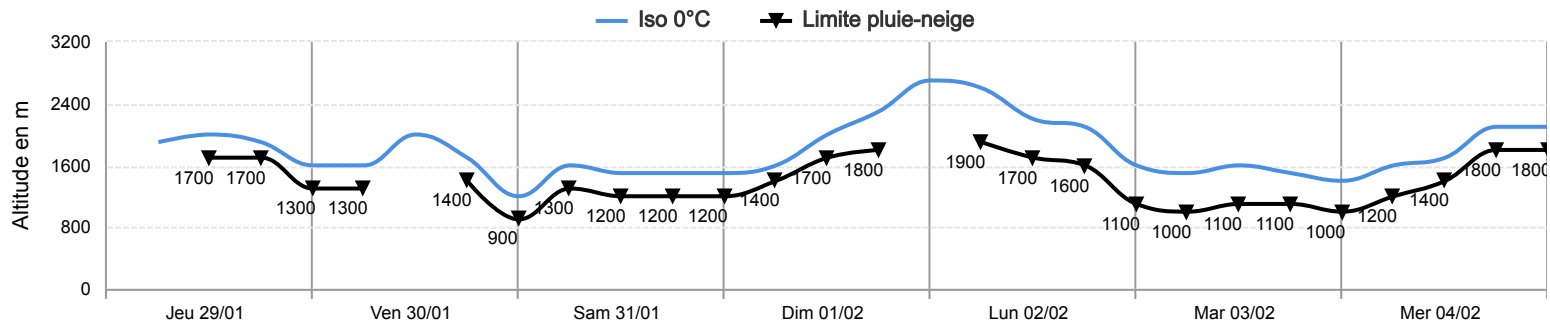

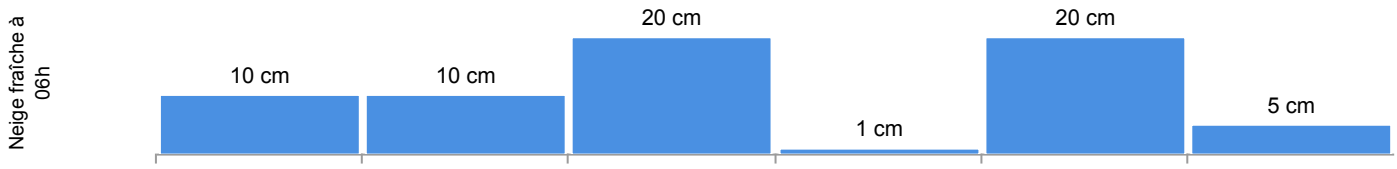

Risque d'avalanche	jeu. 29/01	ven. 30/01	sam. 31/01	dim. 01/02	lun. 02/02	mar. 03/02	mer. 04/02
	3	3	4	4	3	3	3

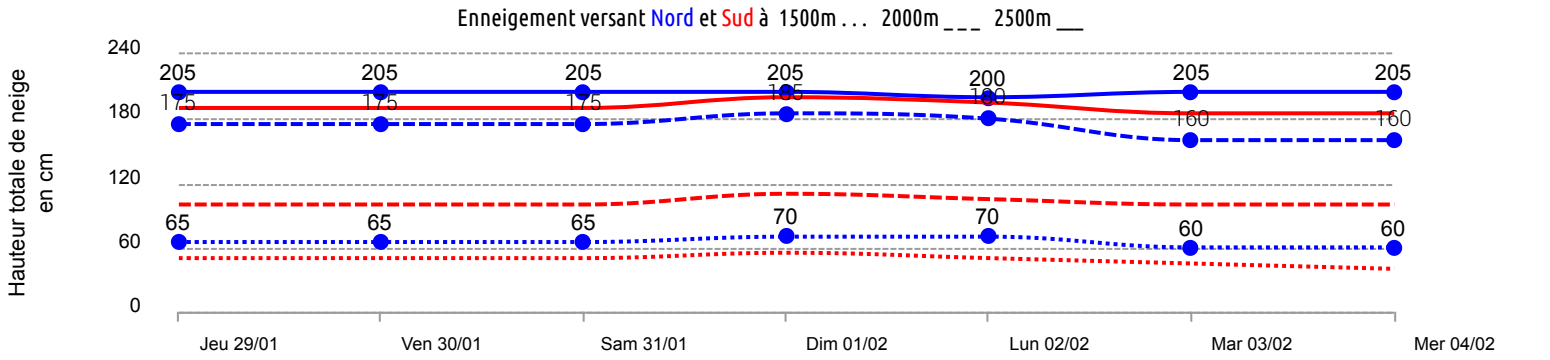

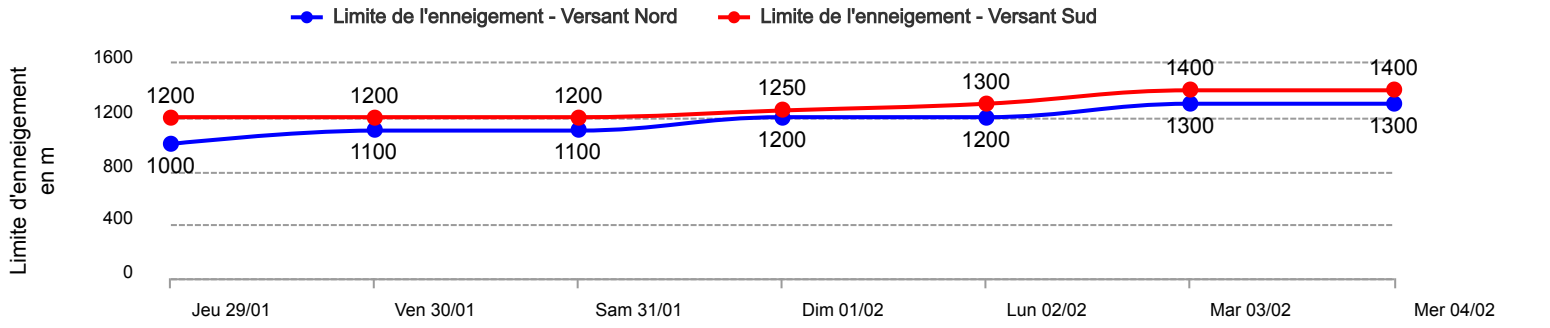

Pour consulter la vigilance en cours, veuillez vous rendre sur le site https://vigilance.meteofrance.fr/fr

Météo-France - 73 avenue de Paris, 94165 Saint-Mandé cedex - Contact : contact@meteo.fr

Rédigé par Météo-France avec la contribution des observateurs du réseau nivo-météorologiques. Partenariat : ANMSM (Maires de Stations de Montagne), DSF (Domaines Skiables de France), ADSP (Directeurs de Pistes et de la Sécurité des Stations de Sports d'Hiver) et autres acteurs de la montagne.

Bulletin neige & avalanches par téléphone au
0 892 68 10 20 Service 0,35 € / min + prix appel