Bulletin d'estimation du risque d'avalanche

(valable en dehors des pistes balisées et ouvertes)

MASSIF : Bauges

Rédigé le mercredi 4 février 2026 à 16h

Estimation des risques pour le : JEUDI 05 FÉVRIER

NOMBREUSES INSTABILITÉS LIÉES AU FORT VENT DE S/SW.

3

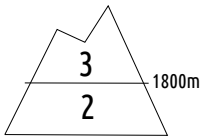

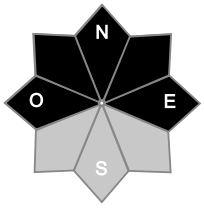

Au-dessus de 1800m indice de risque marqué, plus bas indice limité.

Départs spontanés : Petites coulées au soleil .

Déclenchements provoqués : Nombreuses plaques sous le vent de S/SW.

Indices de risque : 5 très fort - 4 fort - 3 marqué - 2 limité - 1 faible -- En noir : les pentes les plus dangereuses

Stabilité du manteau neigeux

Situation avalancheuse typique : neige ventée

Déclenchements provoqués :

* **Nombreuses plaques à vent**. Principalement au-delà de 1800m, dans les **accumulations en ubacs**. Formées par le vent de S/SW qui souffle ces derniers jours. Elles peuvent être présentes **même loin des crêtes**. Taille 1 à 2 (petite à moyenne), rarement 3 (grande).

Observables : vaguelettes sur la neige de surface, fissures sous les skis, accumulations de neige récente, transport en cours, etc...

Départs spontanés : Probabilité de départs en baisse.

* Petits départs ponctuels (escargots, boulettes), surtout dans les pentes raides, près des rochers et des falaises. Taille 1.
* Sur les terrains lisses sous 2000/2200m, possibles départs de plaques de fond à toute heure du jour et de la nuit. Taille 1 (petite).

Qualité de la neige

Enneigement : Pour la saison, l'enneigement est déficitaire en dessous de 1800 m et correct au-dessus.
On peut chausser les skis vers 900/1000 m. Pas de sous-couche sous 1500 m ou sur les crêtes, des cailloux sont cachés sous la neige récente.

Qualité de la neige jeudi :

- En dessous de 1500 m, la neige est croutée le matin puis rapidement humide.
- Entre 1500 et 1800 m, la neige est alourdie en ubacs, et dans les adrets, elle subit une évolution de printemps.
- Au-dessus de 1800 m, 20/30 cm de neige froide cartonnée par le vent. Les crêtes sont décapées. Dans les endroits les plus à l'abri du vent de sud, la neige est encore poudreuse dense.

Aperçu météo pour le jeudi 05 février

	nuit	matin	après-midi	soir

Couvert au reveil, puis belles éclaircies en milieu de journée avant le retour des nuages l'après-midi et des précipitations en soirée.

Pluie-Neige				1 400 m
Iso 0 °C	1 700 m	1 900 m	2 000 m	1 900 m
Vent 1500 m	↑ 20 km/h	↑ 20 km/h	↑ 20 km/h	↑ 20 km/h
Vent 2000 m	↑ 30 km/h	↑ 30 km/h	↑ 30 km/h	↖ 25 km/h

Épaisseur de neige hors-piste

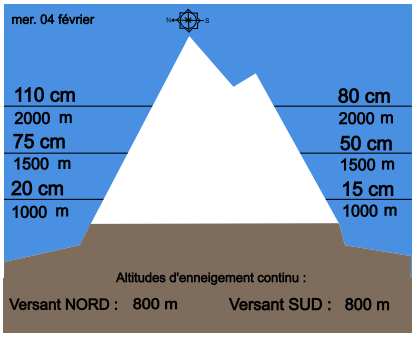

Précipitations à 1800 m

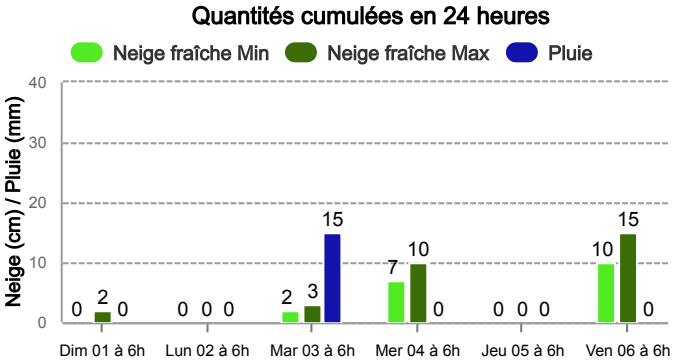

Tendance du vendredi 06 février

3

Indice de risque marqué

Risque en hausse dans la neige fraiche.

Pour consulter la vigilance en cours, veuillez vous rendre sur le site https://vigilance.meteofrance.fr/fr

Météo-France - 73 avenue de Paris, 94165 Saint-Mandé cedex - Contact : contact@meteo.fr

Rédigé par Météo-France avec la contribution des observateurs du réseau nivo-météorologiques. Partenariat : ANMSM (Maires de Stations de Montagne), DSF (Domaines Skiables de France), ADSP (Directeurs de Pistes et de la Sécurité des Stations de Sports d'Hiver) et autres acteurs de la montagne.

Bulletin neige & avalanches par téléphone au

0 892 68 10 20 Service 0,35 € / min + prix appel

RÉPUBLIQUE FRANÇAISE
Liberté Égalité Fraternité

METEO FRANCE
À VOS CÔTÉS, DANS UN CLIMAT QUI CHANGE

Bulletin d'estimation du risque d'avalanche

(valable en dehors des pistes balisées et ouvertes)

MASSIF : Bauges

Rédigé le mercredi 4 février 2026 à 16h

Conditions nivo-météo des 7 derniers jours

	jeu. 29/01				ven. 30/01				sam. 31/01				dim. 01/02				lun. 02/02				mar. 03/02				mer. 04/02			
	03h	09h	15h	21h	03h	09h	15h	21h	03h	09h	15h	21h	03h	09h	15h	21h	03h	09h	15h	21h	03h	09h	15h	21h	03h	09h	15h	21h
Météo																												
Vent (km/h)	20	10	10	15	25	25	20	25	20	10	10	10	15	10	20	30	30	40	50	55	55	45	35	30	20	20	25	35
à 2000m																												
Vent (km/h)	15	5	5	10	20	20	15	20	15	5	5	5	10	5	10	15	20	25	30	30	40	35	25	20	10	10	15	25
à 1500m																												

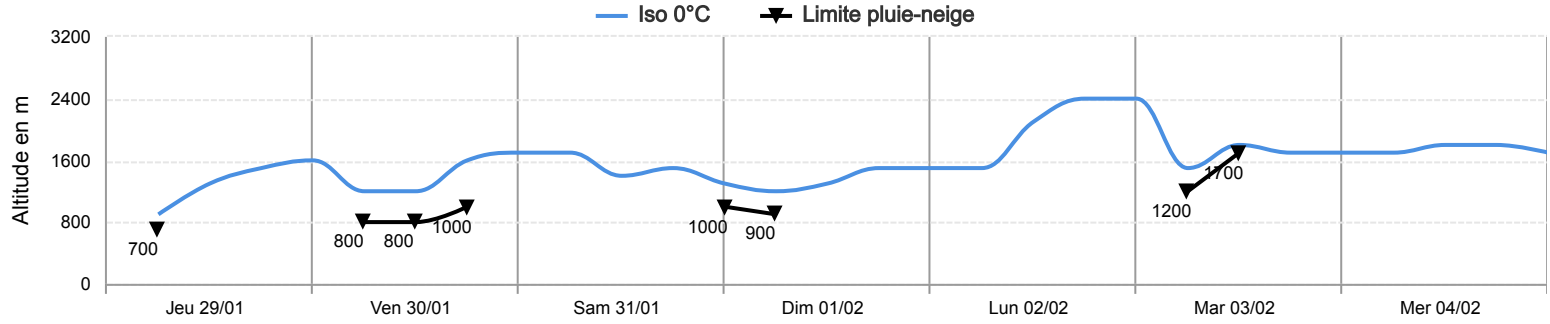

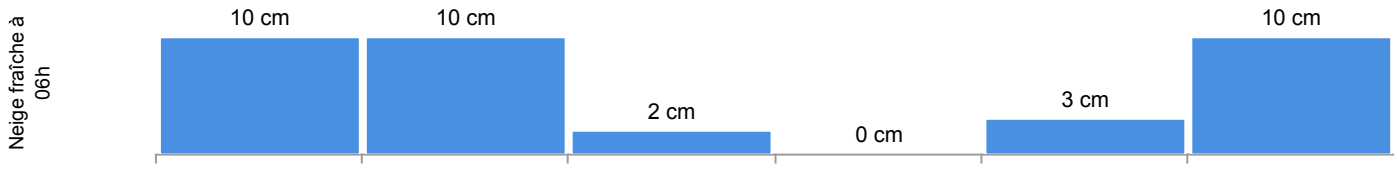

Risque d'avalanche	jeu. 29/01	ven. 30/01	sam. 31/01	dim. 01/02	lun. 02/02	mar. 03/02	mer. 04/02
	2	2	2	2	2	3	3

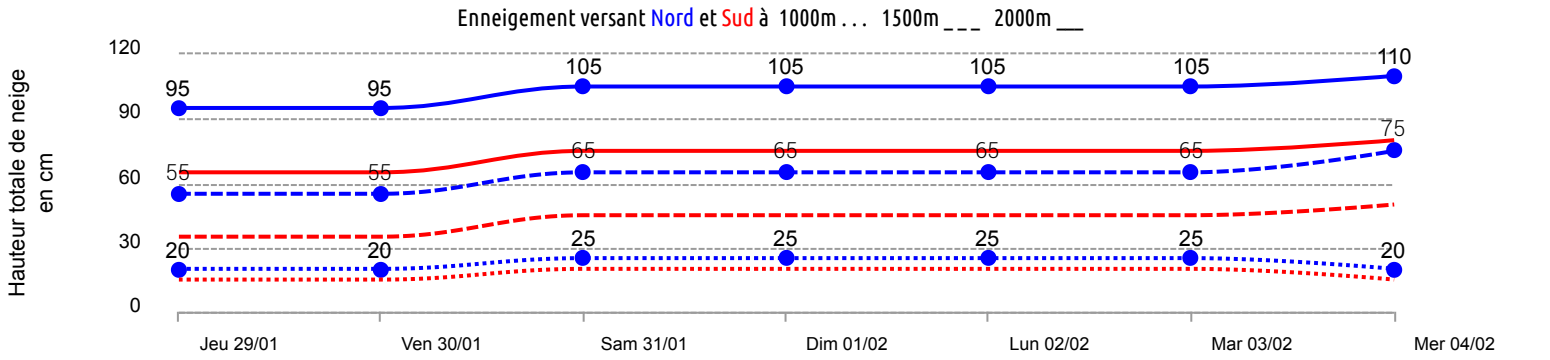

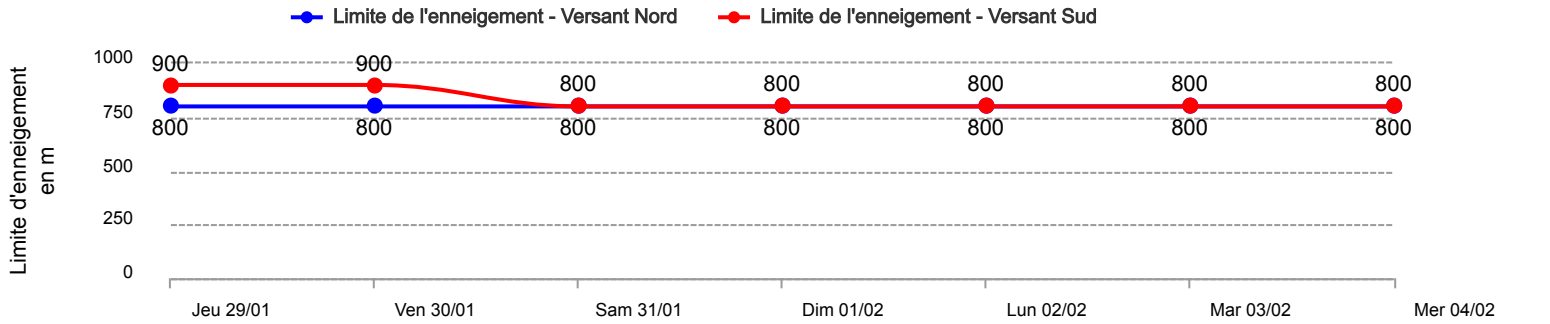

Pour consulter la vigilance en cours, veuillez vous rendre sur le site https://vigilance.meteofrance.fr/fr

Météo-France - 73 avenue de Paris, 94165 Saint-Mandé cedex - Contact : contact@meteo.fr

Rédigé par Météo-France avec la contribution des observateurs du réseau nivo-météorologiques. Partenariat : ANMSM (Maires de Stations de Montagne), DSF (Domaines Skiables de France), ADSP (Directeurs de Pistes et de la Sécurité des Stations de Sports d'Hiver) et autres acteurs de la montagne.

Bulletin neige & avalanches par téléphone au
0 892 68 10 20 Service 0,35 € / min + prix appel