Bulletin d'estimation du risque d'avalanche

(valable en dehors des pistes balisées et ouvertes)

MASSIF : Beaufortain

Rédigé le mercredi 4 février 2026 à 16h

Estimation des risques pour le : JEUDI 05 FÉVRIER

QUELQUES PLAQUES « À VENT », COUCHE FRAGILE ENFOUIE DANS LES VERSANTS FROIDS.

2

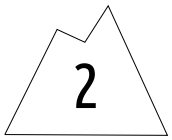

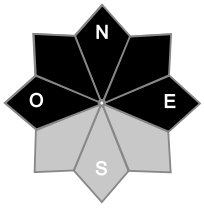

Indice de risque limité.

Départs spontanés : Peu probable

Déclenchements provoqués : quelques plaques dans la neige ventée. Couche fragile persistante en versants froids.

Indices de risque : 5 très fort - 4 fort - 3 marqué - 2 limité - 1 faible -- En noir : les pentes les plus dangereuses

Stabilité du manteau neigeux

Situation avalancheuse typique : neige ventée couche fragile persistante

Déclenchements provoqués :

(1) **Quelques plaques généralement friables** suite au coup de vent de sud (foehn) de la nuit de lundi à mardi. Encore généralement **réactives**, on les trouve en tous versants aussi bien **près des crêtes qu'en pied de pentes**. Tailles 2 (moyennes) avec des cassures très variables, pour une moyenne **de 20-30 cm** d'épaisseur. *Observables : indices de transport, accumulation ferme sous les skis.*

(2) La **couche fragile persistante (grains anguleux), enfouie** depuis plusieurs semaine, **est toujours présente dans les pentes Nord/Est/Ouest dès 2000 m.** Elle vient former une épaisse structure de plaque qui, en cas de déclenchement, entraîne l'ensemble du manteau neigeux., provoquant des avalanches de taille 2 à 3 (grandes), avec des cassures dépassant 1m. Le déclenchement de telles plaques semblent toutefois maintenant difficile et très localisé *Observables : woumfs, tests CT/ECT franchement positifs*

Départs spontanés : Peu probable

Qualité de la neige

Enneigement : l'enneigement est désormais tout juste normal. Les petites chutes de neige tout au long de la semaine ont maintenu l'enneigement dans la norme.

Limite skiable : encore à basse altitude sur l'herbe en ubac, parfois dès 900 à 1000 m. Même si la plupart des pentes sont enneigées bas, sur terrain rocheux, il vaut mieux atteindre 1300 m en N, 1800 m en Sud pour trouver un terrain plus serein.

Qualité de la neige : manteau neigeux partiellement travaillé par le vent. On trouve encore de la neige poudreuse légère dans les quelques secteurs à l'abri, tandis que la neige est souvent densifiée par le vent ailleurs. Neige transformée/humide en tous versants sous 1500 m, et croutée jusque vers 2000/2200 m en sud raide

Aperçu météo pour le jeudi 05 février

	nuit	matin	après-midi	soir
Journée calme, sans vent fort, quelques nuages. Petite chue de neige la nuit de jeudi à vendredi.				
Pluie-Neige				1 300 m
Iso 0 °C	1 700 m	2 000 m	2 300 m	2 100 m
Vent 2000 m	← 10 km/h	↖ 15 km/h	↖ 15 km/h	↖ 25 km/h
Vent 3000 m	→ 35 km/h	↗ 25 km/h	↗ 35 km/h	↑ 30 km/h

Épaisseur de neige hors-piste

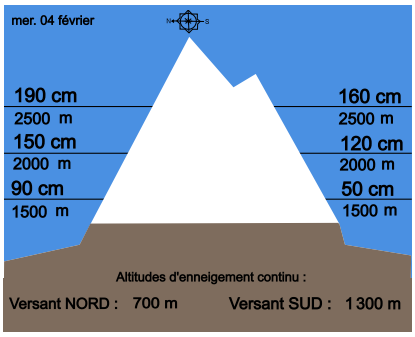

Précipitations à 1800 m

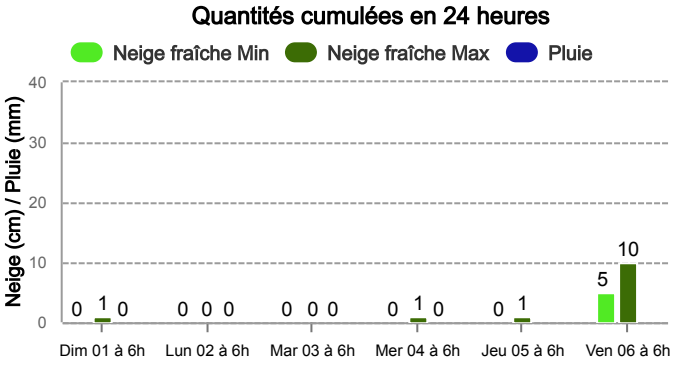

Tendance du vendredi 06 février

3

Indice de risque marqué

Nouvelles petites instabilités dans la neige fraiche attendue dans la nuit de jeudi à vendredi . Risque en légère hausse

Pour consulter la vigilance en cours, veuillez vous rendre sur le site https://vigilance.meteofrance.fr/fr

Météo-France - 73 avenue de Paris, 94165 Saint-Mandé cedex - Contact : contact@meteo.fr

Rédigé par Météo-France avec la contribution des observateurs du réseau nivo-météorologiques. Partenariat : ANMSM (Maires de Stations de Montagne), DSF (Domaines Skiables de France), ADSP (Directeurs de Pistes et de la Sécurité des Stations de Sports d'Hiver) et autres acteurs de la montagne.

Bulletin neige & avalanches par téléphone au

0 892 68 10 20 Service 0,35 € / min + prix appel

RÉPUBLIQUE FRANÇAISE
Liberté Égalité Fraternité

METEO FRANCE
À VOS CÔTÉS, DANS UN CLIMAT QUI CHANGE

Bulletin d'estimation du risque d'avalanche

(valable en dehors des pistes balisées et ouvertes)

MASSIF : Beaufortain

Rédigé le mercredi 4 février 2026 à 16h

Conditions nivo-météo des 7 derniers jours

	jeu. 29/01				ven. 30/01				sam. 31/01				dim. 01/02				lun. 02/02				mar. 03/02				mer. 04/02			
	03h	09h	15h	21h	03h	09h	15h	21h	03h	09h	15h	21h	03h	09h	15h	21h	03h	09h	15h	21h	03h	09h	15h	21h	03h	09h	15h	21h
Météo																												
Vent (km/h)	30	20	15	20	40	35	25	25	25	20	15	15	10	10	15	20	35	35	50	65	70	65	50	45	60	30	20	20
à 3000m																												
Vent (km/h)	15	10	10	10	10	15	15	10	15	10	10	10	5	5	10	10	20	20	40	55	60	50	30	20	50	20	10	10
à 2000m																												

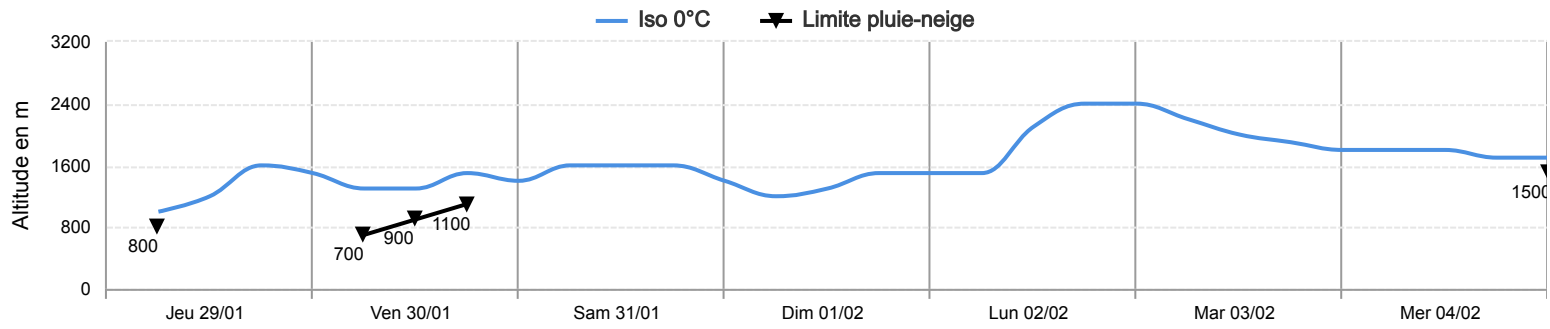

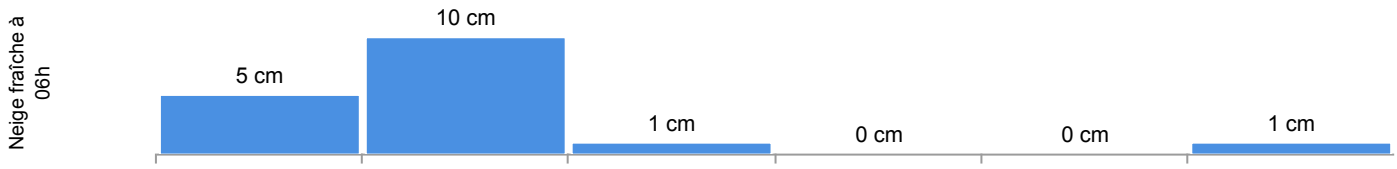

Risque d'avalanche	jeu. 29/01	ven. 30/01	sam. 31/01	dim. 01/02	lun. 02/02	mar. 03/02	mer. 04/02
	3	3	3	3	3	3	3

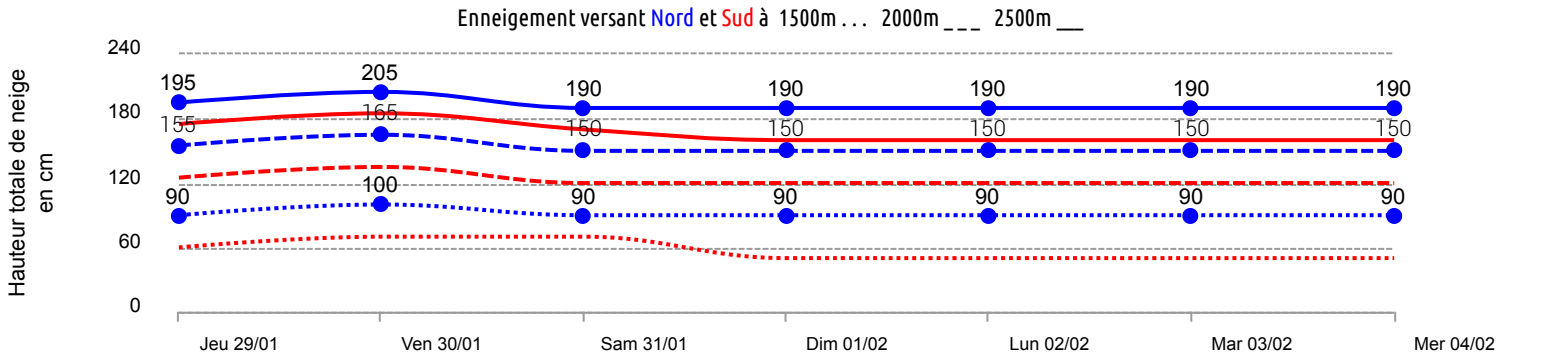

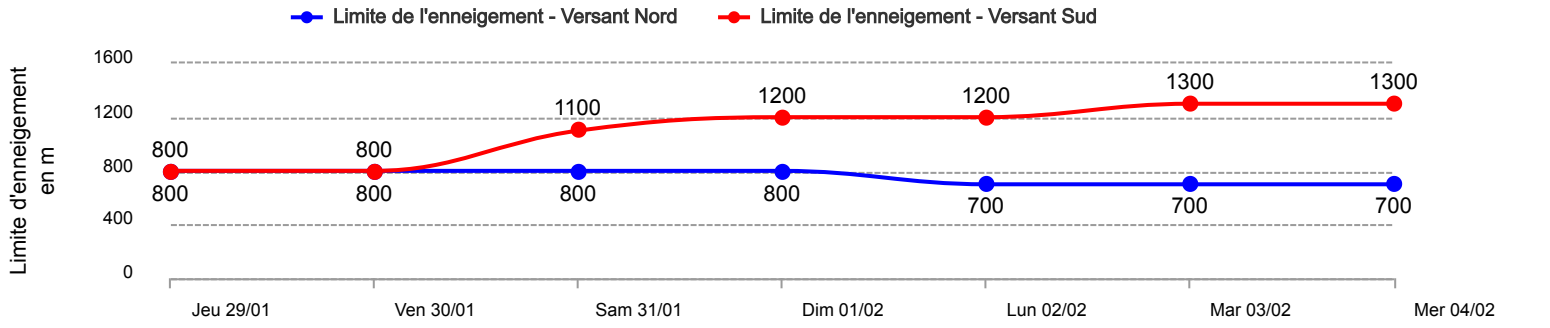

Pour consulter la vigilance en cours, veuillez vous rendre sur le site https://vigilance.meteofrance.fr/fr

Météo-France - 73 avenue de Paris, 94165 Saint-Mandé cedex - Contact : contact@meteo.fr

Rédigé par Météo-France avec la contribution des observateurs du réseau nivo-météorologiques. Partenariat : ANMSM (Maires de Stations de Montagne), DSF (Domaines Skiables de France), ADSP (Directeurs de Pistes et de la Sécurité des Stations de Sports d'Hiver) et autres acteurs de la montagne.

Bulletin neige & avalanches par téléphone au

0 892 68 10 20 Service 0,35 € / min + prix appel