Bulletin d'estimation du risque d'avalanche

(valable en dehors des pistes balisées et ouvertes)

MASSIF : Devoluy

Rédigé le mercredi 4 février 2026 à 16h

Estimation des risques pour le : JEUDI 05 FÉVRIER

INSTABILITÉ ENCORE MARQUÉE DANS LA NEIGE VENTÉE

3

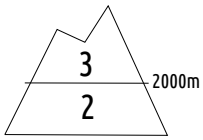

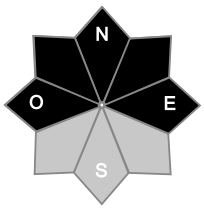

Au-dessus de 2000m indice de risque marqué, plus bas indice limité.

Départs spontanés : taille moyenne sous l'effet du vent et des chutes de neige en fin de journée

Déclenchements provoqués : instabilités dans la neige ventée, parfois volumineuses

Indices de risque : 5 très fort - 4 fort - 3 marqué - 2 limité - 1 faible -- En noir : les pentes les plus dangereuses

Stabilité du manteau neigeux

Situation avalancheuse typique : neige ventée couche fragile persistante

Déclenchements provoqués : le manteau neigeux reste peu stabilisé en altitude. Ces instabilités se situent principalement en orientations ouest, nord et est d'altitude supérieure à 2000 m. Un seul skieur peut les déclencher, parfois à distance, et générer des avalanches de taille moyenne. Les instabilités se situent principalement dans la neige ventée en surface. Elles sont plutôt identifiables, et localisées dans les secteurs d'accumulation par le vent, parfois loin des crêtes. Le déclenchement de ces plaques plutôt dures peut cependant solliciter en cascade des couches fragiles persistantes enfouies et générer des avalanches de grande taille, avec large et épaisse cassure, quand la topographie s'y prête.

Départs spontanés : avalanches de plaques possibles en fin de journée sous l'effet du fort vent de secteur sud en altitude. Taille petite à moyenne, grande possible en soirée avec l'accumulation de neige fraîche.
Par ailleurs, petits départs ponctuels en neige humide, taille petite à moyenne, en versants est à sud non encore purgés. Le retour provisoire du soleil jeudi matin s'effectue dans une masse d'air doux, qui favorise l'humidification du manteau neigeux, en versants raides ensoleillés.

Qualité de la neige

L'enneigement est plutôt excédentaire pour un début février.

Limite d'enneigement skiable : vers 1000/1200 m en ubacs. Sous-couche un peu limite en adrets sous 1400/1500 m.

État de la neige de surface : neige récente irrégulièrement répartie suite au vent fort, souvent densifiée ou durcie, mais encore poudreuse dans les pentes abritées. En versants sud, croûte superficielle jusque 1800/2000 m le matin, l'humidification se poursuit avec le soleil et la remontée de l'iso 0 avant la neige.
Crêtes bien chargées.

Aperçu météo pour le jeudi 05 février

	nuit	matin	après-midi	soir

Beau le matin, devenant voilé dense en début d'après-midi (jour blanc), neige à partir du milieu d'après-midi, forte le soir

Pluie-Neige	900 m		1 500 m	1 200 m
Iso 0 °C	1 400 m	1 900 m	2 100 m	1 600 m
Vent 2000 m	↘ 10 km/h	↑ 20 km/h	↑ 40 km/h	↑ 20 km/h
Vent 3000 m	↘ 30 km/h	→ 15 km/h	↑ 60 km/h	→ 30 km/h

Épaisseur de neige hors-piste

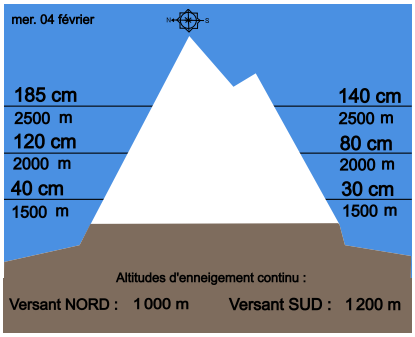

Précipitations à 1800 m

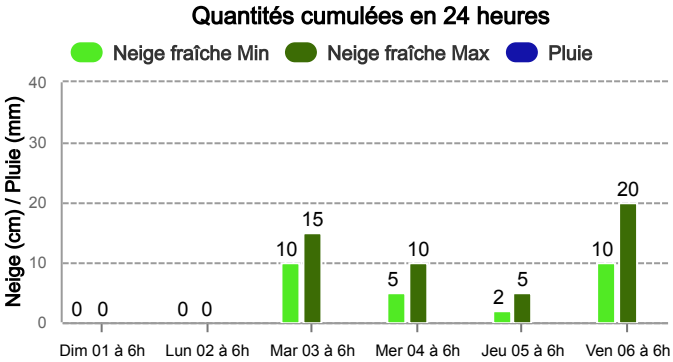

Tendance du vendredi 06 février

3 **Indice de risque marqué**

Nouvelles instabilité formées après la chute de neige de jeudi soir. Risque restant marqué

Pour consulter la vigilance en cours, veuillez vous rendre sur le site https://vigilance.meteofrance.fr/fr

Météo-France - 73 avenue de Paris, 94165 Saint-Mandé cedex - Contact : contact@meteo.fr

Rédigé par Météo-France avec la contribution des observateurs du réseau nivo-météorologiques. Partenariat : ANMSM (Maires de Stations de Montagne), DSF (Domaines Skiables de France), ADSP (Directeurs de Pistes et de la Sécurité des Stations de Sports d'Hiver) et autres acteurs de la montagne.

Bulletin neige & avalanches par téléphone au **0 892 68 10 20** Service 0,35 € / min + prix appel

RÉPUBLIQUE FRANÇAISE
Liberté Égalité Fraternité

METEO FRANCE
À VOS CÔTÉS, DANS UN CLIMAT QUI CHANGE

Bulletin d'estimation du risque d'avalanche

(valable en dehors des pistes balisées et ouvertes)

MASSIF : Devoluy

Rédigé le mercredi 4 février 2026 à 16h

Conditions nivo-météo des 7 derniers jours

	jeu. 29/01				ven. 30/01				sam. 31/01				dim. 01/02				lun. 02/02				mar. 03/02				mer. 04/02			
	03h	09h	15h	21h	03h	09h	15h	21h	03h	09h	15h	21h	03h	09h	15h	21h	03h	09h	15h	21h	03h	09h	15h	21h	03h	09h	15h	21h
Météo																												
Vent (km/h)	50	35	30	30	35	40	40	25	25	5	5	10	20	20	40	30	35	50	70	100	120	60	50	40	40	40	30	15
à 3000m																												
Vent (km/h)	50	30	20	15	15	30	25	15	15	15	15	10	20	20	15	10	10	25	45	80	70	45	35	35	35	30	20	5
à 2000m																												

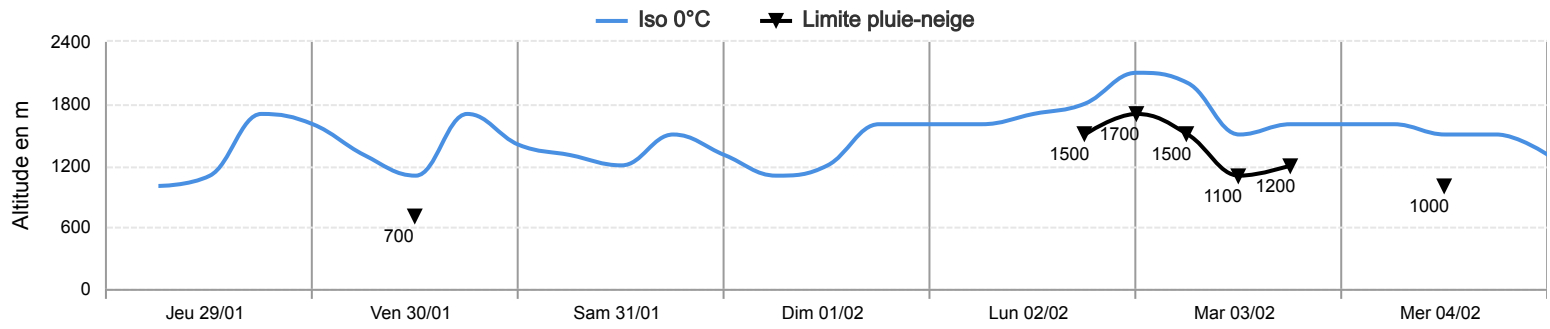

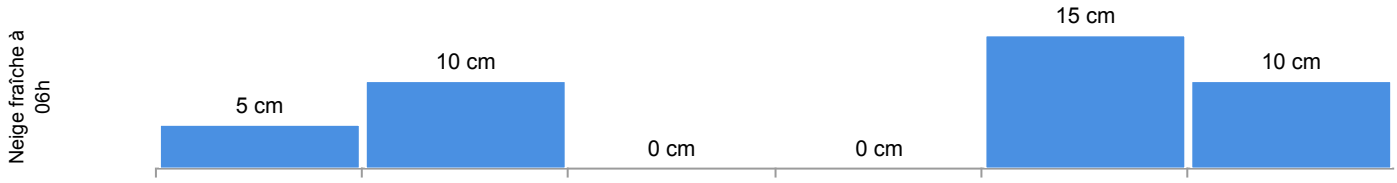

Risque d'avalanche	jeu. 29/01	ven. 30/01	sam. 31/01	dim. 01/02	lun. 02/02	mar. 03/02	mer. 04/02
	4	4	3	3	3	4	3

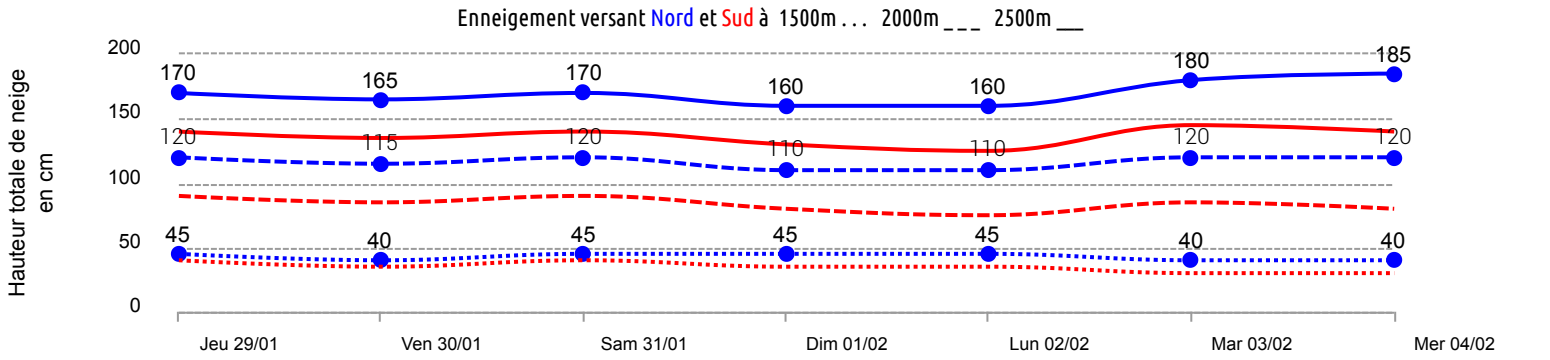

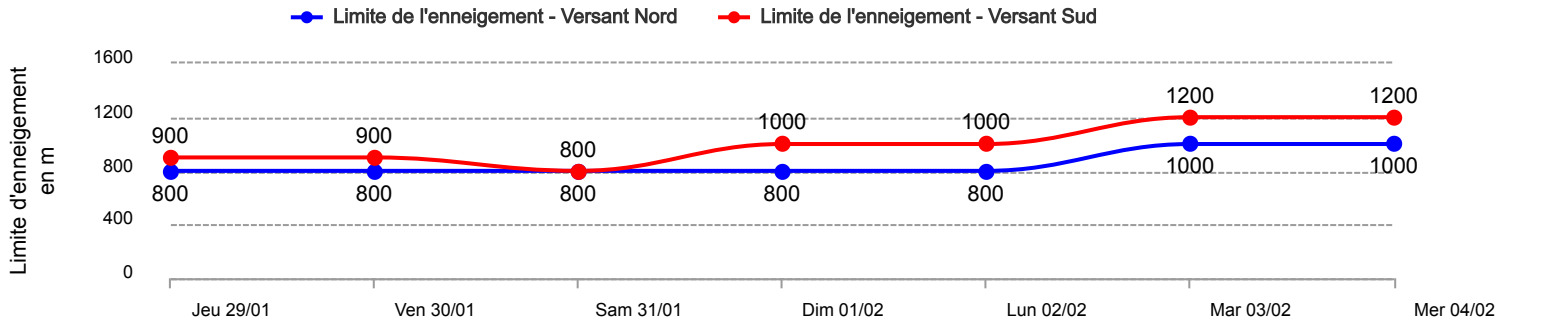

Pour consulter la vigilance en cours, veuillez vous rendre sur le site https://vigilance.meteofrance.fr/fr

Météo-France - 73 avenue de Paris, 94165 Saint-Mandé cedex - Contact : contact@meteo.fr

Rédigé par Météo-France avec la contribution des observateurs du réseau nivo-météorologiques. Partenariat : ANMSM (Maires de Stations de Montagne), DSF (Domaines Skiables de France), ADSP (Directeurs de Pistes et de la Sécurité des Stations de Sports d'Hiver) et autres acteurs de la montagne.

Bulletin neige & avalanches par téléphone au
0 892 68 10 20 Service 0,35 € / min + prix appel