Bulletin d'estimation du risque d'avalanche

(valable en dehors des pistes balisées et ouvertes)

MASSIF : Haut-Var Haut-Verdon

Rédigé le mercredi 4 février 2026 à 16h

Estimation des risques pour le : JEUDI 05 FÉVRIER

PLAQUES PARFOIS VOLUMINEUSES DANS LA NEIGE RÉCENTE

3

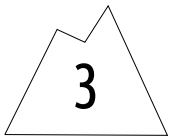

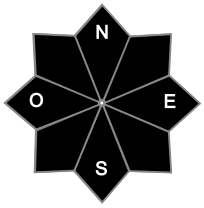

Indice de risque marqué.

Départs spontanés : quelques départs de neige récente s'humidifiant au soleil.

Déclenchements provoqués : plaques dans la neige récente, localement volumineuses.

Indices de risque : 5 très fort - 4 fort - 3 marqué - 2 limité - 1 faible -- En noir : les pentes les plus dangereuses

Stabilité du manteau neigeux

Situation avalancheuse typique : neige fraîche couche fragile persistante

Déclenchements provoqués :
Des plaques dans la neige récente sont en place, possibles en toutes orientations au dessus de 1800 m environ. Elles sont généralement d'aspect poudreux et difficiles à détecter, sinon durcies par le vent dans les secteurs exposés. Bien qu'étant en cours de stabilisation, leur déclenchement reste localement possible au passage d'un seul skieur, et elles peuvent provoquer des avalanches de taille souvent moyenne (taille 2).

En versants est, nord et ouest, la présence d'une couche fragile persistante au dessus de 1800/2000 m, peut occasionner des avalanches de plus grande taille (taille 3), emportant une grande partie du manteau neigeux, parfois sur de grandes distances. Toutefois, leur déclenchement est généralement devenu difficile à cause des importantes accumulations de neige des derniers épisodes, qui isolent cette couche en profondeur, mais peut être rendu possible sous une forte contrainte comme le déclenchement d'une première avalanche en surface.

En dessous de 1800 m environ, la neige récente s'est alourdie, et les instabilités sont moins nombreuses, de plus petite taille, et plus difficiles à déclencher.

Départs spontanés : quelques départs de neige récente s'humidifiant au soleil sont possibles. Départs ponctuels en pentes raides, de petite taille.

Qualité de la neige

Enneigement bon voire excédentaire jusqu'à basse altitude pour un début février. Données observées vers 2000 m en fond de vallon : 140 à 150 cm de hauteur totale de neige.

Enneigement skiable dès 1300/1400 m en terrain favorable, mais peu de sous-couche sous 1600 m en général.

État de la neige en surface : couche de neige récente atteignant 15/20 cm à partir de 1800 m, localement 30/35 cm. Cette neige est plus lourde sous 1800/2000 m environ, mais encore froide et légère au-dessus, localement travaillée par le vent en altitude dans les secteurs exposés. Corniches et congères parfois volumineuses en place.

Aperçu météo pour le jeudi 05 février

nuit	matin	après-midi	soir

Éclaircies le matin, puis ciel devenant nuageux l'après-midi, avant l'arrivée d'une perturbation neigeuse en fin de journée.

Pluie-Neige				1 500 m
Iso 0 °C	1 600 m	2 200 m	2 100 m	1 900 m
Vent 2000 m	↘ 15 km/h	→ 15 km/h	↑ 20 km/h	← 20 km/h
Vent 3000 m	↘ 35 km/h	↘ 30 km/h	↗ 40 km/h	↑ 50 km/h

Épaisseur de neige hors-piste

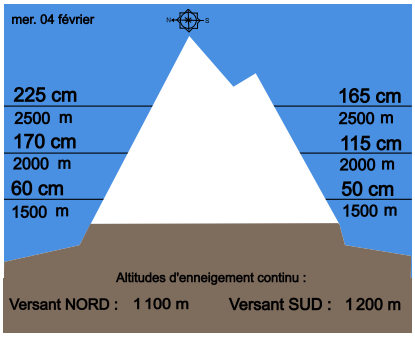

Précipitations à 1800 m

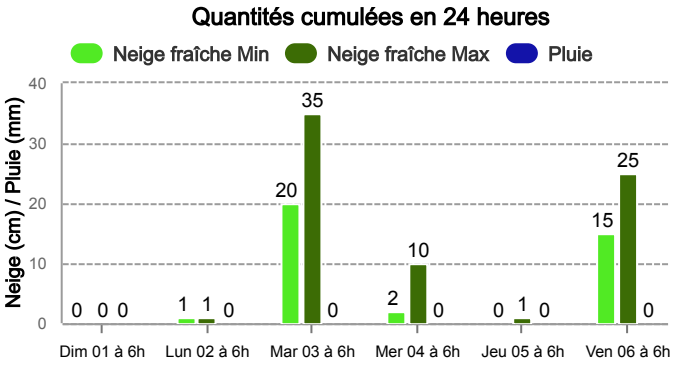

Tendance du vendredi 06 février

Indice de risque fort

risque en hausse avec de nouvelles chutes de neige modérément ventée dans la nuit de jeudi à vendredi.

Pour consulter la vigilance en cours, veuillez vous rendre sur le site https://vigilance.meteofrance.fr/fr

Météo-France - 73 avenue de Paris, 94165 Saint-Mandé cedex - Contact : contact@meteo.fr

Rédigé par Météo-France avec la contribution des observateurs du réseau nivo-météorologiques. Partenariat : ANMSM (Maires de Stations de Montagne), DSF (Domaines Skiables de France), ADSP (Directeurs de Pistes et de la Sécurité des Stations de Sports d'Hiver) et autres acteurs de la montagne.

Bulletin neige & avalanches par téléphone au

0 892 68 10 20 Service 0,35 € / min + prix appel

Bulletin d'estimation du risque d'avalanche

(valable en dehors des pistes balisées et ouvertes)

MASSIF : Haut-Var Haut-Verdon

Rédigé le mercredi 4 février 2026 à 16h

Conditions nivo-météo des 7 derniers jours

	jeu. 29/01				ven. 30/01				sam. 31/01				dim. 01/02				lun. 02/02				mar. 03/02				mer. 04/02			
	03h	09h	15h	21h	03h	09h	15h	21h	03h	09h	15h	21h	03h	09h	15h	21h	03h	09h	15h	21h	03h	09h	15h	21h	03h	09h	15h	21h
Météo																												
Vent (km/h)	45	40	35	20	45	60	50	20	20	20	20	15	20	15	15	15	20	25	40	65	75	50	35	20	25	25	25	20
à 3000m																												
Vent (km/h)	35	25	25	15	20	30	25	10	15	15	15	15	10	10	15	10	10	10	20	30	35	30	20	15	15	20	20	10
à 2000m																												

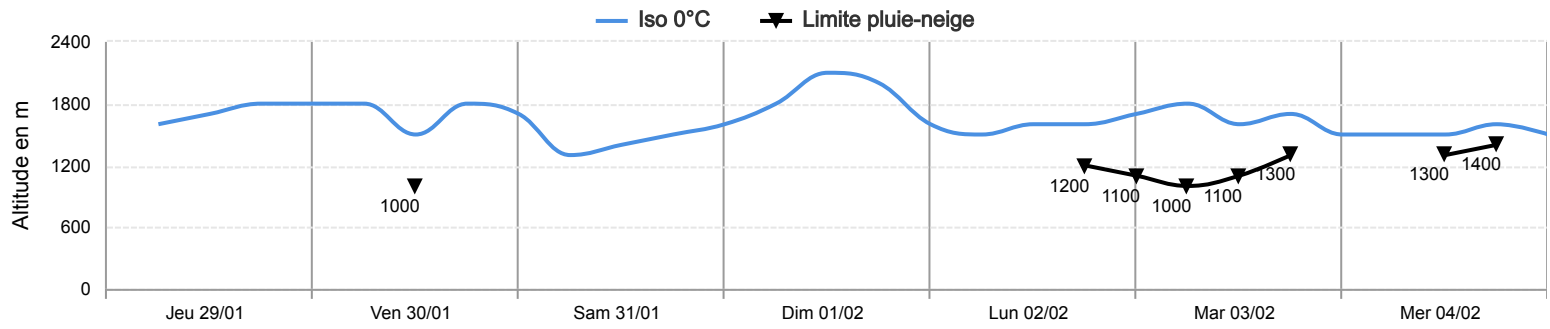

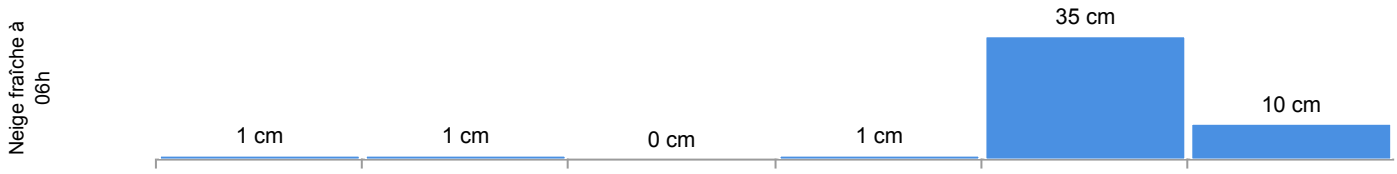

Risque d'avalanche	jeu. 29/01	ven. 30/01	sam. 31/01	dim. 01/02	lun. 02/02	mar. 03/02	mer. 04/02
	4	4	3	3	3	4	3

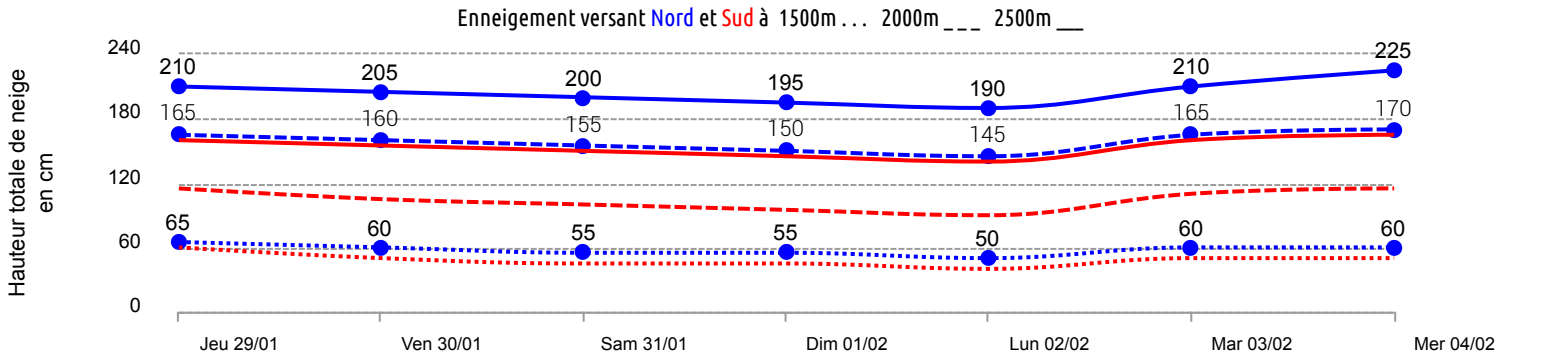

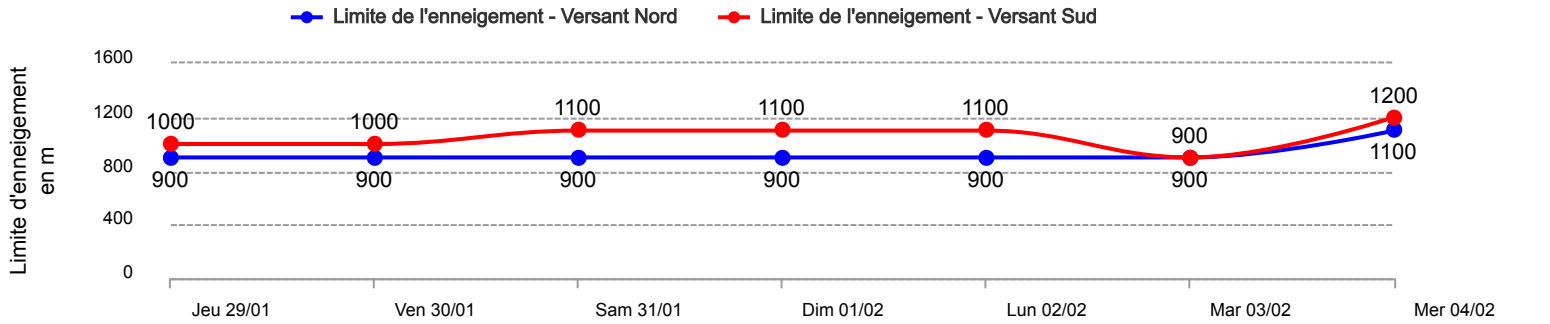

Pour consulter la vigilance en cours, veuillez vous rendre sur le site https://vigilance.meteofrance.fr/fr

Météo-France - 73 avenue de Paris, 94165 Saint-Mandé cedex - Contact : contact@meteo.fr

Bulletin neige & avalanches par téléphone au

0 892 68 10 20 Service 0,35 € / min + prix appel

Rédigé par Météo-France avec la contribution des observateurs du réseau nivo-météorologiques. Partenariat : ANMSM (Maires de Stations de Montagne), DSF (Domaines Skiables de France), ADSP (Directeurs de Pistes et de la Sécurité des Stations de Sports d'Hiver) et autres acteurs de la montagne.