Bulletin d'estimation du risque d'avalanche

(valable en dehors des pistes balisées et ouvertes)

MASSIF : Haute-Ariege

Rédigé le mercredi 4 février 2026 à 16h

Estimation des risques pour le : JEUDI 05 FÉVRIER

PLAQUES À VENT SECTEURS FRONTALIERS ET HUMIDIFICATION BASSE ET MOYENNE ALTITUDE.

2

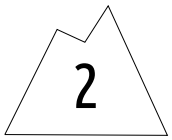

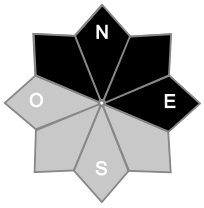

Indice de risque limité.

Départs spontanés : Avalanches de neige humide, surtout l'après-midi avec l'arrivée d"un peu de pluie

Déclenchements provoqués : Plaques à vent , souvent dures, cols et crêtes sommitales en secteur frontalier.

Indices de risque : 5 très fort - 4 fort - 3 marqué - 2 limité - 1 faible -- En noir : les pentes les plus dangereuses

Stabilité du manteau neigeux

Situation avalancheuse typique : neige ventée neige humide

Déclenchements provoqués : dans les cols frontaliers du fond de chaîne : formation possible de plaques à vent dures sous le vent de sud (observable : neige sèche ridée par le vent, transport de neige en cours, accumulation récente).
Facilement déclenchables en haute montagne et pentes bien raides.
Avalanches possibles de taille 1 ou 2 (moyenne), éventuellement 3 en haute montagne vers la frontière Andorrane.
A plus basse altitude, là où croûtes de regel et neige bien humidifiée prédominent en surface, risque plus faible, sauf éventuellement verrou ou vallon très encaissé.

Départs spontanés : Nouvelle humidification notable sous les nuages en dessous de 2200/2300 m, surtout l'après-midi.
Avalanches de glissements possibles en pentes herbeuses ou sur des dalles rocheuses, avalanches de neige humide couloirs très raides. Avalanches de Taille 1 ou 2.

Qualité de la neige

Enneigement :
Malgré le redoux, enneigement excellent et excédentaire pour la saison
Limite d'enneigement skiable remontant toutefois vers 1200/1300 m dans les meilleures configurations.
La fonte va toutefois s'accélérer à basse altitude en cours de journée.

État de la neige :
En matinée, neige dure ou croutée à basse et moyenne altitude. Neige encore sèche ou froide au-delà de 2000/2100 en secteurs frontaliers, regelée sur les crêtes des avants monts.
Re-humidification au moins jusque vers 2200/2300 m en cours de journée sous les nuages accrochant les sommets : apport modeste (5/10 cm de neige récente) au-delà de ces altitudes.

Aperçu météo pour le jeudi 05 février

	nuit	matin	après-midi	soir

Grande douceur et quelques précipitations l'après-midi.

Pluie-Neige			2 100 m	1 900 m
Iso 0 °C	2 100 m	2 600 m	2 500 m	2 200 m
Vent 2000 m	35 km/h	60 km/h	50 km/h	30 km/h
Vent 3000 m	50 km/h	70 km/h	60 km/h	40 km/h

Épaisseur de neige hors-piste

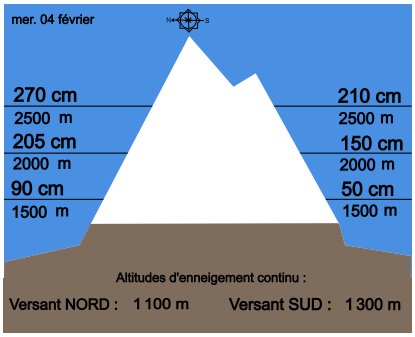

Précipitations à 1800 m

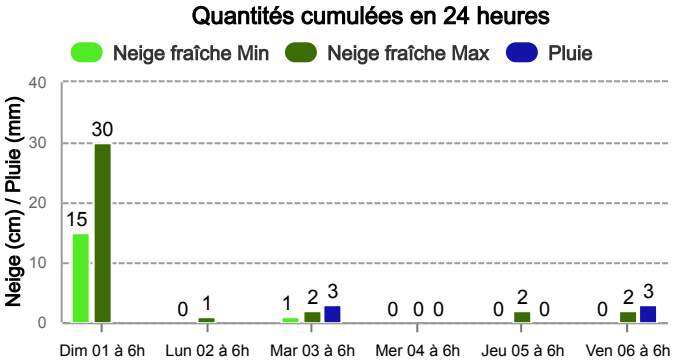

Tendance du vendredi 06 février

2

Indice de risque limité

Risque stationnaire ou en baisse.

Pour consulter la vigilance en cours, veuillez vous rendre sur le site https://vigilance.meteofrance.fr/fr

Météo-France - 73 avenue de Paris, 94165 Saint-Mandé cedex - Contact : contact@meteo.fr

Rédigé par Météo-France avec la contribution des observateurs du réseau nivo-météorologiques. Partenariat : ANMSM (Maires de Stations de Montagne), DSF (Domaines Skiables de France), ADSP (Directeurs de Pistes et de la Sécurité des Stations de Sports d'Hiver) et autres acteurs de la montagne.

Bulletin neige & avalanches par téléphone au

0 892 68 10 20 Service 0,35 € / min + prix appel

RÉPUBLIQUE FRANÇAISE
Liberté Égalité Fraternité

METEO FRANCE
À VOS CÔTÉS, DANS UN CLIMAT QUI CHANGE

Bulletin d'estimation du risque d'avalanche

(valable en dehors des pistes balisées et ouvertes)

MASSIF : Haute-Ariege

Rédigé le mercredi 4 février 2026 à 16h

Conditions nivo-météo des 7 derniers jours

	jeu. 29/01				ven. 30/01				sam. 31/01				dim. 01/02				lun. 02/02				mar. 03/02				mer. 04/02			
	03h	09h	15h	21h	03h	09h	15h	21h	03h	09h	15h	21h	03h	09h	15h	21h	03h	09h	15h	21h	03h	09h	15h	21h	03h	09h	15h	21h
Météo																												
Vent (km/h)	50	50	55	75	80	70	60	40	60	70	70	65	60	35	25	40	60	95	110	85	75	50	55	55	70	70	40	35
à 3000m	↘	↘	↘	↘	↘	↘	↘	↘	↘	↘	↘	↘	↘	↘	↘	↗	↗	↗	↗	↗	↗	↗	↗	↗	↗	↗	→	→
Vent (km/h)	30	30	40	50	55	45	45	25	50	45	45	50	45	15	15	25	35	70	90	55	40	40	35	45	50	55	25	25
à 2000m	↘	→	→	→	→	→	→	→	↗	↘	↘	↓	↘	→	↗	↗	↗	↑	↑	↗	↗	↗	↑	↑	↗	↗	↘	↗

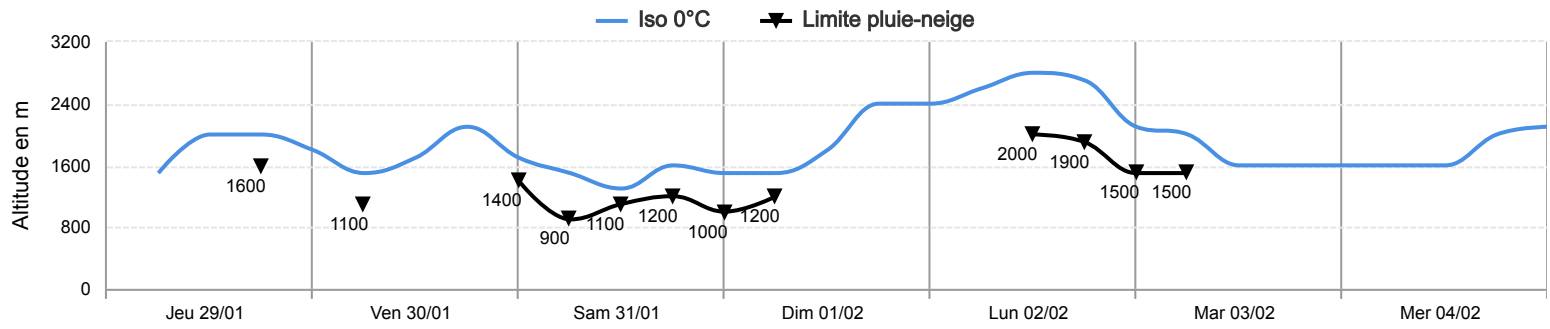

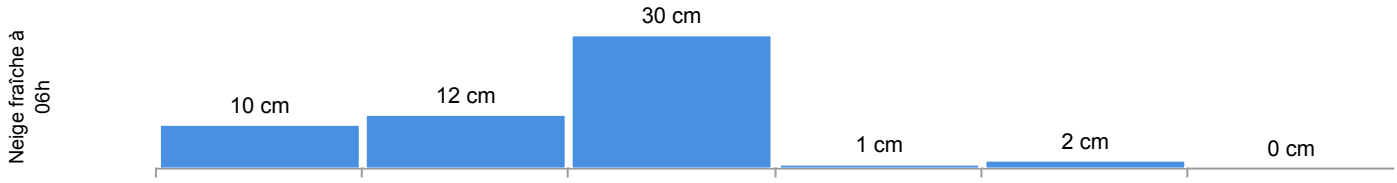

Risque d'avalanche	jeu. 29/01	ven. 30/01	sam. 31/01	dim. 01/02	lun. 02/02	mar. 03/02	mer. 04/02
	3	3	4	4	3	3	3

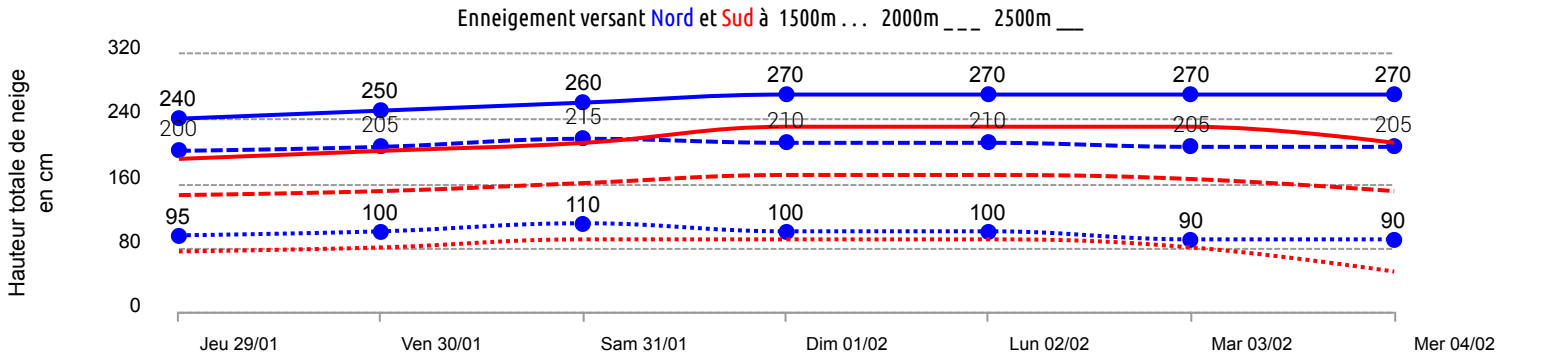

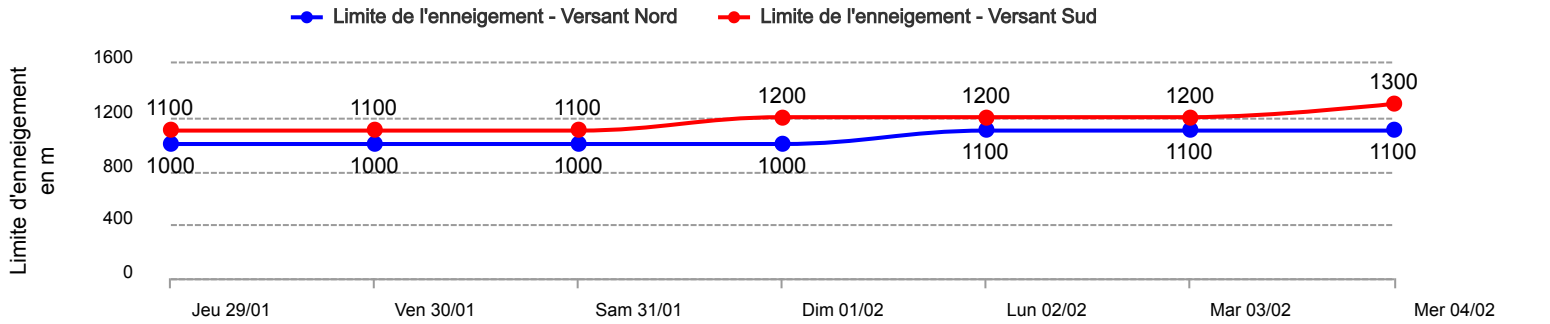

Pour consulter la vigilance en cours, veuillez vous rendre sur le site https://vigilance.meteofrance.fr/fr

Météo-France - 73 avenue de Paris, 94165 Saint-Mandé cedex - Contact : contact@meteo.fr

Bulletin neige & avalanches par téléphone au

0 892 68 10 20 Service 0,35 € / min + prix appel

Rédigé par Météo-France avec la contribution des observateurs du réseau nivo-météorologiques. Partenariat : ANMSM (Maires de Stations de Montagne), DSF (Domaines Skiables de France), ADSP (Directeurs de Pistes et de la Sécurité des Stations de Sports d'Hiver) et autres acteurs de la montagne.