Bulletin d'estimation du risque d'avalanche

(valable en dehors des pistes balisées et ouvertes)

MASSIF : Orlu St-Barthelemy

Rédigé le mercredi 4 février 2026 à 16h

Estimation des risques pour le : JEUDI 05 FÉVRIER

INSTABILITÉ ENCORE MARQUÉE EN HAUTE MONTAGNE, ACTIVITÉ EN NEIGE HUMIDE À BASSE ET MOYENNE ALTITUDE.

3

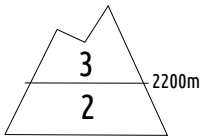

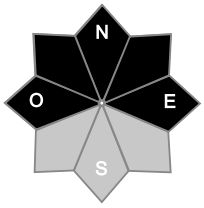

Au-dessus de 2200m indice de risque marqué, plus bas indice limité.

Départs spontanés : Avalanches de neige humide, surtout l'après-midi avec l'arrivée d''un peu de pluie

Déclenchements provoqués : plaques à vent secteurs expo au vent de sud, sous couches fragiles persistantes possibles en haute montagne.

Indices de risque : 5 très fort - 4 fort - 3 marqué - 2 limité - 1 faible -- En noir : les pentes les plus dangereuses

Stabilité du manteau neigeux

Situation avalancheuse typique : couche fragile persistante neige humide

Déclenchements provoqués :
*En Haute montagne, anciennes structures de plaques avec sous-couches fragiles persistantes (avérées il y a quelques jours) encore possible en secteurs ombragés (observables : neige sèche en surface, bruits d'effondrement au sein du manteau neigeux ou fissures au passage d'un randonneur). Facilement déclenchables en haute montagne et pentes bien raides.
*Secteurs Orlu/Bésines: formation ponctuelle de plaques à vent dures sous le vent de sud (observables : neige sèche ridée par le vent, transport de neige en cours, accumulation récente).
Avalanches possibles de taille 1 ou 2 (moyenne), éventuellement 3 en haute montagne

Départs spontanés : Nouvelle humidification notable sous les nuages en dessous de 2200/2300 m, surtout l'après-midi.
Avalanches de glissements possibles en pentes herbeuses ou sur des dalles rocheuses, avalanches de neige humide couloirs très raides. Avalanches de Taille 1 ou 2.

Qualité de la neige

Enneigement :
Malgré le redoux, enneigement excellent et excédentaire pour la saison, en particulier sur Orlu et aux confins des Pyrénées orientales.
Limite d'enneigement skiable remontant toutefois vers 1200/1300 m dans les meilleures configurations.
La fonte va toutefois s'accélérer à basse altitude en cours de journée.

État de la neige :
En matinée, neige dure ou croutée à basse et moyenne altitude. Neige encore sèche ou froide au-delà de 2000/2100 en allant vers le secteur des Bésines ou d'en garcia.
Re-humidification au moins jusque vers 2200/2300 m en cours de journée sous les nuages accrochant les sommets : apport modeste de quelques centimètres au-delà de ces altitudes.

Aperçu météo pour le jeudi 05 février

Grande douceur et quelques précipitations l'après-midi.

	nuit	matin	après-midi	soir
Pluie-Neige			2 200 m	2 000 m
Iso 0 °C	2 100 m	2 600 m	2 500 m	2 300 m
Vent 2000 m	↗ 30 km/h	↗ 40 km/h	↗ 45 km/h	→ 40 km/h
Vent 3000 m	→ 50 km/h	→ 55 km/h	→ 60 km/h	→ 55 km/h

Épaisseur de neige hors-piste

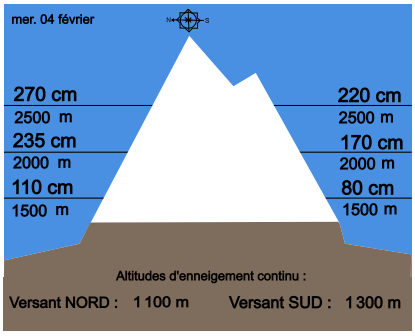

Précipitations à 1800 m

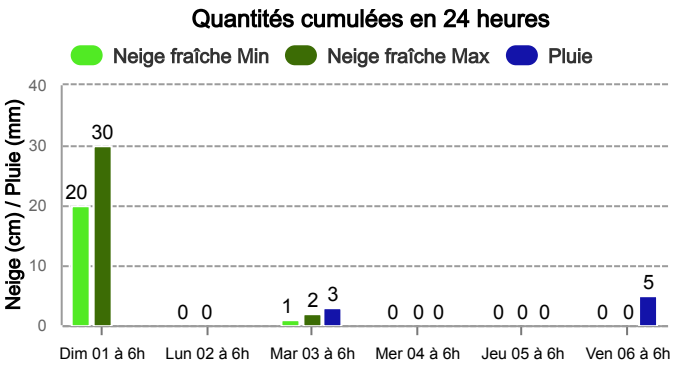

Tendance du vendredi 06 février

3 **Indice de risque marqué**

Risque plutôt en baisse.

Pour consulter la vigilance en cours, veuillez vous rendre sur le site https://vigilance.meteofrance.fr/fr

Météo-France - 73 avenue de Paris, 94165 Saint-Mandé cedex - Contact : contact@meteo.fr

Rédigé par Météo-France avec la contribution des observateurs du réseau nivo-météorologiques. Partenariat : ANMSM (Maires de Stations de Montagne), DSF (Domaines Skiables de France), ADSP (Directeurs de Pistes et de la Sécurité des Stations de Sports d'Hiver) et autres acteurs de la montagne.

Bulletin neige & avalanches par téléphone au
0 892 68 10 20 Service 0,35 € / min + prix appel

Bulletin d'estimation du risque d'avalanche

(valable en dehors des pistes balisées et ouvertes)

MASSIF : Orlu St-Barthelemy

Rédigé le mercredi 4 février 2026 à 16h

Conditions nivo-météo des 7 derniers jours

	jeu. 29/01				ven. 30/01				sam. 31/01				dim. 01/02				lun. 02/02				mar. 03/02				mer. 04/02			
	03h	09h	15h	21h	03h	09h	15h	21h	03h	09h	15h	21h	03h	09h	15h	21h	03h	09h	15h	21h	03h	09h	15h	21h	03h	09h	15h	21h
Météo																												
Vent (km/h)	50	50	55	75	80	70	60	40	65	75	80	70	60	40	30	30	45	70	100	70	60	35	40	30	40	65	55	45
à 3000m																												
Vent (km/h)	30	30	40	50	55	45	45	25	35	55	55	50	40	25	20	15	20	45	75	50	40	25	25	20	30	50	45	30
à 2000m																												

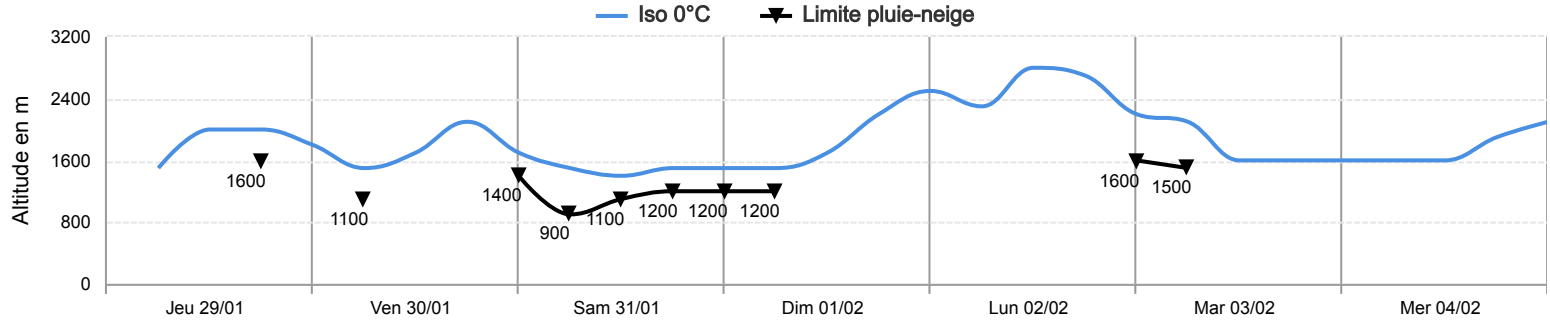

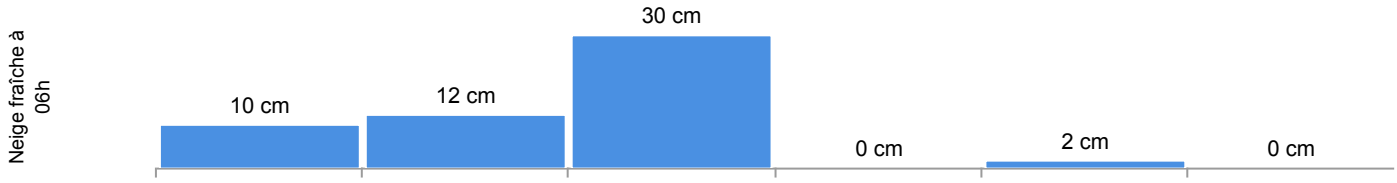

Risque d'avalanche	jeu. 29/01	ven. 30/01	sam. 31/01	dim. 01/02	lun. 02/02	mar. 03/02	mer. 04/02
	3	3	4	4	3	3	3

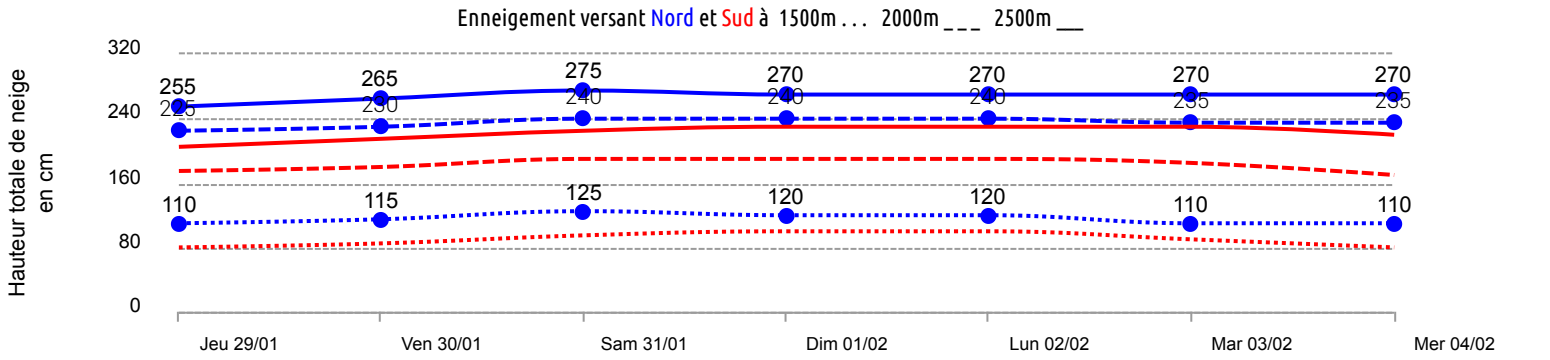

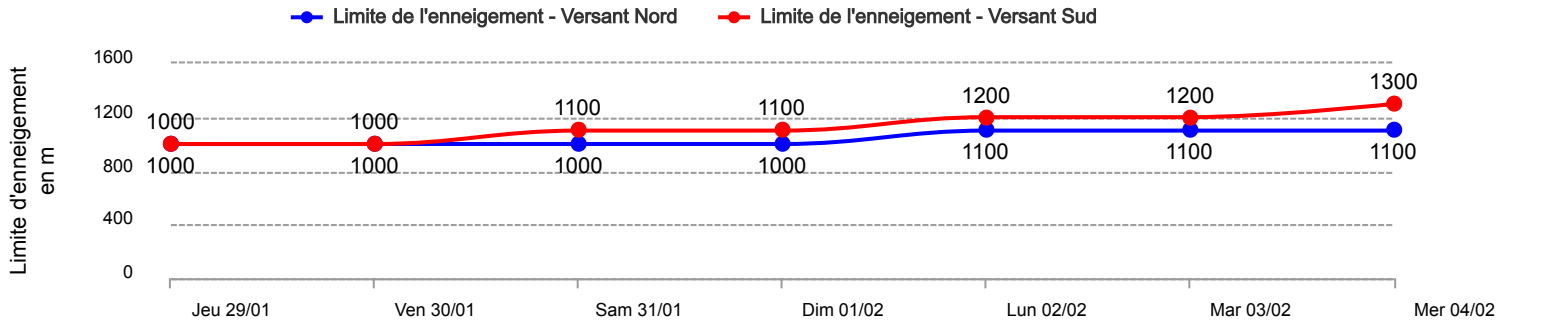

Pour consulter la vigilance en cours, veuillez vous rendre sur le site https://vigilance.meteofrance.fr/fr

Météo-France - 73 avenue de Paris, 94165 Saint-Mandé cedex - Contact : contact@meteo.fr

Bulletin neige & avalanches par téléphone au

0 892 68 10 20 Service 0,35 € / min + prix appel

Rédigé par Météo-France avec la contribution des observateurs du réseau nivo-météorologiques. Partenariat : ANMSM (Maires de Stations de Montagne), DSF (Domaines Skiables de France), ADSP (Directeurs de Pistes et de la Sécurité des Stations de Sports d'Hiver) et autres acteurs de la montagne.