RÉPUBLIQUE FRANÇAISE
Liberté Égalité Fraternité

METEO FRANCE
À VOS CÔTÉS, DANS UN CLIMAT QUI CHANGE

Bulletin d'estimation du risque d'avalanche
(valable en dehors des pistes balisées et ouvertes)
MASSIF : Pays-Basque

Rédigé le mercredi 4 février 2026 à 16h

Estimation des risques pour le : JEUDI 05 FÉVRIER

MANTEAU NEIGEUX FORTEMENT VENTE EN COURS D'HUMIDIFICATION.

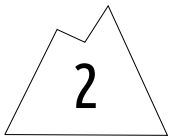

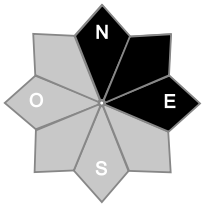

Indice de risque limité.

Départs spontanés : ponctuels en neige humide, cassures linéaires en neige ventée.

Déclenchements provoqués : plaques peu épaisses en nord à est au-dessus de 1800/1900m.

Indices de risque : 5 très fort - 4 fort - 3 marqué - 2 limité - 1 faible -- En noir : les pentes les plus dangereuses

Stabilité du manteau neigeux

Situation avalancheuse typique : neige ventée neige humide

Déclenchements provoqués : possibles par **faible sollicitation des plaques peu épaisses dans les pentes nord à est**. Avec le vent fort, ces plaques se sont **formées loin des crêtes, cols et sommets** dans les secteurs déventés, la neige récente et sèche a été très éparpillée, ne permettant que de **faibles accumulations**. Un **seul skieur ou randonneur** peut donc **facilement déclencher une avalanche de plaque de taille 1, très localement de taille 2**.
Dans tous les autres secteurs, neige très travaillée par le vent, dure et en cours d'humidification, constituant un manteau neigeux stable et peu sensible au sollicitation.

Départs spontanés : départs **peu fréquents et en pentes raides**, se répartissant comme suit :
- **en neige sèche dans les versants nord à est** : départs **ponctuels de coulée ou petite avalanche partant d'une petite accumulation de neige sèche au plus haut du massif**, quelques **cassures linéaires par déclenchement des plaques** décrites ci-dessus par **surcharge avec l'apport supplémentaire de neige transportée par le vent**, souvent de **petite taille**, **très localement de taille moyenne en partant d'une accumulation un peu plus importante** (constituée par exemple dans une combe ou un couloir raides nord à nord-est déventés).
- **en neige humide** : sous 1900m d'altitude et dans tous les autres versants, l'humidification est à l'origine de départs ponctuels de neige alourdie.

Autres : à l'exception des pentes nord à est, manteau neigeux dur et glissant en début de matinée (durci par le vent sous 1800/1900m, regelé au-dessus).

Qualité de la neige

Enneigement : assez bon pour la saison, mais les crêtes, cols et sommets sont souvent pelés par le vent dans les expositions ouest. Le manteau neigeux s'est bien humidifié sous 1800/1900m, mais ne fond que très lentement.
Limites skiables : manteau neigeux skiable à partir de 1400/1500m avec sous couche portante.
État de la neige : neige durcie et portante, regelée au-dessus de 1800/1900m, tassée par le vent et l'humidification en dessous, très frittée près des cols, crêtes et sommets. Quelques centimètres de neige fraîche et encore sèche déposés au-dessus de 1800m dans les pentes nord à est. Peu d'évolution en journée du manteau neigeux en place dans les pentes nord à est et au-dessus de 1800m, la neige ramollit et s'humidifie lentement partout ailleurs

Aperçu météo pour le jeudi 05 février

quelques averses, redoux léger, vent de sud à sud-ouest fort.

	nuit	matin	après-midi	soir
Pluie-Neige		1 900 m	1 700 m	
Iso 0 °C	2 300 m	2 500 m	2 100 m	1 800 m
Vent 1000 m	35 km/h	50 km/h	40 km/h	25 km/h
Vent 2000 m	90 km/h	110 km/h	90 km/h	80 km/h

Épaisseur de neige hors-piste

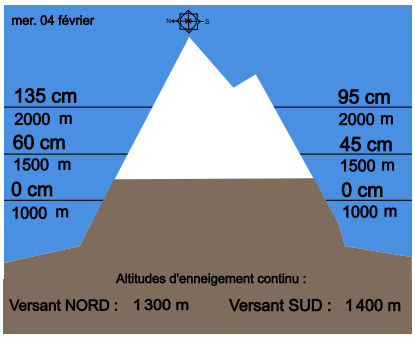

Précipitations à 1800 m

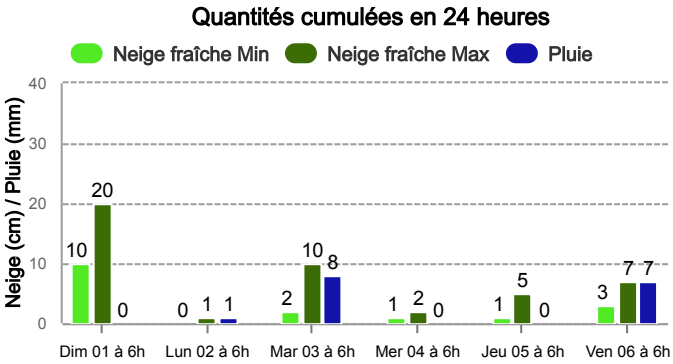

Tendance du vendredi 06 février

Indice de risque limité

Vers du temps plus sec mais rafraîchi, le risque restera limité.

Pour consulter la vigilance en cours, veuillez vous rendre sur le site https://vigilance.meteofrance.fr/fr

Météo-France - 73 avenue de Paris, 94165 Saint-Mandé cedex - Contact : contact@meteo.fr

Rédigé par Météo-France avec la contribution des observateurs du réseau nivo-météorologiques. Partenariat : ANMSM (Maires de Stations de Montagne), DSF (Domaines Skiables de France), ADSP (Directeurs de Pistes et de la Sécurité des Stations de Sports d'Hiver) et autres acteurs de la montagne.

Bulletin neige & avalanches par téléphone au
0 892 68 10 20 Service 0,35 € / min + prix appel

RÉPUBLIQUE FRANÇAISE
Liberté Égalité Fraternité

METEO FRANCE
À VOS CÔTÉS, DANS UN CLIMAT QUI CHANGE

Bulletin d'estimation du risque d'avalanche

(valable en dehors des pistes balisées et ouvertes)

MASSIF : Pays-Basque

Rédigé le mercredi 4 février 2026 à 16h

Conditions nivo-météo des 7 derniers jours

	jeu. 29/01				ven. 30/01				sam. 31/01				dim. 01/02				lun. 02/02				mar. 03/02				mer. 04/02			
	03h	09h	15h	21h	03h	09h	15h	21h	03h	09h	15h	21h	03h	09h	15h	21h	03h	09h	15h	21h	03h	09h	15h	21h	03h	09h	15h	21h
Météo																												
Vent (km/h)	65	80	75	75	80	95	65	80	70	90	90	60	70	45	50	80	95	120	120	80	80	80	65	80	100	85	65	70
à 2000m	↗	↗	↗	→	↗	↗	↗	↗	↑	→	↘	↘	↘	↗	↗	↑	↑	↑	↑	↗	↗	↑	↑	↑	↑	↗	→	↗
Vent (km/h)	45	50	50	50	50	65	40	50	50	70	70	35	30	30	40	60	60	90	90	55	55	55	40	45	50	40	20	30
à 1000m	↑	↗	↗	↗	↗	↑	↑	→	→	→	→	→	→	↑	↑	↑	↑	↑	↑	↗	↑	↑	↑	↑	↑	↑	↑	↑

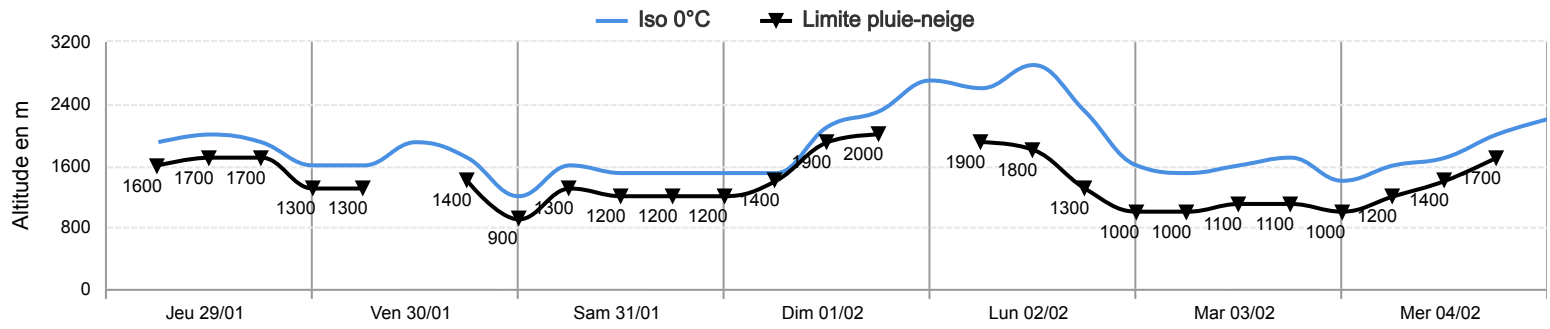

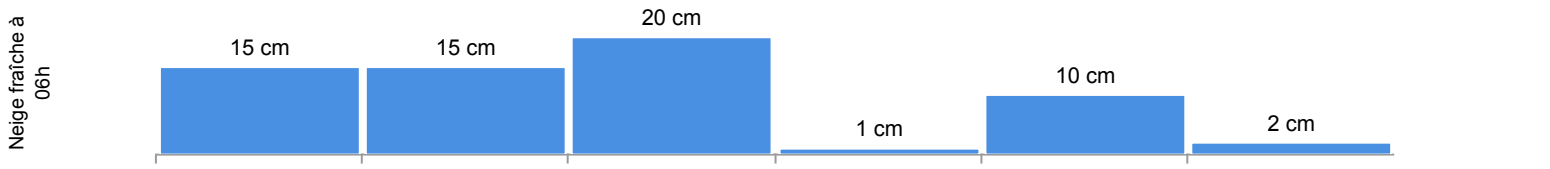

Risque d'avalanche	jeu. 29/01	ven. 30/01	sam. 31/01	dim. 01/02	lun. 02/02	mar. 03/02	mer. 04/02
	2	3	4	3	3	2	2

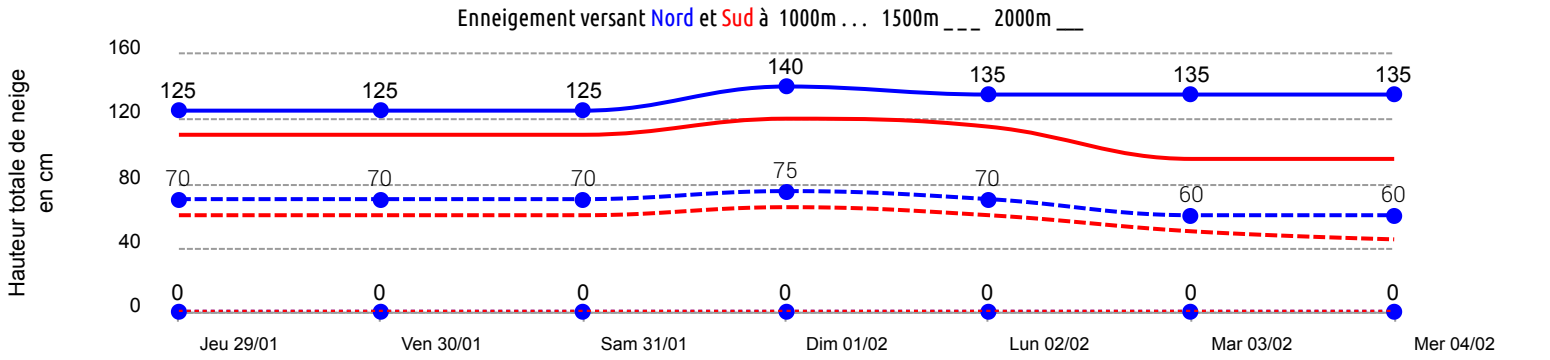

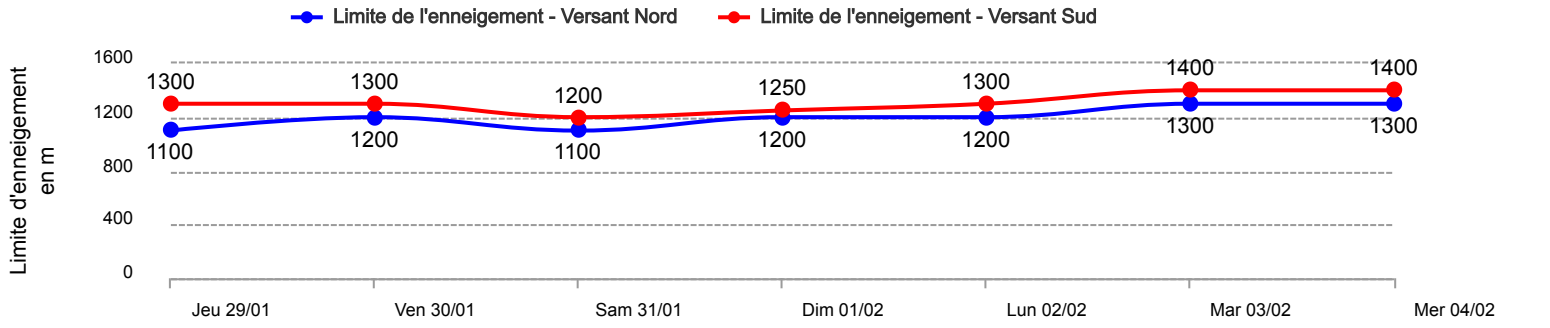

Pour consulter la vigilance en cours, veuillez vous rendre sur le site https://vigilance.meteofrance.fr/fr

Météo-France - 73 avenue de Paris, 94165 Saint-Mandé cedex - Contact : contact@meteo.fr

Rédigé par Météo-France avec la contribution des observateurs du réseau nivo-météorologiques. Partenariat : ANMSM (Maires de Stations de Montagne), DSF (Domaines Skiables de France), ADSP (Directeurs de Pistes et de la Sécurité des Stations de Sports d'Hiver) et autres acteurs de la montagne.

Bulletin neige & avalanches par téléphone au

0 892 68 10 20 Service 0,35 € / min + prix appel