Bulletin d'estimation du risque d'avalanche
(valable en dehors des pistes balisées et ouvertes)

MASSIF : Pelvoux

Rédigé le mercredi 4 février 2026 à 16h

Estimation des risques pour le : JEUDI 05 FÉVRIER

INSTABILITÉ ENCORE MARQUÉE DANS LA NEIGE RÉCENTE ; MANTEAU NEIGEUX PIÉGEUX, PEU D'OBSERVABLES

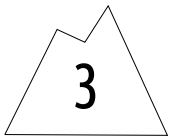

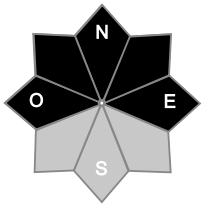

Indice de risque marqué.

Départs spontanés : taille moyenne à grande, sous l'effet du vent et des chutes de neige en fin de journée

Déclenchements provoqués : instabilités parfois très volumineuses en versants froids

Indices de risque : 5 très fort - 4 fort - 3 marqué - 2 limité - 1 faible -- En noir : les pentes les plus dangereuses

Stabilité du manteau neigeux

Situation avalancheuse typique : couche fragile persistante neige ventée

Déclenchements provoqués : le manteau neigeux reste peu stabilisé dans de nombreuses pentes. Ces instabilités se situent principalement en orientations ouest, nord et est , y compris dans les pentes a priori peu dangereuses comme celles déjà skiées, ou en forêts clairsemées. Un seul skieur peut encore facilement les déclencher, parfois à distance, et générer des avalanches de plaques d'aspect poudreux de taille moyenne à parfois grande, avec large et épaisse cassure, quand la topographie s'y prête, notamment au-dessus de 2000 m. La chute de neige la nuit de lundi à mardi repose en effet sur un manteau neigeux instable, constitué d'un empilement de couches fragiles non détectables depuis la surface.
Des instabilités plus facilement identifiables se sont formées jusqu'à mercredi matin sous l'effet du vent de sud à est. De nouvelles se forment en cours de journée de jeudi. Localisées dans les secteurs d'accumulation par le vent, parfois loin des crêtes, le déclenchement de ces plaques plutôt dures peut cependant solliciter en cascade ces couches fragiles persistantes enfouies.

Départs spontanés : avalanches de plaques possibles en fin de journée sous l'effet du fort vent de secteur sud en altitude. Taille petite à moyenne, grande possible en soirée avec l'accumulation de neige fraîche.
Par ailleurs, petits départs ponctuels en neige humide, taille petite à moyenne, en versants est à sud non encore purgés. Le retour provisoire du soleil jeudi matin s'effectue dans une masse d'air doux, qui favorise l'humidification du manteau neigeux, en versants raides ensoleillés.

Qualité de la neige

L'enneigement est désormais excédentaire pour un début février.
Données observées : 166 cm à la Nivôse de Écrins vers 3000 m soufflée par le vent, 171 cm au Pré de Madame Carle à 1900 m, 115 cm au hameau de Dormillouse à 1730 m.

Limite d'enneigement skiable : dès les fonds de vallées, mais avec une sous-couche un peu limite sous 1500 m en adrets.

État de la neige de surface : le matin, 20/40 cm de neige récente, parfois densifiée ou durcie par le vent près des crêtes, mais encore poudreuse dans les pentes abritées notamment en forêts. En versants sud, croûte superficielle jusque 1800/2000 m le matin, l'humidification se poursuit avec le soleil et la remontée de l'iso 0 avant la neige.
Crêtes bien chargées.

Aperçu météo pour le jeudi 05 février

	nuit	matin	après-midi	soir
Pluie-Neige			1 400 m	1 000 m
Iso 0 °C	1 600 m	1 900 m	2 100 m	1 600 m
Vent 2000 m	10 km/h	10 km/h	20 km/h	10 km/h
Vent 3000 m	15 km/h	30 km/h	45 km/h	25 km/h

Beau le matin, devenant voilé dense en début d'après-midi (jour blanc), neige à partir du milieu d'après-midi, forte le soir

Épaisseur de neige hors-piste

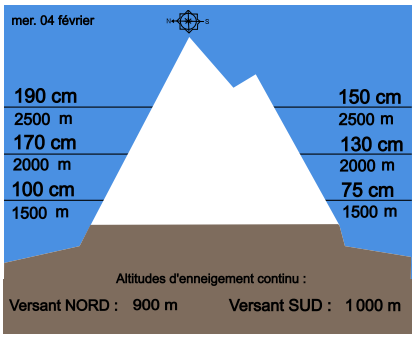

Précipitations à 1800 m

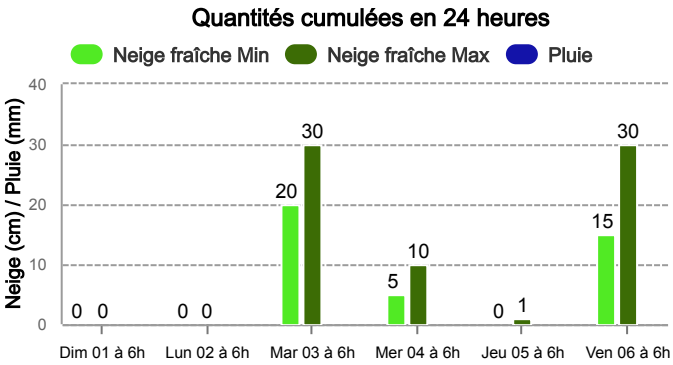

Tendance du vendredi 06 février

Indice de risque fort

En hausse. Nombreuses nouvelles instabilité formées après la chute de neige de jeudi soir. Risque fort.

Pour consulter la vigilance en cours, veuillez vous rendre sur le site https://vigilance.meteofrance.fr/fr

Météo-France - 73 avenue de Paris, 94165 Saint-Mandé cedex - Contact : contact@meteo.fr

Rédigé par Météo-France avec la contribution des observateurs du réseau nivo-météorologiques. Partenariat : ANMSM (Maires de Stations de Montagne), DSF (Domaines Skiables de France), ADSP (Directeurs de Pistes et de la Sécurité des Stations de Sports d'Hiver) et autres acteurs de la montagne.

Bulletin neige & avalanches par téléphone au
0 892 68 10 20 Service 0,35 € / min + prix appel

RÉPUBLIQUE FRANÇAISE
Liberté Égalité Fraternité

METEO FRANCE
À VOS CÔTÉS, DANS UN CLIMAT QUI CHANGE

Bulletin d'estimation du risque d'avalanche

(valable en dehors des pistes balisées et ouvertes)

MASSIF : Pelvoux

Rédigé le mercredi 4 février 2026 à 16h

Conditions nivo-météo des 7 derniers jours

	jeu. 29/01				ven. 30/01				sam. 31/01				dim. 01/02				lun. 02/02				mar. 03/02				mer. 04/02			
	03h	09h	15h	21h	03h	09h	15h	21h	03h	09h	15h	21h	03h	09h	15h	21h	03h	09h	15h	21h	03h	09h	15h	21h	03h	09h	15h	21h
Météo																												
Vent (km/h)	40	30	20	20	20	25	30	10	15	15	5	10	10	10	15	15	20	25	40	60	100	70	40	30	30	30	20	15
à 3000m																												
Vent (km/h)	30	20	15	10	10	10	20	10	10	10	10	10	10	10	10	10	10	15	20	20	60	35	25	15	15	15	15	10
à 2000m																												

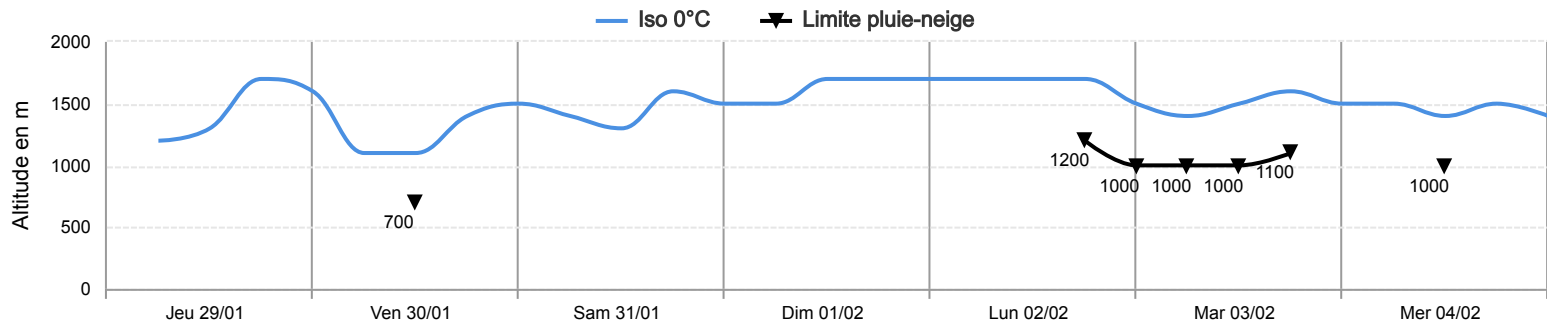

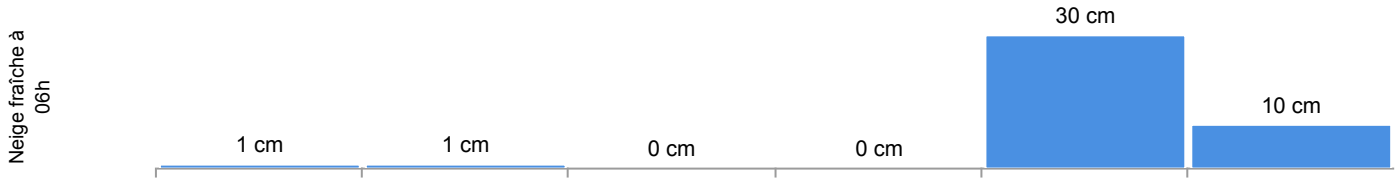

Risque d'avalanche	jeu. 29/01	ven. 30/01	sam. 31/01	dim. 01/02	lun. 02/02	mar. 03/02	mer. 04/02
	4	4	3	3	3	4	4

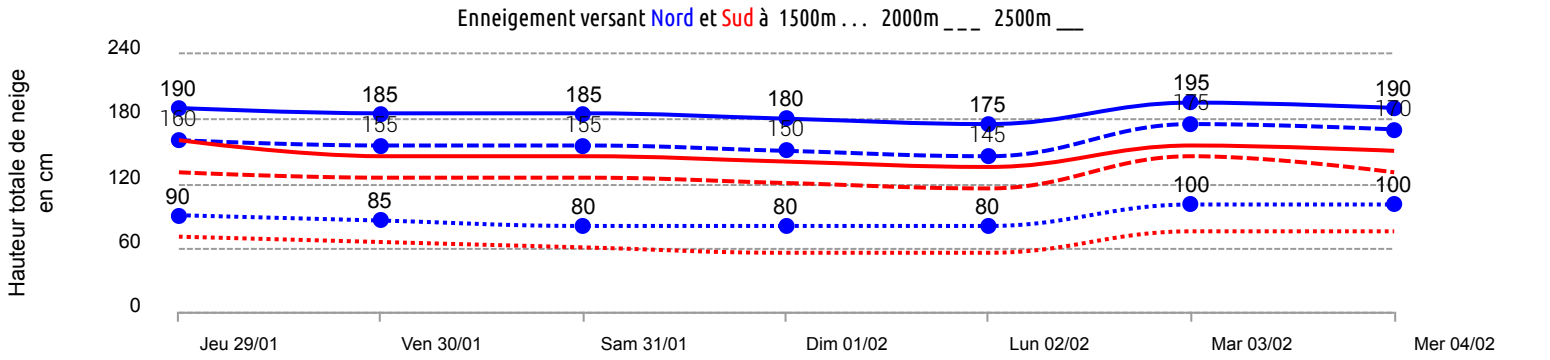

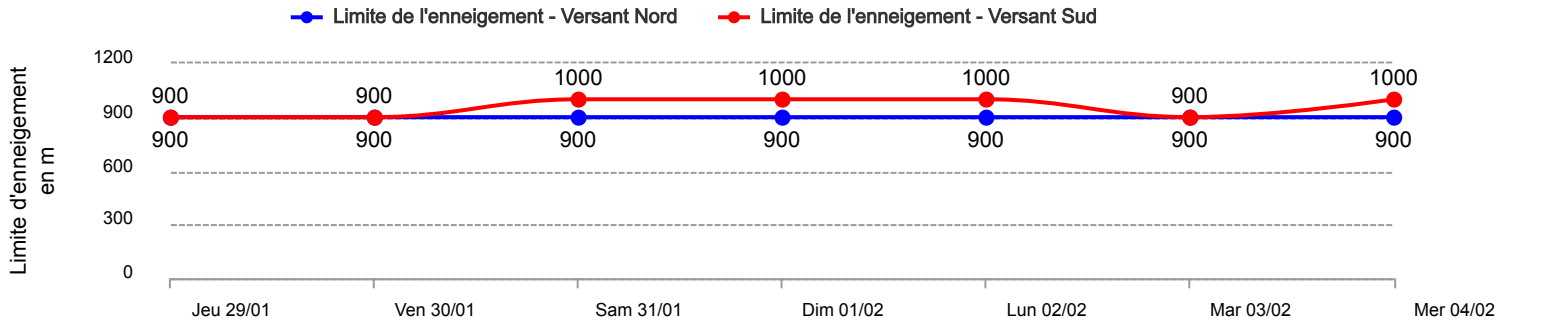

Pour consulter la vigilance en cours, veuillez vous rendre sur le site https://vigilance.meteofrance.fr/fr

Météo-France - 73 avenue de Paris, 94165 Saint-Mandé cedex - Contact : contact@meteo.fr

Rédigé par Météo-France avec la contribution des observateurs du réseau nivo-météorologiques. Partenariat : ANMSM (Maires de Stations de Montagne), DSF (Domaines Skiables de France), ADSP (Directeurs de Pistes et de la Sécurité des Stations de Sports d'Hiver) et autres acteurs de la montagne.

Bulletin neige & avalanches par téléphone au

0 892 68 10 20 Service 0,35 € / min + prix appel