Bulletin d'estimation du risque d'avalanche

(valable en dehors des pistes balisées et ouvertes)

MASSIF : Vercors

Rédigé le mercredi 4 février 2026 à 16h

Estimation des risques pour le : JEUDI 05 FÉVRIER

PRÉSENCE D'INSTABILITÉS EN VERSANTS FROIDS D'ALTITUDE.

3

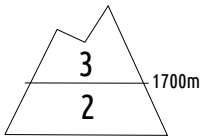

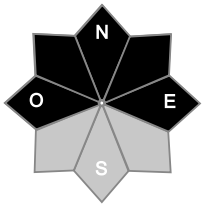

Au-dessus de 1700m indice de risque marqué, plus bas indice limité.

Départs spontanés : Rares.

Déclenchements provoqués : Plaques dures formées par le vent de sud.

Indices de risque : 5 très fort - 4 fort - 3 marqué - 2 limité - 1 faible -- En noir : les pentes les plus dangereuses

Stabilité du manteau neigeux

Situation avalancheuse typique : neige ventée couche fragile persistante

Déclenchements provoqués : Le manteau neigeux est en cours de stabilisation aux altitudes les plus basses et dans les versants bien ensoleillés suffisamment raides. Le transport de neige dû au vent d'un large secteur sud a favorisé la formation de plaques, plutôt dures et généralement détectables en observant le terrain, parfois loin des crêtes. Les zones les plus suspectes se situent en versants froids au dessus de 1700 m. Il n'est pas impossible que le déclenchement d'une plaque par un skieur puisse provoquer un départ plus conséquent sur le trajet de l'avalanche en sollicitant des couches fragiles anciennes, enfouies dans le manteau neigeux.

Départs spontanés : l'activité naturelle devrait être réduite jeudi à une éventuelle plaque se décrochant spontanément sous le poids de la neige rapportée par le vent de sud.

Qualité de la neige

Qualification de l'enneigement : l'enneigement est redevenu correct voire bon pour la saison, mais l'épisode de vent de Sud modifie beaucoup la répartition spatiale de la neige.

Limites skiables : vers 1100/1400 m, hors sapins.

Qualité de la neige jeudi : neige poudreuse dans certaines pentes à l'ombre et à l'abri du vent. Neige croûtée puis lourde dans les versants au soleil jusqu'au moins 1800 m. Neige fortement soufflée et densifiée près des crêtes avec des cailloux qui ressortent par endroits.

Aperçu météo pour le jeudi 05 février

	nuit	matin	après-midi	soir
Pluie-Neige			1 500 m	1 600 m
Iso 0 °C	1 600 m	1 900 m	2 100 m	2 000 m
Vent 1500 m	25 km/h	20 km/h	45 km/h	30 km/h
Vent 2000 m	25 km/h	35 km/h	50 km/h	45 km/h

Épaisseur de neige hors-piste

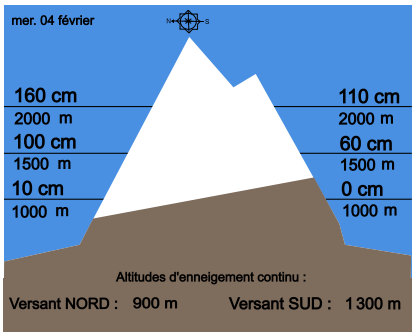

Précipitations à 1800 m

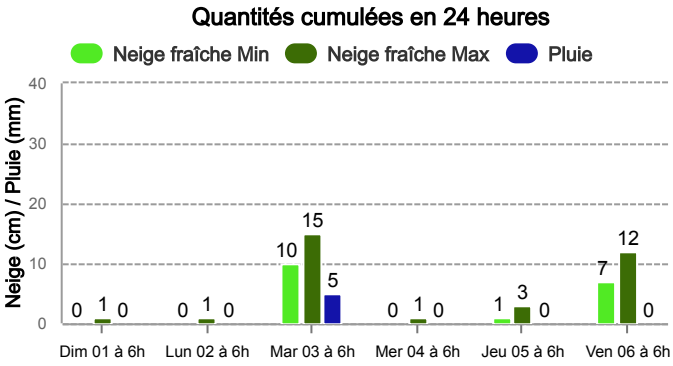

Tendance du vendredi 06 février

3

Indice de risque marqué

La petite chute de neige attendue à partir de jeudi soir devrait augmenter temporairement les risques. De petites purges de neige fraîche se produiront spontanément vendredi.

Pour consulter la vigilance en cours, veuillez vous rendre sur le site https://vigilance.meteofrance.fr/fr

Météo-France - 73 avenue de Paris, 94165 Saint-Mandé cedex - Contact : contact@meteo.fr

Rédigé par Météo-France avec la contribution des observateurs du réseau nivo-météorologiques. Partenariat : ANMSM (Maires de Stations de Montagne), DSF (Domaines Skiables de France), ADSP (Directeurs de Pistes et de la Sécurité des Stations de Sports d'Hiver) et autres acteurs de la montagne.

Bulletin neige & avalanches par téléphone au

0 892 68 10 20 Service 0,35 € / min + prix appel

RÉPUBLIQUE FRANÇAISE
Liberté Égalité Fraternité

METEO FRANCE
À VOS CÔTÉS, DANS UN CLIMAT QUI CHANGE

Bulletin d'estimation du risque d'avalanche

(valable en dehors des pistes balisées et ouvertes)

MASSIF : Vercors

Rédigé le mercredi 4 février 2026 à 16h

Conditions nivo-météo des 7 derniers jours

	jeu. 29/01				ven. 30/01				sam. 31/01				dim. 01/02				lun. 02/02				mar. 03/02				mer. 04/02			
	03h	09h	15h	21h	03h	09h	15h	21h	03h	09h	15h	21h	03h	09h	15h	21h	03h	09h	15h	21h	03h	09h	15h	21h	03h	09h	15h	21h
Météo																												
Vent (km/h)	45	25	15	30	45	35	25	20	20	15	20	20	20	20	20	20	25	55	80	120	125	90	75	70	45	50	50	30
à 2000m																												
Vent (km/h)	20	5	0	15	30	20	15	15	15	10	15	10	15	15	15	15	15	35	65	100	110	75	55	50	40	45	40	25
à 1500m																												

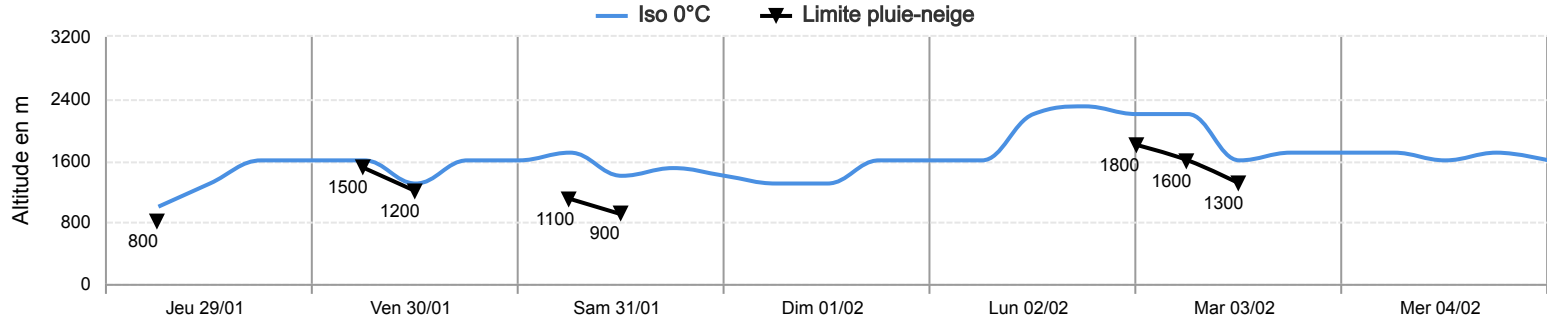

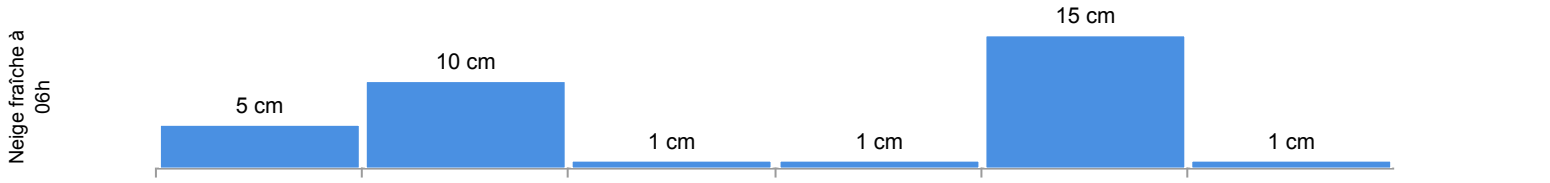

Risque d'avalanche	jeu. 29/01	ven. 30/01	sam. 31/01	dim. 01/02	lun. 02/02	mar. 03/02	mer. 04/02
	3	3	2	2	3	3	3

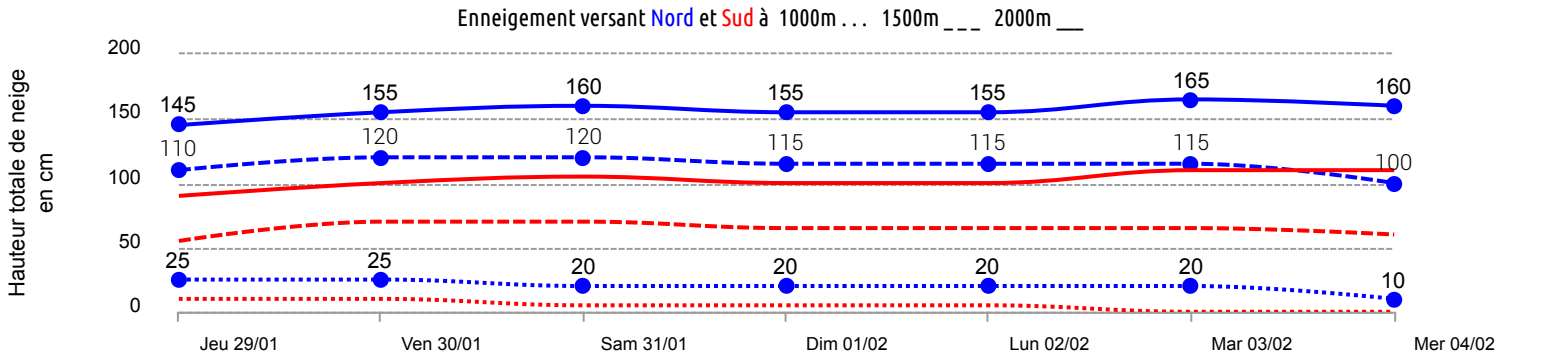

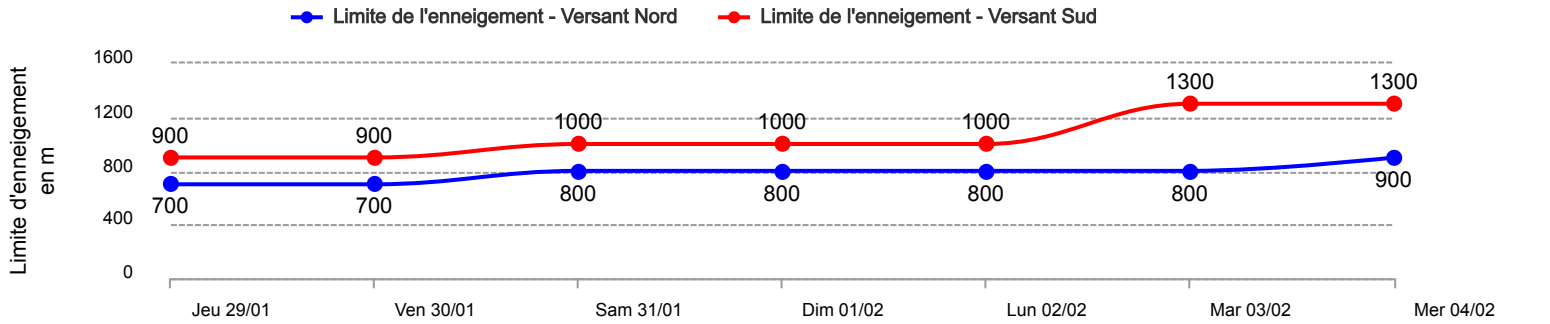

Pour consulter la vigilance en cours, veuillez vous rendre sur le site https://vigilance.meteofrance.fr/fr

Météo-France - 73 avenue de Paris, 94165 Saint-Mandé cedex - Contact : contact@meteo.fr

Rédigé par Météo-France avec la contribution des observateurs du réseau nivo-météorologiques. Partenariat : ANMSM (Maires de Stations de Montagne), DSF (Domaines Skiables de France), ADSP (Directeurs de Pistes et de la Sécurité des Stations de Sports d'Hiver) et autres acteurs de la montagne.

Bulletin neige & avalanches par téléphone au

0 892 68 10 20 Service 0,35 € / min + prix appel