GOBIERNO DE ESPAÑA
VICEPRESIDENCIA TERCERA DEL GOBIERNO
MINISTERIO PARA LA TRANSICIÓN ECOLÓGICA Y EL RETO DEMOGRÁFICO

Boletín de información nivológica y de peligro de aludes

Pirineo Catalán

aemet Agencia Estatal de Meteorología

jueves, 5 de febrero de 2026

Pronóstico hasta las 24 horas del viernes, día 6 de febrero

(Válido fuera de pistas de esquí balizadas y abiertas)

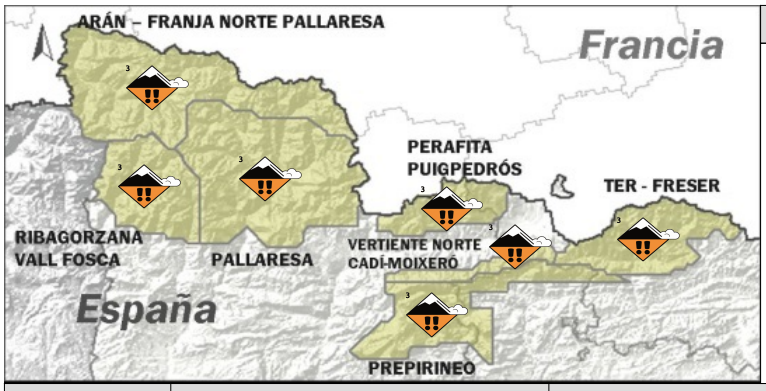

Problemas de aludes

Placas de viento

Nieve reciente

Macizo	Peligro	Problemas de aludes, cota, orientación, tamaño	Innivación observada (m)
Arán - Franja norte Pallaresa	3 / 3 2100 / 2 — Notable	Placas de viento: 2100, N O E S, 3 Nieve reciente: N O E S, 2	2026-02-05 N S Cotas bajas
Ribagorzana - Vall Fosca	3 / 3 2100 / 2 — Notable	Placas de viento: 2100, N O E S, 3 Nieve reciente: N O E S, 2	2026-02-05 N S Cotas bajas
Pallaresa	3 / 3 2100 / 2 — Notable	Placas de viento: 2100, N O E S, 3 Nieve reciente: N O E S, 2	2026-02-05 N S Cotas bajas

Boletín de información nivológica y de peligro de aludes

Pirineo Catalán

Perafita - Puigpedrós	3 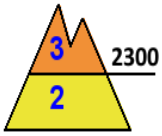 **Notable**	**Placas de viento**  **Nieve reciente** 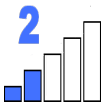	2026-02-05 Cotas bajas
Ter - Freser	3 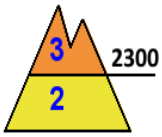 **Notable**	**Placas de viento** 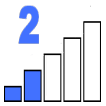	2026-02-05 Cotas bajas
Vertiente norte Cadí - Moixeró	3 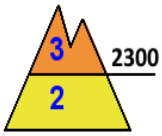 **Notable**	**Placas de viento** 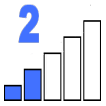	2026-02-05 Cotas bajas
Prepirineo	3 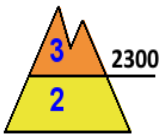 **Notable**	**Placas de viento** 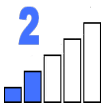	2026-02-05 Cotas bajas

Estado del manto y observaciones recientes

Continúa la circulación polar muy baja en latitud, lo que está ocasionando precipitaciones en la cordillera desde hace semanas, con cota de nieve fluctuante, aunque en la alta montaña están siendo íntegramente en forma sólida, depositando cantidades que se encuentran muy por encima de lo que puede considerarse normal a estas alturas de la temporada, incluso en máximos en numerosas zonas.

El manto es continuo desde cotas bajas, con espesores variables y fuertemente influenciados por la acción del viento, rondando los 120 a 200 cm a 2.100 metros, aunque se superan holgadamente estas cifras en ventisqueros y otras zonas de acumulación. En cotas altas la nieve se mantiene seca y muy venteada, con numerosas placas en diferentes orientaciones. Además, en zonas de umbría, todavía pueden persistir estratos débiles. En altitudes más bajas la nieve se encuentra más humedecida, debido a episodios de precipitación en forma de lluvia y un régimen térmico más suave.

Evolución del manto y peligro de aludes para el viernes, día 6

Situación de nieve reciente, y de placas de viento en cotas altas.

Continuarán las precipitaciones, más débiles en jornadas previas, y que afectarán principalmente a los macizos occidentales, pudiendo acumularse algunos cm adicionales sobre el manto previo. En consecuencia podrán darse algunas purgas de nieve reciente en las laderas suficientemente inclinadas de cualquier orientación, que en general serán de tamaño

AEMET. Se autoriza la reproducción de su contenido citando la fuente.

pequeño o mediano.

El flujo intenso del oeste y sur han formado placas en numerosas orientaciones, con preferencia en vertientes este y norte y en ocasiones alejadas de crestas y collados. Estas estructuras vienen a sumarse a las todavía existentes en otras orientaciones, correspondientes a episodios anteriores, y que aún se mantienen inestables, pudiendo fracturarse ante sobrecargas débiles, como es el paso de un esquiador, ocasionando aludes de dimensión mediana, sin descartarse que puedan llegar a ser grandes en algún caso.

Por último hacer notar que en las umbrías de alta montaña no se descarta la existencia de capas débiles persistentes, todavía activas, especialmente en zonas de manto delgado, por lo que se recomienda tomar precauciones si se va transitar por la zona.

Predicción meteorológica para el viernes, día 6

Intervalos nubosos, con nubes bajas, tendiendo a nuboso o muy nuboso al final del día, sobre todo en el sector occidental. Se esperan algunas precipitaciones débiles en los macizos occidentales, más probables de madrugada y al final del día, que podrían afectar al resto del territorio de manera más dispersa y ocasional. Cota de nieve: en torno a 1.400 metros. Temperaturas en ligero o moderado ascenso. Heladas débiles, moderadas y persistentes en cotas altas, donde podrán ser localmente fuertes. Vientos moderados de componente oeste, fuertes en cotas altas y zonas expuestas, donde podrá haber rachas muy fuertes y ventiscas.

Datos en la atmósfera libre:

Altitud de la isoterma de 0 ºC: 1.900 m
Altitud de la isoterma de -10 ºC: 3.400 m

Viento a 1500 m: W 30 km/h
Viento a 3000 m: W 60 km/h

Evolución para el sábado día 7

Nivel de peligro con pocos cambios.

Escala europea de peligro de aludes

Débil | Limitado | Notable | Fuerte | Muy Fuerte

Problemas de aludes

Nieve reciente | Placas de viento | Capas débiles persistentes | Nieve húmeda | Deslizamientos basales | Sin problema evidente

Nota1: Se recuerda que, siempre que haya nieve, la ausencia total de peligro no existe. Hay que tener presente que en circunstancias desfavorables, con aludes de tamaño 1 (alud pequeño o colada) y tamaño 2 (alud mediano), se pueden sufrir severos daños personales.

Nota2: Los BPA se elaboran en base a información meteorológica así como al estado del manto nivoso a través de sondeos puntuales. Se advierte a los usuarios de la variabilidad de esta información al extrapolarla a zonas extensas de montaña. Por ello, AEMET no se hace responsable de su uso para la toma de decisiones que conciernen a la seguridad personal, ni de los riesgos físicos o materiales de ellas derivadas.

AEMET. Se autoriza la reproducción de su contenido citando la fuente.