GOBIERNO DE ESPAÑA
VICEPRESIDENCIA TERCERA DEL GOBIERNO
MINISTERIO PARA LA TRANSICIÓN ECOLÓGICA Y EL RETO DEMOGRÁFICO

Boletín de información nivológica y de peligro de aludes

Pirineo Navarro y Aragonés

aemet Agencia Estatal de Meteorología

jueves, 5 de febrero de 2026

Pronóstico hasta las 24 horas del viernes, día 6 de febrero

(Válido fuera de pistas de esquí balizadas y abiertas)

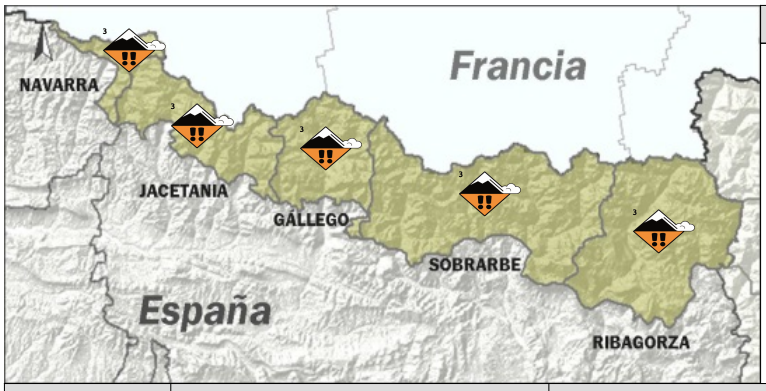

Problemas de aludes

Placas de viento

Nieve reciente

Macizo	Peligro	Problemas de aludes, cota, orientación, tamaño	Innivación observada (m)
Navarra	3 Notable	Placas de viento: 2100, N O E S, 3 Nieve reciente: N O E S, 2	2026-02-05 N S Cotas bajas
Jacetania	3 Notable	Placas de viento: 2100, N O E S, 3 Nieve reciente: N O E S, 2	2026-02-05 N S Cotas bajas
Gállego	3 Notable	Placas de viento: 2100, N O E S, 3 Nieve reciente: N O E S, 2	2026-02-05 N S Cotas bajas

AEMET. Se autoriza la reproducción de su contenido citando la fuente.

Boletín de información nivológica y de peligro de aludes

Pirineo Navarro y Aragonés

Sobrarbe	3 **Notable**	**Placas de viento** 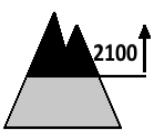  **Nieve reciente** 	2026-02-05 Cotas bajas
Ribagorza	3 **Notable**	**Placas de viento** 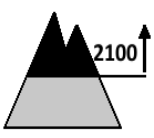  **Nieve reciente** 	2026-02-05 Cotas bajas

Estado del manto y observaciones recientes

Continúa la circulación polar muy baja en latitud, lo que está ocasionando precipitaciones desde hace semanas, con cota de nieve fluctuante, aunque en la alta montaña están siendo íntegramente en forma sólida, depositando cantidades que se encuentran, en general, muy por encima de lo que puede considerarse normal a estas alturas de la temporada.

El manto es continuo desde cotas bajas, con espesores que rondan los 140 a 180 cm en torno a 1.800 metros. Por encima de 2.100 se superan fácilmente los 200 cm, aún más en ventisqueros, hoyas u otras zonas propensas a la acumulación. En cotas altas la nieve se mantiene seca y muy venteada, con numerosas placas en diferentes orientaciones. Además, en zonas de umbría, todavía pueden persistir estratos débiles. En altitudes más bajas la nieve se encuentra más humedecida, debido a episodios de precipitación en forma de lluvia y un régimen térmico más suave.

Durante las últimas 24 horas se han registrado algunos aludes de nieve reciente, seca o húmeda, y de placa friable, que han sido de tamaño pequeño o mediano.

Evolución del manto y peligro de aludes para el viernes, día 6

Situación de nieve reciente, y de placas de viento en cotas altas.

Continuarán las precipitaciones, aunque más débiles en jornadas previas, pudiendo acumularse algunos cm adicionales sobre el espeso manto que cubre la cordillera, no esperándose cantidades significativas. En consecuencia seguirán las purgas de nieve reciente en laderas suficientemente inclinadas de cualquier orientación, generalmente de tamaño pequeño o mediano, sin descartarse que, localmente, alguno pueda adquirir mayores dimensiones.

AEMET. Se autoriza la reproducción de su contenido citando la fuente.

Asimismo, los vientos fuertes de componentes oeste y sur han formado placas en numerosas orientaciones, con preferencia en vertientes este y norte y en ocasiones alejadas de crestas y collados. Estas estructuras vienen a sumarse a las todavía existentes en otras orientaciones, correspondientes a episodios previos, y que aún se mantienen inestables, pudiendo fracturarse ante sobrecargas débiles, como es el paso de un esquiador, ocasionando aludes incluso de dimensiones grandes, suficiente como para enterrar a un grupo de personas.

Por último, conviene tener presente que en las umbrías de alta montaña pueden persistir estratos débiles en el interior del manto que siguen dando muestras de reactividad, especialmente en zonas de poco espesor, por lo que se recomienda extremar las precauciones si se va a transitar por la zona.

Predicción meteorológica para el viernes, día 6

Predominio de cielos nubosos o muy nubosos, aunque con apertura ocasional de grandes claros durante la mañana. Se esperan precipitaciones débiles o localmente moderadas, más probables a primeras y últimas horas. Cota de nieve: bajando de 1.400 ó 1.500 metros a unos 1.000 ó 1.200. Temperaturas sin cambios o en ligero ascenso, y máximas sin cambios o en ligero ascenso. Heladas débiles, moderadas y persistentes en cotas altas, donde podrán ser localmente fuertes. Vientos moderados de componentes oeste y sur, fuertes en cotas altas y zonas expuestas, donde podrá haber rachas muy fuertes y ventiscas.

Datos en la atmósfera libre:

Altitud de la isoterma de 0 ºC: 1.900 m
Altitud de la isoterma de -10 ºC: 3.400 m

Viento a 1500 m: W 30 km/h
Viento a 3000 m: W 60 km/h

Evolución para el sábado día 7

Nivel de peligro con pocos cambios.

(Información elaborada a partir de los datos recibidos de los refugios de Linza, Lizara, Panticosa, Bachimaña, Góriz, Pineta, Estós, Angel Orús, La Renclusa, Cap de Llauset y Belagua, de las estaciones de esquí de Candanchú, Astún y Formigal, de la estación de esquí de fondo de Llanos del Hospital y de Ordesa Pradera)

Escala europea de peligro de aludes

Débil Limitado Notable Fuerte Muy Fuerte

Problemas de aludes

Nieve reciente Placas de viento Capas débiles persistentes Nieve húmeda Deslizamientos basales Sin problema evidente

Nota1: Se recuerda que, siempre que haya nieve, la ausencia total de peligro no existe. Hay que tener presente que en circunstancias desfavorables, con aludes de tamaño 1 (alud pequeño o colada) y tamaño 2 (alud mediano), se pueden sufrir severos daños personales.

Nota2: Los BPA se elaboran en base a información meteorológica así como al estado del manto nivoso a través de sondeos puntuales. Se advierte a los usuarios de la variabilidad de esta información al extrapolarla a zonas extensas de montaña. Por ello, AEMET no se hace responsable de su uso para la toma de decisiones que conciernen a la seguridad personal, ni de los riesgos físicos o materiales de ellas derivadas.

AEMET. Se autoriza la reproducción de su contenido citando la fuente.