ICGC Institut Cartogràfic i Geològic de Catalunya

Servei Meteorològic de Catalunya meteo.cat

Boletín de peligro de aludes para el Pirineo de Catalunya
Del 05/02/2026 al 06/02/2026

(Válido fuera pistas de esquí y zonas no controladas)

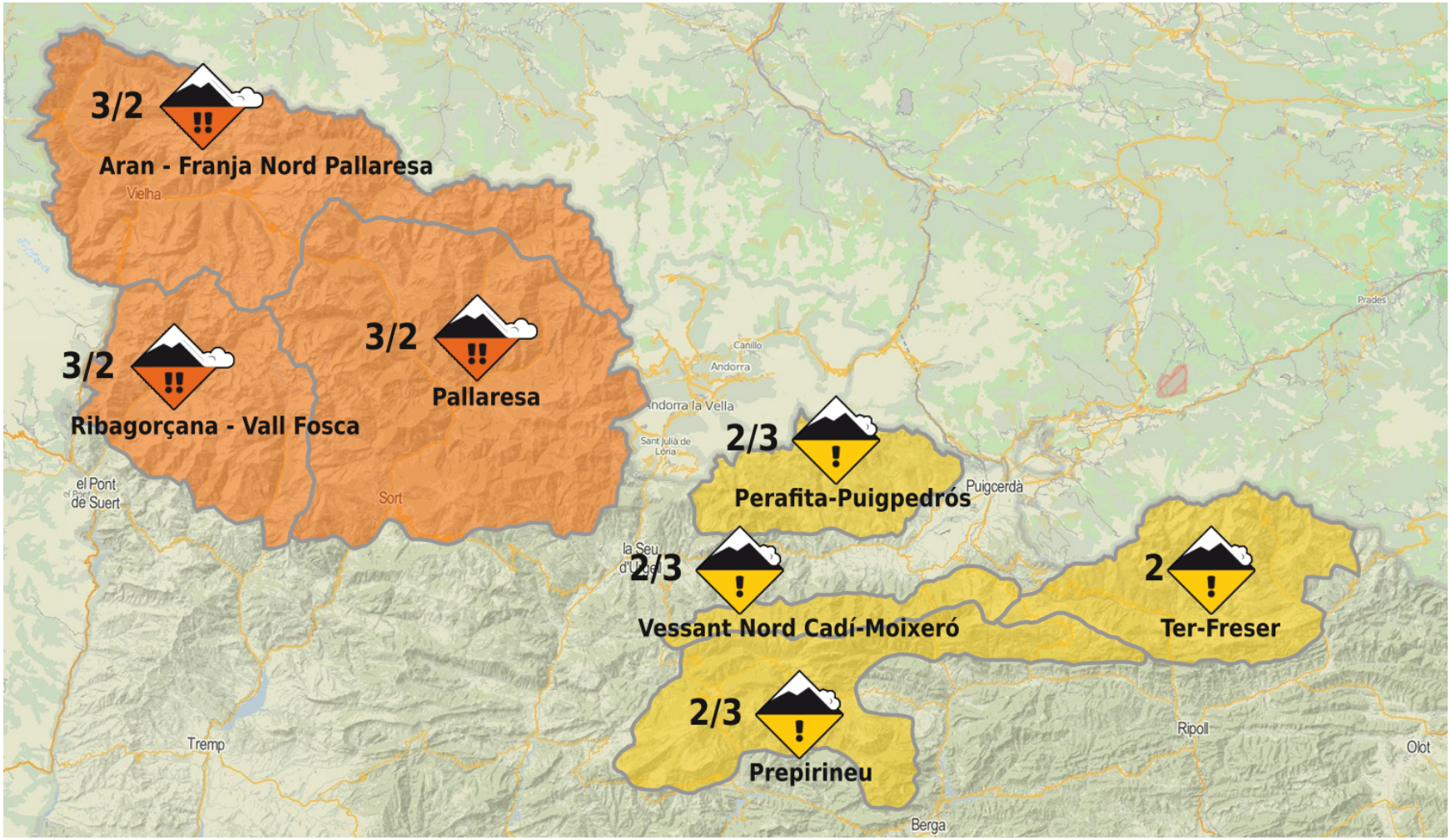

5 MUY FUERTE	4 FUERTE	3 NOTABLE	2 LIMITADO	1 DÉBIL

ICGC Institut Cartogràfic i Geològic de Catalunya

meteo.cat Servei Meteorològic de Catalunya

Boletín de peligro de aludes Aran - Franja Nord Pallaresa Del 05/02/2026 al 06/02/2026

(Válido fuera pistas de esquí y zonas no controladas)

NOTABLE (3), por encima de los 2.000 m. LIMITADO (2), en el resto.

Situación primaria

Nieve venteada

Distribución

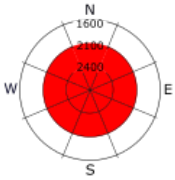

Tamaño

Origen

Tendencia

Situación secundaria

Deslizamientos basales

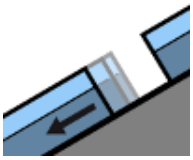

Distribución

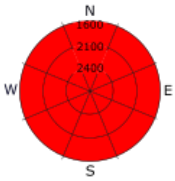

Tamaño

Origen

Tendencia

Estado del manto nivoso

Con la última nevada acompañada de fuerte viento del Sur y del Oeste se han formado nuevas placas. De cara al viernes, las nuevas acumulaciones de nieve venteada y las placas de días atrás pueden desencadenarse fácilmente, al paso de un esquiador o de un montañero y, aisladamente, pueden caer de forma natural. Las placas las encontraremos en todas las cotas, pero con mayor probabilidad, por encima del límite del bosque y en cualquier orientación, preferentemente, en Norte y Este. Los aludes generados por la rotura de estas placas podrán llegar hasta tamaño medio (con capacidad de enterrar a una persona). Con la nieve reciente pueden caer aludes, en general, de tamaño pequeño, sobre todo en laderas con fuerte inclinación. Aparte, aún podrá caer algún deslizamiento basal, en cualquier orientación y cota, siendo más probables en Sur. Los aludes, en este caso, también podrán llegar hasta tamaño medio y, localmente, de tamaño grande.

Distribución del manto nivoso

Hay nieve en el suelo a 1.000 m. El manto es esquiable por encima de unos 1.500 m. Los espesores a unos 2.200 m rondan los 100-135 cm en el norte de Arán y 130-180 cm en la Franja Nord Pallaresa y en el sur de Aran, y son superiores a los normales por estas fechas.

Tendencia para las próximas 48-72h

En los próximos días volverá a nevar, con viento en altura. Las placas de viento se mantendrán todavía reactivas. Peligro ESTACIONARIO.

El próximo boletín será emitido el día 2026-02-06

5 MUY FUERTE	4 FUERTE	3 NOTABLE	2 LIMITADO	1 DÉBIL

EAWS EUROPEAN AVALANCHE WARNING SERVICES

ICGC Institut Cartogràfic i Geològic de Catalunya

meteo.cat Servei Meteorològic de Catalunya

Boletín de peligro de aludes Ribagorçana - Vall Fosca Del 05/02/2026 al 06/02/2026

(Válido fuera pistas de esquí y zonas no controladas)

NOTABLE (3), por encima de 2.200 m.
LIMITADO (2), en el resto.

Situación primaria

Nieve venteada

Distribución

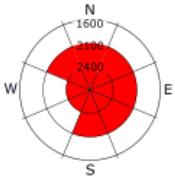

Tamaño

Origen

Tendencia

Estado del manto nivoso

La última nevada ha ido acompañada de fuerte viento del Sur y del Oeste. Con estas condiciones, el principal problema será el de las placas de viento. Los sectores más peligrosos los encontraremos por encima del nivel del bosque ya sotavento del viento del Oeste. Para el viernes, es posible actividad de aludes de placa en cualquier orientación, pero más probables en orientaciones Norte y Este. Los aludes de placa, en general, se podrán desencadenar al paso de un montañero o de un esquiador, y localmente, caerán de forma natural, llegando hasta tamaño 2 (media), aunque no se descarta alguna muy puntual de hasta tamaño 3 (grande), si acaba implicando más manto.

Distribución del manto nivoso

Hay nieve en el suelo a 1.500 m. El manto es esquiable por encima de unos 1500-1600 m. Los grosores alcanzan los 120-150 cm. Estos valores son muy superiores a los normales en la época.

Tendencia para las próximas 48-72h

En los próximos días volverá a nevar, con viento en altura. Las placas de viento se mantendrán todavía reactivas. Peligro ESTACIONARIO.

El próximo boletín será emitido el día 2026-02-06

5 MUY FUERTE	4 FUERTE	3 NOTABLE	2 LIMITADO	1 DÉBIL

EAWS EUROPEAN AVALANCHE WARNING SERVICES

ICGC Institut Cartogràfic i Geològic de Catalunya

Servei Meteorològic de Catalunya

Boletín de peligro de aludes Pallaresa
Del 05/02/2026 al 06/02/2026

(Válido fuera pistas de esquí y zonas no controladas)

NOTABLE (3), por encima de 2.200 m.
LIMITADO (2), en el resto.

Situación primaria

Nieve venteada

Distribución

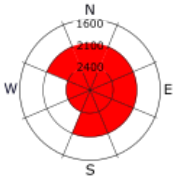

Tamaño

Origen

Tendencia

Estado del manto nivoso

La última nevada ha ído acompañada de fuerte viento del Sur y del Oeste. Con estas condiciones, el principal problema será el de las placas de viento. Los sectores más peligrosos los encontraremos por encima del nivel del bosque y a sotavento del viento del Oeste. Para el viernes, es posible actividad de aludes de placa en cualquier orientación, pero más probables en orientaciones Norte y Este. Los aludes de placa, en general, se podrán desencadenar al paso de un montañero o de un esquiador, y localmente, caerán de forma natural, llegando hasta tamaño 2 (medio), aunque no se descarta alguna muy puntual de hasta tamaño 3 (grande), si acaba implicando más manto.

Distribución del manto nivoso

Hay nieve desde 1500 m, esquiable a 1500-1600 m. Los espesores en cotas altas y medias superan los 140 cm. Estos valores son superiores a los normales para la época.

Tendencia para las próximas 48-72h

En los próximos días volverá a nevar, con viento en altura. Las placas de viento se mantendrán todavía reactivas. Peligro ESTACIONARIO.

El próximo boletín será emitido el día 2026-02-06

5 MUY FUERTE	4 FUERTE	3 NOTABLE	2 LIMITADO	1 DÉBIL

EAWS EUROPEAN AVALANCHE WARNING SERVICES

ICGC Institut Cartogràfic i Geològic de Catalunya

Servei Meteorològic de Catalunya

Boletín de peligro de aludes Perafita-Puigpedrós Del 05/02/2026 al 06/02/2026

(Válido fuera pistas de esquí y zonas no controladas)

MODERADO (2), por debajo de 2.300 m. MARCADO (3), en el resto.

Situación primaria

Nieve venteada

Distribución

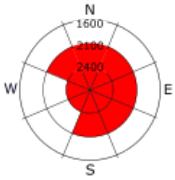

Tamaño

Origen

Tendencia

Estado del manto nivoso

El problema predominante serán las placas de viento. La última nevada, acompañada de fuerte viento del Sur y del Oeste, habrá generado nuevas placas. Los sectores más peligrosos los encontraremos por encima del nivel del bosque y a sotavento del viento del Oeste. Para el viernes, es posible actividad de aludes de placa en cualquier orientación, pero más probables en orientaciones Norte y Este. Los aludes, en general, se podrán desencadenar al paso de un montañero o de un esquiador, y localmente, caerán de forma natural, llegando hasta tamaño 2 (medio), con capacidad de enterrar a una persona.

Distribución del manto nivoso

Hay nieve en el suelo por encima de 1.300 m. Sin embargo, el manto es esquiable por encima de 1.500-1.600 m. Los grosores alcanzan los 120-140 cm a 2.200 m. Son grosores muy por encima de los habituales por la época.

Tendencia para las próximas 48-72h

En los próximos días volverá a nevar, con viento en altura. Las placas de viento se mantendrán todavía reactivas. Peligro ESTACIONARIO.

El próximo boletín será emitido el día 2026-02-06

5 MUY FUERTE	4 FUERTE	3 NOTABLE	2 LIMITADO	1 DÉBIL

EAWS EUROPEAN AVALANCHE WARNING SERVICES

ICGC Institut Cartogràfic i Geològic de Catalunya

Servei Meteorològic de Catalunya

Boletín de peligro de aludes
Vessant Nord Cadí-Moixeró
Del 05/02/2026 al 06/02/2026

(Válido fuera pistas de esquí y zonas no controladas)

LIMITADO (2) por debajo de 2.200 m. NOTABLE (3), en el resto.

Situación primaria

Nieve venteada

Distribución

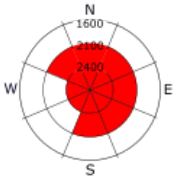

Tamaño

Origen

Tendencia

Estado del manto nivoso

El manto está formado por nieve venteada y grano fino que, internamente, se intercala con costras (que aparecen más duras en el Cadí). Los últimos chubascos de nieve han ido acompañados de viento, por tanto, se prevé que se formarán nuevas placas, sobre todo en cotas altas, como en la parte alta de las canales y bajo collados y crestas, en orientaciones N y E. Las placas nuevas serán frágiles y podrán romper fácilmente al paso de una persona, generando aludes en general de tamaño pequeño o medio (con capacidad de enterrar a una persona). Localmente, algún alud podría desencadenarse de forma natural.

Distribución del manto nivoso

Hay nieve desde 1.100 m. Norte y desde 1.400 m. Sur, esquiable por encima de unos 1.600 m. Los grosores están alrededor de 150 cm a 2.200 m. Estos valores son muy excedentarios para la época del año.

Tendencia para las próximas 48-72h

Con el descenso térmico y los nuevos chubascos previstos las placas de viento de reciente formación se mantendrán reactivas. Peligro ESTACIONARIO.

El próximo boletín será emitido el día 2026-02-06

5 MUY FUERTE	4 FUERTE	3 NOTABLE	2 LIMITADO	1 DÉBIL

EAWS EUROPEAN AVALANCHE WARNING SERVICES

ICGC Institut Cartogràfic i Geològic de Catalunya

Servei Meteorològic de Catalunya

Boletín de peligro de aludes Prepirineu
Del 05/02/2026 al 06/02/2026

(Válido fuera pistas de esquí y zonas no controladas)

LIMITADO (2) por debajo de 2.200 m. NOTABLE (3), en el resto.

Situación primaria

Nieve venteada

Distribución

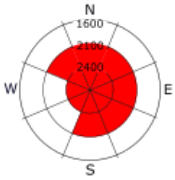

Tamaño

Origen

Tendencia

Estado del manto nivoso

El manto está formado por nieve venteada en sus capas más superficiales y por debajo encontramos un poco de nieve granulada, formas mixtas y grano fino, con la alternancia de costras. La última nevada ha ido acompañada de viento, por tanto, el problema que se prevé para el viernes será el de las placas de viento. Estas placas de nueva formación se podrán encontrar en cotas altas, como en lo alto de las canales y bajo collados y cordales, sobre todo en orientaciones N y E. Las placas nuevas serán frágiles y podrán romper fácilmente al paso de una persona, generando aludes en general de tamaño 1 (pequeño) y tamaño 2 (medio), con capacidad de enterrar a una persona. Localmente, algún alud podría desencadenarse de forma natural.

Distribución del manto nivoso

Hay nieve desde 1400-1500 m. El manto es esquiable a partir de 1600 m. Los grosores están alrededor de 100-120 cm a unos 2.200 m y son superiores a los habituales.

Tendencia para las próximas 48-72h

Con el descenso térmico y los nuevos chubascos previstos las placas de viento de reciente formación se mantendrán reactivas. Peligro ESTACIONARIO.

El próximo boletín será emitido el día 2026-02-06

5 MUY FUERTE	4 FUERTE	3 NOTABLE	2 LIMITADO	1 DÉBIL

EAWS EUROPEAN AVALANCHE WARNING SERVICES

ICGC Institut Cartogràfic i Geològic de Catalunya

Servei Meteorològic de Catalunya meteo.cat

Boletín de peligro de aludes Ter-Freser
Del 05/02/2026 al 06/02/2026

(Válido fuera pistas de esquí y zonas no controladas)

LIMITADO (2).

Situación primaria

Nieve venteada

Distribución

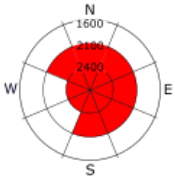

Tamaño

Origen

Tendencia

Estado del manto nivoso

El problema predominante será el de las placas de viento. La última nevada, acompañada de fuerte viento del Sur y del Oeste, habrá generado nuevas placas, frágiles. Los sectores más peligrosos los encontraremos por encima del nivel del bosque y a sotavento del viento del Oeste. Para el viernes, es posible actividad de aludes de placa en cualquier orientación, pero más probables en orientaciones Norte y Este. Los aludes, en general, se podrán desencadenar al paso de un montañero o de un esquiador y, localmente, caerán de manera natural, llegando hasta tamaño medio (con capacidad de enterrar a una persona), si involucran las placas viejas.

Distribución del manto nivoso

El manto nivoso presenta grosores muy excedentarios para la época del año. En lugares no afectados por el viento, los espesores oscilan entre 100-140 cm a unos 2.000 m, siendo esquiable a partir de unos 1.500 m.

Tendencia para las próximas 48-72h

En los próximos días volverá a nevar, con viento en altura. Las placas de viento se mantendrán todavía reactivas. Peligro ESTACIONARIO.

El próximo boletín será emitido el día 2026-02-06

5 MUY FUERTE	4 FUERTE	3 NOTABLE	2 LIMITADO	1 DÉBIL

EAWS EUROPEAN AVALANCHE WARNING SERVICES