MINISTERO DELLA DIFESA

meteomont
Servizio Nazionale di previsione neve e valanghe

EAWS EUROPEAN AVALANCHE WARNING SERVICES

CARABINIERI

AERONAUTICA MILITARE SERVIZIO METEOROLOGICO

ALPI CARNICHE OCCIDENTALI

Bollettino Valanghe N. 335/2026 del 04/02/2026 ore 14.00
Validità 48 ore prossima emissione 05/02/2026

A cura del Servizio METEOMONT dell'ARMA dei CARABINIERI
In collaborazione con Servizio Meteorologico dell'Aeronautica militare

SITUAZIONE alle 14:00 del 04/02/2026

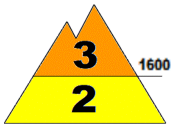

SITUAZIONE TIPO: neve a debole coesione e vento.



SITUAZIONE TIPO: neve a debole coesione e vento.

Quota neve (mslm)	Nord	Sud
	600 - 700	700

Altezza Neve (cm)	Neve al suolo	Neve Fresca	Quota (mslm)
	58	04	1760
	63	10	1425

VALANGHE OSSERVATE: -.

PREVISIONI 05/02/2026

GRADO DI PERICOLO: FORTE 4

SITUAZIONE TIPO: neve a debole coesione e vento.



SITUAZIONE TIPO: neve a debole coesione e vento.

MANTO NEVOSO: La stabilità del manto nevoso è molto scarsa su molti punti (aree) per tutte le esposizioni al di sopra di 1600 mslm, possibili valanghe di dimensioni grandi.
La stabilità del manto nevoso è molto scarsa su alcuni punti (aree) per tutte le esposizioni al di sotto di 1600 mslm, possibili valanghe di dimensioni medie.

AVVERTENZE

Sono assolutamente da evitare le attività escursionistiche al di fuori dalle piste battute e segnalate.

SCALA EUROPEA DEL GRADO DI PERICOLO VALANGHE

LEGENDA PROBLEMA

Bollettino realizzato su scala sinottica-regionale (standard EAWS). La sua valutazione non può escludere in alcun modo la necessità di una seria e capace valutazione locale del pericolo (singolo pendio) che può essere anche sensibilmente diverso. Le previsioni meteorologiche sono relative all'orario UTC (per l'Italia +1 in inverno e +2 in estate).

MINISTERO DELLA DIFESA

meteomont
Servizio Nazionale di previsione neve e valanghe

EAWS EUROPEAN AVALANCHE WARNING SERVICES

CARABINIERI

ALPI CARNICHE OCCIDENTALI

PREVISIONE METEO

Quota		05/02/2026 h6:00	05/02/2026 h12:00	05/02/2026 h18:00
1000	Venti	01 Nodi da N-Est	01 Nodi da N-Est	01 Nodi da Sud
	Temperature	-01 °C	+00 °C	+00 °C
	Temp.percepita	-1 °C	0 °C	0 °C
2000	Venti	03 Nodi da N-Est	01 Nodi da Est	02 Nodi da S-Ovest
	Temperature	-02 °C	-02 °C	-02 °C
	Temp.percepita	-4 °C	-2 °C	-2 °C
3000	Venti	07 Nodi da S-Est	03 Nodi da S-Est	04 Nodi da Ovest
	Temperature	-07 °C	-07 °C	-07 °C
	Temp.percepita	-13 °C	-10 °C	-11 °C
Zero termico		1500-1700 m.	1600-1800 m.	1600-1800 m.
Fenomeno				
Stato del cielo				

LEGENDA FENOMENI

Assenza Fenomeni · Nebbia · Foschia · Pioggia debole · Pioggia moderata · Pioggia forte · Temporali

Nevicata debole · Nevicata moderata · Nevicata forte

STATO DEL CIELO

Sereno · Poco nuvoloso · Nuvoloso · Molto nuvoloso · Coperto

Parametri meteonivometrici registrati presso i campi di rilevamento il 04/02/2026.

Località	Comune	Quota (m.s.l.m.)	Altezza neve (cm)	Neve caduta nelle 24 ore (cm)	Temp. Min (°C)	Temp. Max (°C)	Condizioni del tempo
SAURIS DI SOPRA	Sauris (UD)	1425	63	10	-3	-1	Nevicata debole continua

(*) Rilievi fuori campo

L'INFORMAZIONE E' PREVENZIONE - LEGGI L'ATTUALE GRADO DI PERICOLO VALANGHE!

IL CAPO DEL CENTRO NAZIONALE METEOMONT
(Ten. Col. RFI Emanuela Gini)
FIRMA AUTOGRAFA OMESSA AI SENSI
DELL'ART.3 DEL D.LGS N.39/1993

Bollettino realizzato su scala sinottica-regionale (standard EAWS). La sua valutazione non può escludere in alcun modo la necessità di una seria e capace valutazione locale del pericolo (singolo pendio) che può essere anche sensibilmente diverso. Le previsioni meteorologiche sono relative all'orario UTC (per l'Italia +1 in inverno e +2 in estate).