MINISTERO DELLA DIFESA

meteomont Servizio Nazionale di previsione neve e valanghe

EAWS EUROPEAN AVALANCHE WARNING SERVICES

CARABINIERI

In collaborazione con: arpav

DOLOMITI MERIDIONALI

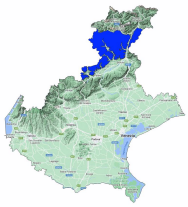

Bollettino Valanghe N. 338/2026 del 05/02/2026 ore 14.00
Validità 48 ore prossima emissione 06/02/2026

A cura del Servizio METEOMONT dell'ARMA dei CARABINIERI
In collaborazione con Servizio Meteorologico dell'Aeronautica militare

SITUAZIONE alle 14:00 del 05/02/2026

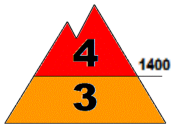

SITUAZIONE TIPO: neve a debole coesione e vento.



SITUAZIONE TIPO: pioggia su neve.

Quota neve (mslm)	Nord	Sud
	700	700

Altezza Neve (cm)	Neve al suolo	Neve Fresca	Quota (mslm)
	78	23	1820
	76	25	1365

VALANGHE OSSERVATE: -.

PREVISIONI 06/02/2026

GRADO DI PERICOLO: FORTE 4

SITUAZIONE TIPO: nessuna situazione tipo evidente.



SITUAZIONE TIPO: pioggia su neve.

MANTO NEVOSO: La stabilità del manto nevoso è scarsa su molti punti (aree) per tutte le esposizioni al di sopra di 1400 mslm, possibili valanghe di dimensioni grandi.
La stabilità del manto nevoso è scarsa su molti punti (aree) per tutte le esposizioni al di sotto di 1400 mslm, possibili valanghe di dimensioni medie.

AVVERTENZE

In considerazione dei recenti apporti di neve fresca, è richiesta un'ottima valutazione locale della stabilità ed individuazione dell'itinerario.

SCALA EUROPEA DEL GRADO DI PERICOLO VALANGHE

LEGENDA PROBLEMA

Bollettino realizzato su scala sinottica-regionale (standard EAWS). La sua valutazione non può escludere in alcun modo la necessità di una seria e capace valutazione locale del pericolo (singolo pendio) che può essere anche sensibilmente diverso. Le previsioni meteorologiche sono relative all'orario UTC (per l'Italia +1 in inverno e +2 in estate).

MINISTERO DELLA DIFESA

meteomont
Servizio Nazionale di previsione neve e valanghe

EAWS EUROPEAN AVALANCHE WARNING SERVICES

CARABINIERI

In collaborazione con: arpav

DOLOMITI MERIDIONALI

PREVISIONE METEO

Quota		06/02/2026 h6:00	06/02/2026 h12:00	06/02/2026 h18:00
1000	Venti	00 Calma	00 Calma	00 Calma
	Temperature	+01 °C	+02 °C	+05 °C
	Temp.percepita	1 °C	2 °C	5 °C
2000	Venti	02 Nodi da S-Ovest	02 nodi da N-Ovest	03 Nodi da Nord
	Temperature	-03 °C	-02 °C	+00 °C
	Temp.percepita	-3 °C	-2 °C	-2 °C
3000	Venti	06 Nodi da S-Ovest	04 Nodi da Nord	08 Nodi da N-Est
	Temperature	-07 °C	-07 °C	-07 °C
	Temp.percepita	-12 °C	-11 °C	-13 °C
Zero termico		1400-1600 m.	1600-1800 m.	1900-2100 m.
Fenomeno		—	—	
Stato del cielo				

LEGENDA FENOMENI

Assenza Fenomeni — Nebbia — Foschia — Pioggia debole — Pioggia moderata — Pioggia forte — Temporali

Nevicata debole — Nevicata moderata — Nevicata forte

STATO DEL CIELO

Sereno — Poco nuvoloso — Nuvoloso — Molto nuvoloso — Coperto

Parametri meteonivometrici registrati presso i campi di rilevamento il 05/02/2026.

Località	Comune	Quota (m.s.l.m.)	Altezza neve (cm)	Neve caduta nelle 24 ore (cm)	Temp. Min (°C)	Temp. Max (°C)	Condizioni del tempo
LE BUSE	Falcade (BL)	1820	78	23	-4	-1	Nevicata debole continua
LARESEI *	Falcade (BL)	2250	77	25	N.P.	N.P.	Assenza di precipitazioni

(*) Rilievi fuori campo

L'INFORMAZIONE E' PREVENZIONE - LEGGI L'ATTUALE GRADO DI PERICOLO VALANGHE!

IL CAPO DEL CENTRO NAZIONALE METEOMONT
(Ten. Col. RFI Emanuela Gini)
FIRMA AUTOGRAFA OMESSA AI SENSI
DELL'ART.3 DEL D.LGS N.39/1993

Bollettino realizzato su scala sinottica-regionale (standard EAWS). La sua valutazione non può escludere in alcun modo la necessità di una seria e capace valutazione locale del pericolo (singolo pendio) che può essere anche sensibilmente diverso. Le previsioni meteorologiche sono relative all'orario UTC (per l'Italia +1 in inverno e +2 in estate).