MINISTERO DELLA DIFESA

meteomont
Servizio Nazionale di previsione neve e valanghe

EAWS EUROPEAN AVALANCHE WARNING SERVICES

CARABINIERI

AERONAUTICA MILITARE SERVIZIO METEOROLOGICO

ALPI RETICHE

Bollettino Valanghe N. 337/2026 del 04/02/2026 ore 14.00
Validità 48 ore prossima emissione 05/02/2026

A cura del Servizio METEOMONT dell'ARMA dei CARABINIERI
In collaborazione con Servizio Meteorologico dell'Aeronautica militare

SITUAZIONE alle 14:00 del 04/02/2026

SITUAZIONE TIPO: brina di superficie sepolta.

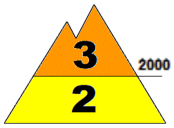



SITUAZIONE TIPO: brina di superficie sepolta.

Quota neve (mslm)	Nord	Sud
	700	700 - 1000

Altezza Neve (cm)	Neve al suolo	Neve Fresca	Quota (mslm)
	60-100	1	2500
	35-60	2-6	1600

VALANGHE OSSERVATE: Nessuna valanga.

PREVISIONI 05/02/2026

GRADO DI PERICOLO: MARCATO 3

SITUAZIONE TIPO: brina di superficie sepolta.

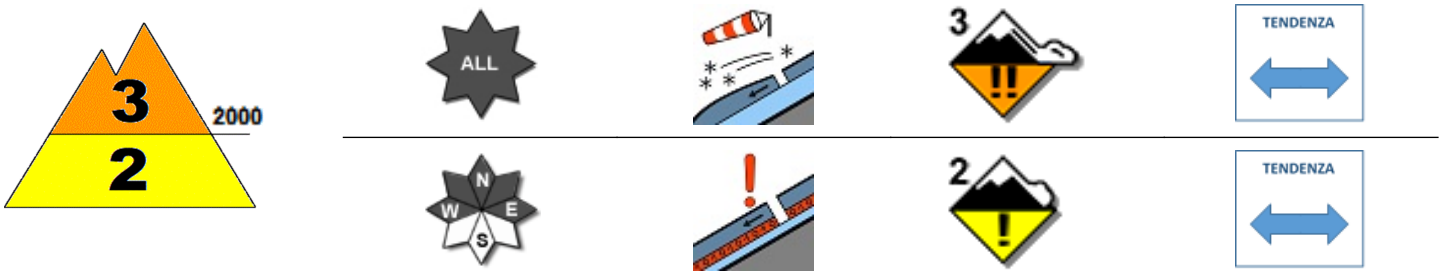

SITUAZIONE TIPO: brina di superficie sepolta.

MANTO NEVOSO: La stabilità del manto nevoso è molto scarsa su molti punti (aree) per tutte le esposizioni al di sopra di 2000 mslm, possibili valanghe di dimensioni medie.
La stabilità del manto nevoso è scarsa su molti punti (aree) per versanti da ovest a est al di sotto di 2000 mslm, possibili valanghe di dimensioni piccole.

AVVERTENZE

Attenzione alla presenza di accumuli eolici di difficile individuazione.

SCALA EUROPEA DEL GRADO DI PERICOLO VALANGHE

LEGENDA PROBLEMA

Bollettino realizzato su scala sinottica-regionale (standard EAWS). La sua valutazione non può escludere in alcun modo la necessità di una seria e capace valutazione locale del pericolo (singolo pendio) che può essere anche sensibilmente diverso. Le previsioni meteorologiche sono relative all'orario UTC (per l'Italia +1 in inverno e +2 in estate).

MINISTERO DELLA DIFESA

meteomont
Servizio Nazionale di previsione neve e valanghe

EAWS EUROPEAN AVALANCHE WARNING SERVICES

CARABINIERI

ALPI RETICHE

PREVISIONE METEO

Quota		05/02/2026 h6:00	05/02/2026 h12:00	05/02/2026 h18:00
1000	Venti	01 Nodi da Ovest	01 Nodi da S-Ovest	01 Nodi da Nord
	Temperature	-01 °C	-01 °C	-01 °C
	Temp.percepita	-1 °C	-1 °C	-1 °C
2000	Venti	01 Nodi da Ovest	01 Nodi da S-Ovest	01 Nodi da Nord
	Temperature	-01 °C	-01 °C	-01 °C
	Temp.percepita	-1 °C	-1 °C	-1 °C
3000	Venti	02 Nodi da Nord	00 Calma	03 Nodi da Ovest
	Temperature	-07 °C	-07 °C	-06 °C
	Temp.percepita	-7 °C	-7 °C	-9 °C
Zero termico		1700-1900 m.	1700-1900 m.	1700-1900 m.
Fenomeno		—	—	—
Stato del cielo				

LEGENDA FENOMENI

— Assenza Fenomeni · Nebbia · Foschia · Pioggia debole · Pioggia moderata · Pioggia forte · Temporali

Nevicata debole · Nevicata moderata · Nevicata forte

STATO DEL CIELO

Sereno · Poco nuvoloso · Nuvoloso · Molto nuvoloso · Coperto

Parametri meteonivometrici registrati presso i campi di rilevamento il 04/02/2026.

Località	Comune	Quota (m.s.l.m.)	Altezza neve (cm)	Neve caduta nelle 24 ore (cm)	Temp. Min (°C)	Temp. Max (°C)	Condizioni del tempo
BORMIO2000-LECCIONA	Valdisotto (SO)	2050	64	1	-6	-1	Assenza di precipitazioni
DOSSO DEL VALLONE	Valfurva (SO)	2582	58	0	-6	-3	Nevicata debole intermittente
SANTA APOLLONIA	Vezza d'Oglio (BS)	1599	35	4	N.P.	N.P.	Precipitazioni all'orizzonte (pioggia, neve, grandine, temporali) ma non sulla stazione
ALPE PALU'	Chiesa in Valmalenco (SO)	2010	75	1	-6	+0	Nevicata debole intermittente
PREDA	Edolo (BS)	1580	40	2	-2	0	Assenza di precipitazioni
COLONIA VIGILI	Ponte di Legno (BS)	1640	59	6	-9	+1	Nevicata moderata

(*) Rilievi fuori campo

L'INFORMAZIONE E' PREVENZIONE - LEGGI L'ATTUALE GRADO DI PERICOLO VALANGHE!

IL CAPO DEL CENTRO NAZIONALE METEOMONT
(Ten. Col. RFI Emanuela Gini)
FIRMA AUTOGRAFA OMESSA AI SENSI
DELL'ART.3 DEL D.LGS N.39/1993

Bollettino realizzato su scala sinottica-regionale (standard EAWS). La sua valutazione non può escludere in alcun modo la necessità di una seria e capace valutazione locale del pericolo (singolo pendio) che può essere anche sensibilmente diverso. Le previsioni meteorologiche sono relative all'orario UTC (per l'Italia +1 in inverno e +2 in estate).