MINISTERO DELLA DIFESA

meteomont
Servizio Nazionale di previsione neve e valanghe

EAWS EUROPEAN AVALANCHE WARNING SERVICES

CARABINIERI

## ALPI RETICHE

Bollettino Valanghe N. 338/2026 del 05/02/2026 ore 14.00
Validità 48 ore prossima emissione 06/02/2026

**A cura del Servizio METEOMONT dell'ARMA dei CARABINIERI**
**In collaborazione con Servizio Meteorologico dell'Aeronautica militare**

## SITUAZIONE alle 14:00 del 05/02/2026

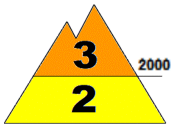


**SITUAZIONE TIPO: brina di superficie sepolta.**




**SITUAZIONE TIPO: brina di superficie sepolta.**

| Quota neve (mslm) | Nord | Sud |
|---|---|---|
| | 700 - 900 | 700 - 1000 |

| Altezza Neve (cm) | Neve al suolo | Neve Fresca | Quota (mslm) |
|---|---|---|---|
| | 58 | 12 | 2150 |
| | 63 | 5 | 1640 |

**VALANGHE OSSERVATE: Nessuna valanga.**

## PREVISIONI 06/02/2026

# GRADO DI PERICOLO: MARCATO 3

## SITUAZIONE TIPO: brina di superficie sepolta.

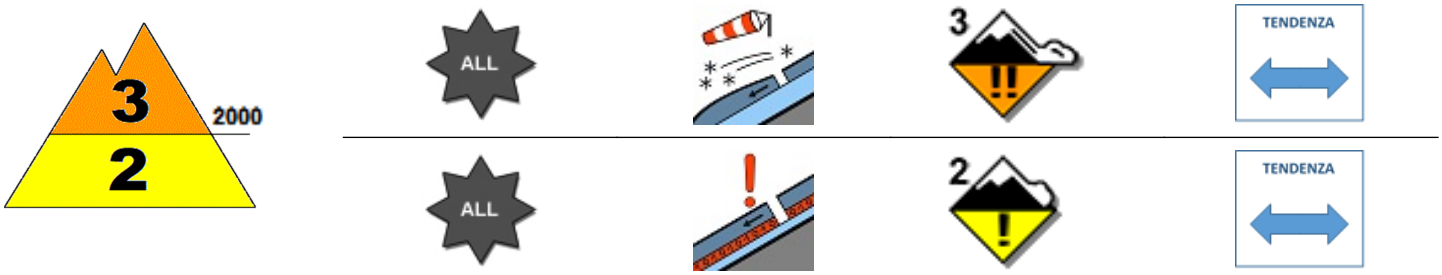


## SITUAZIONE TIPO: brina di superficie sepolta.

**MANTO NEVOSO: La stabilità del manto nevoso è molto scarsa su molti punti (aree) per tutte le esposizioni al di sopra di 2000 mslm, possibili valanghe di dimensioni medie.**
**La stabilità del manto nevoso è scarsa su molti punti (aree) per tutte le esposizioni al di sotto di 2000 mslm, possibili valanghe di dimensioni piccole.**

## AVVERTENZE

In considerazione dei recenti apporti di neve fresca, è richiesta una buona valutazione locale della stabilità ed individuazione dell'itinerario.

## SCALA EUROPEA DEL GRADO DI PERICOLO VALANGHE

## LEGENDA PROBLEMA

**Bollettino realizzato su scala sinottica-regionale (standard EAWS). La sua valutazione non può escludere in alcun modo la necessità di una seria e capace valutazione locale del pericolo (singolo pendio) che può essere anche sensibilmente diverso. Le previsioni meteorologiche sono relative all'orario UTC (per l'Italia +1 in inverno e +2 in estate).**

MINISTERO DELLA DIFESA

meteomont
Servizio Nazionale di previsione neve e valanghe

EAWS EUROPEAN AVALANCHE WARNING SERVICES

CARABINIERI

# ALPI RETICHE

## PREVISIONE METEO

| Quota | | 06/02/2026 h6:00 | 06/02/2026 h12:00 | 06/02/2026 h18:00 |
|---|---|---|---|---|
| 1000 | Venti | 01 nodi da N-Ovest | 01 Nodi da Est | 00 Calma |
| | Temperature | -03 °C | -03 °C | +01 °C |
| | Temp.percepita | -3 °C | -3 °C | 1 °C |
| 2000 | Venti | 01 nodi da N-Ovest | 01 Nodi da Est | 00 Calma |
| | Temperature | -03 °C | -03 °C | +01 °C |
| | Temp.percepita | -3 °C | -3 °C | 1 °C |
| 3000 | Venti | 02 Nodi da Ovest | 06 nodi da N-Ovest | 03 Nodi da Nord |
| | Temperature | -08 °C | -07 °C | -07 °C |
| | Temp.percepita | -8 °C | -12 °C | -10 °C |
| Zero termico | | 1200-1400 m. | 1300-1500 m. | 1800-2000 m. |
| Fenomeno | | | — | — |
| Stato del cielo | | | | |

## LEGENDA FENOMENI

— Assenza Fenomeni · Nebbia · Foschia · Pioggia debole · Pioggia moderata · Pioggia forte · Temporali

Nevicata debole · Nevicata moderata · Nevicata forte

## STATO DEL CIELO

Sereno · Poco nuvoloso · Nuvoloso · Molto nuvoloso · Coperto

## Parametri meteonivometrici registrati presso i campi di rilevamento il 05/02/2026.

| Località | Comune | Quota (m.s.l.m.) | Altezza neve (cm) | Neve caduta nelle 24 ore (cm) | Temp. Min (°C) | Temp. Max (°C) | Condizioni del tempo |
|---|---|---|---|---|---|---|---|
| SPONDA | Livigno (SO) | 2150 | 58 | 12 | -7 | +2 | Assenza di precipitazioni |
| BORMIO2000-LECCIONA | Valdisotto (SO) | 2050 | 66 | 2 | -6 | 0 | Assenza di precipitazioni |
| VALAR | Valdidentro (SO) | 1930 | 64 | 2 | -8 | -1 | Assenza di precipitazioni |
| DOSSO DEL VALLONE | Valfurva (SO) | 2582 | 58 | 0 | -5 | -3 | Assenza di precipitazioni |
| ALPE PALU' | Chiesa in Valmalenco (SO) | 2010 | 80 | 9 | -5 | -2 | Assenza di precipitazioni |
| PREDA | Edolo (BS) | 1580 | 41 | 2 | -2 | -2 | Assenza di precipitazioni |
| COLONIA VIGILI | Ponte di Legno (BS) | 1640 | 63 | 5 | -3 | +1 | Assenza di precipitazioni |
| PARÈ DI LIVIGNO * | Livigno (SO) | 2293 | 59 | 0 | N.P. | N.P. | Assenza di precipitazioni |
| SASSO ALTO * | Lanzada (SO) | 2343 | 93 | 12 | N.P. | N.P. | Assenza di precipitazioni |

(*) Rilievi fuori campo

**L'INFORMAZIONE E' PREVENZIONE - LEGGI L'ATTUALE GRADO DI PERICOLO VALANGHE!**

IL CAPO DEL CENTRO NAZIONALE METEOMONT
(Ten. Col. RFI Emanuela Gini)
FIRMA AUTOGRAFA OMESSA AI SENSI
DELL'ART.3 DEL D.LGS N.39/1993

Bollettino realizzato su scala sinottica-regionale (standard EAWS). La sua valutazione non può escludere in alcun modo la necessità di una seria e capace valutazione locale del pericolo (singolo pendio) che può essere anche sensibilmente diverso. Le previsioni meteorologiche sono relative all'orario UTC (per l'Italia +1 in inverno e +2 in estate).