MINISTERO DELLA DIFESA

meteomont
Servizio Nazionale di previsione neve e valanghe

EAWS EUROPEAN AVALANCHE WARNING SERVICES

CARABINIERI

AERONAUTICA MILITARE SERVIZIO METEOROLOGICO

ALPI OROBICHE

Bollettino Valanghe N. 336/2026 del 05/02/2026 ore 14.00
Validità 48 ore prossima emissione 06/02/2026

A cura del Servizio METEOMONT dell'ARMA dei CARABINIERI
In collaborazione con Servizio Meteorologico dell'Aeronautica militare

SITUAZIONE alle 14:00 del 05/02/2026

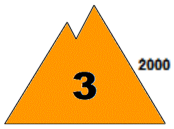

SITUAZIONE TIPO: brina di superficie sepolta.



SITUAZIONE TIPO: brina di superficie sepolta.

Quota neve (mslm)	Nord	Sud
	800-900	800-900

Altezza Neve (cm)	Neve al suolo	Neve Fresca	Quota (mslm)
	135	20	2080
	75	14	1635

VALANGHE OSSERVATE: Nessuna valanga.

PREVISIONI 06/02/2026

GRADO DI PERICOLO: MARCATO 3

SITUAZIONE TIPO: brina di superficie sepolta.

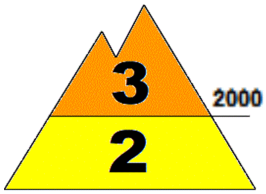

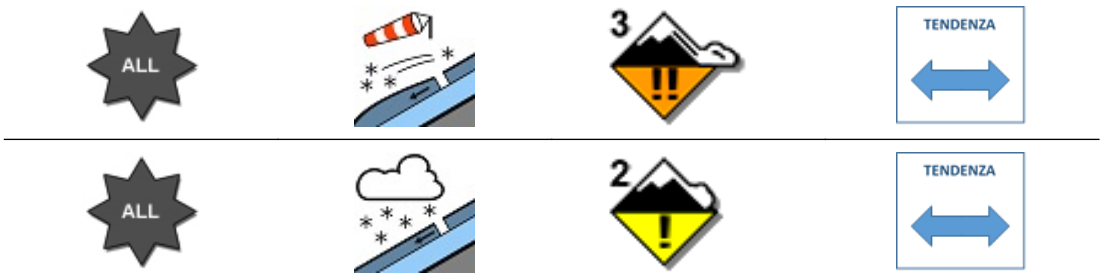

SITUAZIONE TIPO: brina di superficie sepolta.

MANTO NEVOSO: La stabilità del manto nevoso è molto scarsa su alcuni punti (aree) per tutte le esposizioni al di sopra di 2000 mslm, possibili valanghe di dimensioni medie.
La stabilità del manto nevoso è scarsa su alcuni punti (aree) per tutte le esposizioni al di sotto di 2000 mslm, possibili valanghe di dimensioni medie.

AVVERTENZE

In considerazione dei recenti apporti di neve fresca, è richiesta un'ottima valutazione locale della stabilità ed individuazione dell'itinerario.

SCALA EUROPEA DEL GRADO DI PERICOLO VALANGHE

LEGENDA PROBLEMA

Bollettino realizzato su scala sinottica-regionale (standard EAWS). La sua valutazione non può escludere in alcun modo la necessità di una seria e capace valutazione locale del pericolo (singolo pendio) che può essere anche sensibilmente diverso. Le previsioni meteorologiche sono relative all'orario UTC (per l'Italia +1 in inverno e +2 in estate).

MINISTERO DELLA DIFESA

meteomont
Servizio Nazionale di previsione neve e valanghe

EAWS EUROPEAN AVALANCHE WARNING SERVICES

CARABINIERI

ALPI OROBICHE

PREVISIONE METEO

Quota		06/02/2026 h6:00	06/02/2026 h12:00	06/02/2026 h18:00
1000	Venti	02 Nodi da Nord	00 Calma	02 Nodi da Nord
	Temperature	-03 °C	+00 °C	+01 °C
	Temp.percepita	-3 °C	0 °C	1 °C
2000	Venti	01 Nodi da N-Est	02 nodi da N-Ovest	02 Nodi da Nord
	Temperature	-02 °C	-01 °C	+01 °C
	Temp.percepita	-2 °C	-1 °C	1 °C
3000	Venti	04 nodi da Ovest	08 Nodi da Nord	04 Nodi da Nord
	Temperature	-07 °C	-07 °C	-07 °C
	Temp.percepita	-11 °C	-13 °C	-11 °C
Zero termico		1200-1400 m.	1700-1900 m.	1800-2000 m.
Fenomeno		—	—	—
Stato del cielo				

LEGENDA FENOMENI

— Assenza Fenomeni · Nebbia · Foschia · Pioggia debole · Pioggia moderata · Pioggia forte · Temporali

Nevicata debole · Nevicata moderata · Nevicata forte

STATO DEL CIELO

Sereno · Poco nuvoloso · Nuvoloso · Molto nuvoloso · Coperto

Parametri meteonivometrici registrati presso i campi di rilevamento il 05/02/2026.

Località	Comune	Quota (m.s.l.m.)	Altezza neve (cm)	Neve caduta nelle 24 ore (cm)	Temp. Min (°C)	Temp. Max (°C)	Condizioni del tempo
VODALA	Gromo (BG)	1635	75	14	-2	0	Assenza di precipitazioni
QUARTA BAITA	Foppolo (BG)	1760	73	8	-5	0	Assenza di precipitazioni
CIMA BIANCA	Colere (BG)	2080	135	20	-3	+1	Assenza di precipitazioni

(*) Rilievi fuori campo

L'INFORMAZIONE E' PREVENZIONE - LEGGI L'ATTUALE GRADO DI PERICOLO VALANGHE!

IL CAPO DEL CENTRO NAZIONALE METEOMONT
(Ten. Col. RFI Emanuela Gini)
FIRMA AUTOGRAFA OMESSA AI SENSI
DELL'ART.3 DEL D.LGS N.39/1993

Bollettino realizzato su scala sinottica-regionale (standard EAWS). La sua valutazione non può escludere in alcun modo la necessità di una seria e capace valutazione locale del pericolo (singolo pendio) che può essere anche sensibilmente diverso. Le previsioni meteorologiche sono relative all'orario UTC (per l'Italia +1 in inverno e +2 in estate).