MINISTERO DELLA DIFESA

meteomont Servizio Nazionale di previsione neve e valanghe

EAWS EUROPEAN AVALANCHE WARNING SERVICES

CARABINIERI

AERONAUTICA MILITARE SERVIZIO METEOROLOGICO

PREALPI LOMBARDE

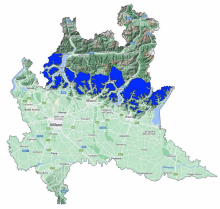

Bollettino Valanghe N. 335/2026 del 05/02/2026 ore 14.00
Validità 48 ore prossima emissione 06/02/2026

A cura del Servizio METEOMONT dell'ARMA dei CARABINIERI
In collaborazione con Servizio Meteorologico dell'Aeronautica militare

SITUAZIONE alle 14:00 del 05/02/2026

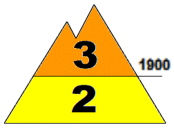

SITUAZIONE TIPO: brina di superficie sepolta.



SITUAZIONE TIPO: brina di superficie sepolta.

Quota neve (mslm)	Nord	Sud
	500-600	500-600

Altezza Neve (cm)	Neve al suolo	Neve Fresca	Quota (mslm)
	63	10	1782
	28	10	1156

VALANGHE OSSERVATE: Nessuna valanga.

PREVISIONI 06/02/2026

GRADO DI PERICOLO: MARCATO 3

SITUAZIONE TIPO: neve a debole coesione e vento.

SITUAZIONE TIPO: neve a debole coesione e vento.

MANTO NEVOSO: La stabilità del manto nevoso è molto scarsa su alcuni punti (aree) per tutte le esposizioni al di sopra di 2000 mslm, possibili valanghe di dimensioni medie.
La stabilità del manto nevoso è scarsa su alcuni punti (aree) per tutte le esposizioni al di sotto di 2000 mslm, possibili valanghe di dimensioni piccole.

AVVERTENZE

In considerazione dei recenti apporti di neve fresca, è richiesta una buona valutazione locale della stabilità ed individuazione dell'itinerario.

SCALA EUROPEA DEL GRADO DI PERICOLO VALANGHE

5 - MOLTO FORTE | 4 - FORTE | 3 - MARCATO | 2 - MODERATO | 1 - DEBOLE | NO NEVE | NO INFO

LEGENDA PROBLEMA

NEVE FRESCA | LASTRONI DA VENTO | STRATI DEBOLI PERSISTENTI | NEVE BAGNATA | SLITTAMENTO | CORNICI | NESSUN PROBLEMA VALANGHIVO EVIDENTE | NO_INFO

Bollettino realizzato su scala sinottica-regionale (standard EAWS). La sua valutazione non può escludere in alcun modo la necessità di una seria e capace valutazione locale del pericolo (singolo pendio) che può essere anche sensibilmente diverso. Le previsioni meteorologiche sono relative all'orario UTC (per l'Italia +1 in inverno e +2 in estate).

PREALPI LOMBARDE

PREVISIONE METEO

Quota		06/02/2026 h6:00	06/02/2026 h12:00	06/02/2026 h18:00
1000	Venti	01 Nodi da N-Est	01 Nodi da Nord	02 Nodi da N-Est
	Temperature	-02 °C	+00 °C	+02 °C
	Temp.percepita	-2 °C	0 °C	2 °C
2000	Venti	01 nodi da N-Ovest	03 Nodi da Nord	02 Nodi da Nord
	Temperature	-02 °C	-01 °C	+01 °C
	Temp.percepita	-2 °C	-3 °C	1 °C
3000	Venti	04 Nodi da Ovest	07 Nodi da Nord	05 Nodi da Nord
	Temperature	-08 °C	-07 °C	-07 °C
	Temp.percepita	-12 °C	-13 °C	-11 °C
Zero termico		1300-1500 m.	1700-1900 m.	2100-2300 m.
Fenomeno			—	—
Stato del cielo				

LEGENDA FENOMENI

— Assenza Fenomeni · Nebbia · Foschia · Pioggia debole · Pioggia moderata · Pioggia forte · Temporali

Nevicata debole · Nevicata moderata · Nevicata forte

STATO DEL CIELO

Sereno · Poco nuvoloso · Nuvoloso · Molto nuvoloso · Coperto

Parametri meteonivometrici registrati presso i campi di rilevamento il 05/02/2026.

Località	Comune	Quota (m.s.l.m.)	Altezza neve (cm)	Neve caduta nelle 24 ore (cm)	Temp. Min (°C)	Temp. Max (°C)	Condizioni del tempo
RIFUGIO BRUNO	Alta Valle Intelvi (CO)	1156	28	10	-2	+12	Assenza di precipitazioni
BASSINALE	Artogne (BS)	1782	63	10	N.P.	N.P.	Assenza di precipitazioni
PASSO MANIVA	Collio (BS)	1751	38	9	-3	0	Assenza di precipitazioni
ALPE PAGLIO *	Casargo (LC)	1434	28	N.P.	N.P.	N.P.	Assenza di precipitazioni

(*) Rilievi fuori campo

L'INFORMAZIONE E' PREVENZIONE - LEGGI L'ATTUALE GRADO DI PERICOLO VALANGHE!

IL CAPO DEL CENTRO NAZIONALE METEOMONT
(Ten. Col. RFI Emanuela Gini)
FIRMA AUTOGRAFA OMESSA AI SENSI
DELL'ART.3 DEL D.LGS N.39/1993