MINISTERO DELLA DIFESA

meteomont
Servizio Nazionale di previsione neve e valanghe

EAWS EUROPEAN AVALANCHE WARNING SERVICES

CARABINIERI

AERONAUTICA MILITARE SERVIZIO METEOROLOGICO

ALPI COZIE SUD

Bollettino Valanghe N. 336/2026 del 05/02/2026 ore 14.00
Validità 48 ore prossima emissione 06/02/2026

A cura del Servizio METEOMONT dell'ARMA dei CARABINIERI
In collaborazione con Servizio Meteorologico dell'Aeronautica militare

SITUAZIONE alle 14:00 del 05/02/2026

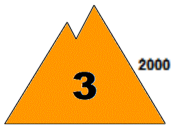

SITUAZIONE TIPO: neve a debole coesione e vento.



SITUAZIONE TIPO: nessuna situazione tipo evidente.

Quota neve (mslm)	Nord	Sud
	600	700

Altezza Neve (cm)	Neve al suolo	Neve Fresca	Quota (mslm)
	131	000	2135
	125	000	1750

VALANGHE OSSERVATE: Nessuna valanga.

PREVISIONI 06/02/2026

GRADO DI PERICOLO: FORTE 4

SITUAZIONE TIPO: neve a debole coesione e vento.

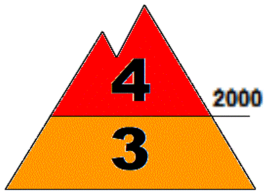

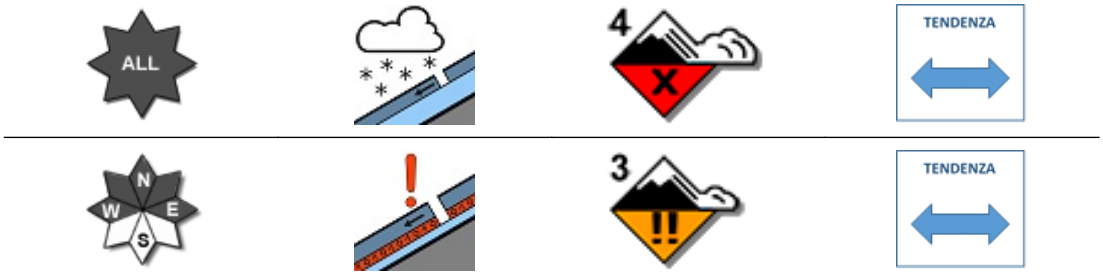

SITUAZIONE TIPO: nessuna situazione tipo evidente.

MANTO NEVOSO: La stabilità del manto nevoso è molto scarsa su molti punti (aree) per tutte le esposizioni al di sopra di 2000 mslm, possibili valanghe di dimensioni grandi.
La stabilità del manto nevoso è molto scarsa su alcuni punti (aree) per versanti da ovest a est al di sotto di 2000 mslm, possibili valanghe di dimensioni grandi.

AVVERTENZE

A seguito dell'attività eolica registrata sono da evitare le zone di accumulo, conche, canaloni, cambi di pendenza e pendii sotto vento in genere.

SCALA EUROPEA DEL GRADO DI PERICOLO VALANGHE

LEGENDA PROBLEMA

Bollettino realizzato su scala sinottica-regionale (standard EAWS). La sua valutazione non può escludere in alcun modo la necessità di una seria e capace valutazione locale del pericolo (singolo pendio) che può essere anche sensibilmente diverso. Le previsioni meteorologiche sono relative all'orario UTC (per l'Italia +1 in inverno e +2 in estate).

MINISTERO DELLA DIFESA

meteomont
Servizio Nazionale di previsione neve e valanghe

EAWS EUROPEAN AVALANCHE WARNING SERVICES

CARABINIERI

ALPI COZIE SUD

PREVISIONE METEO

Quota		06/02/2026 h6:00	06/02/2026 h12:00	06/02/2026 h18:00
1000	Venti	01 Nodi da S-Ovest	02 Nodi da Ovest	02 Nodi da S-Ovest
	Temperature	+00 °C	+02 °C	-01 °C
	Temp.percepita	0 °C	2 °C	-1 °C
2000	Venti	03 Nodi da Ovest	05 Nodi da Ovest	04 Nodi da S-Ovest
	Temperature	+00 °C	+01 °C	-01 °C
	Temp.percepita	-2 °C	-2 °C	-4 °C
3000	Venti	07 nodi da N-Ovest	12 Nodi da Ovest	04 nodi da N-Ovest
	Temperature	-07 °C	-07 °C	-08 °C
	Temp.percepita	-13 °C	-14 °C	-12 °C
Zero termico		1900-2100 m.	2100-2300 m.	1100-1300 m.
Fenomeno		—	—	—
Stato del cielo				

LEGENDA FENOMENI

— Assenza Fenomeni
Nebbia
Foschia
Pioggia debole
Pioggia moderata
Pioggia forte
Temporali
Nevicata debole
Nevicata moderata
Nevicata forte

STATO DEL CIELO

Sereno
Poco nuvoloso
Nuvoloso
Molto nuvoloso
Coperto

Parametri meteonivometrici registrati presso i campi di rilevamento il 05/02/2026.

Località	Comune	Quota (m.s.l.m.)	Altezza neve (cm)	Neve caduta nelle 24 ore (cm)	Temp. Min (°C)	Temp. Max (°C)	Condizioni del tempo
BORGATA CHIESA	Bellino (CN)	1480	91	0	N.P.	N.P.	Assenza di precipitazioni

(*) Rilievi fuori campo

L'INFORMAZIONE E' PREVENZIONE - LEGGI L'ATTUALE GRADO DI PERICOLO VALANGHE!

IL CAPO DEL CENTRO NAZIONALE METEOMONT
(Ten. Col. RFI Emanuela Gini)
FIRMA AUTOGRAFA OMESSA AI SENSI
DELL'ART.3 DEL D.LGS N.39/1993