MINISTERO DELLA DIFESA

meteomont Servizio Nazionale di previsione neve e valanghe

EAWS EUROPEAN AVALANCHE WARNING SERVICES

CARABINIERI

APPENNINO EMILIANO CENTRALE

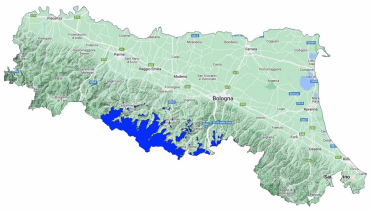

Bollettino Valanghe N. 309/2026 del 05/02/2026 ore 14.00
Validità 48 ore prossima emissione 06/02/2026

A cura del Servizio METEOMONT dell'ARMA dei CARABINIERI
In collaborazione con Servizio Meteorologico dell'Aeronautica militare

SITUAZIONE alle 14:00 del 05/02/2026

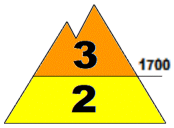

SITUAZIONE TIPO: neve a debole coesione e vento.



SITUAZIONE TIPO: neve a debole coesione e vento.

Quota neve (mslm)	Nord	Sud
	700	800

Altezza Neve (cm)	Neve al suolo	Neve Fresca	Quota (mslm)
	120	038	1840
	059	013	1550

VALANGHE OSSERVATE: Nessuna valanga.

PREVISIONI 06/02/2026

GRADO DI PERICOLO: MARCATO 3

SITUAZIONE TIPO: neve a debole coesione e vento.



SITUAZIONE TIPO: neve a debole coesione e vento.

MANTO NEVOSO: La stabilità del manto nevoso è scarsa su molti punti (aree) per versanti nord orientali al di sopra di 1700 mslm, possibili valanghe di dimensioni medie.
La stabilità del manto nevoso è scarsa su alcuni punti (aree) per tutte le esposizioni al di sotto di 1700 mslm, possibili valanghe di dimensioni medie.

AVVERTENZE

In considerazione delle avverse condizioni meteorologiche previste , le attività al di fuori delle piste battute e segnalate sono sconsigliate.

SCALA EUROPEA DEL GRADO DI PERICOLO VALANGHE

5 - MOLTO FORTE — *4 - FORTE* — *3 - MARCATO* — *2 - MODERATO* — *1 - DEBOLE* — NO NEVE *NO NEVE* — *NO INFO*

LEGENDA PROBLEMA

NEVE FRESCA — *LASTRONI DA VENTO* — *STRATI DEBOLI PERSISTENTI* — *NEVE BAGNATA* — *SLITTAMENTO* — *CORNICI* — *NESSUN PROBLEMA VALANGHIVO EVIDENTE* — *NO_INFO*

Bollettino realizzato su scala sinottica-regionale (standard EAWS). La sua valutazione non può escludere in alcun modo la necessità di una seria e capace valutazione locale del pericolo (singolo pendio) che può essere anche sensibilmente diverso. Le previsioni meteorologiche sono relative all'orario UTC (per l'Italia +1 in inverno e +2 in estate).

MINISTERO DELLA DIFESA

meteomont
Servizio Nazionale di previsione neve e valanghe

EAWS EUROPEAN AVALANCHE WARNING SERVICES

CARABINIERI

APPENNINO EMILIANO CENTRALE

PREVISIONE METEO

Quota		06/02/2026 h6:00	06/02/2026 h12:00	06/02/2026 h18:00
1000	Venti	03 Nodi da Nord	01 Nodi da S-Ovest	03 Nodi da S-Ovest
	Temperature	+00 °C	+03 °C	+03 °C
	Temp.percepita	-2 °C	3 °C	2 °C
2000	Venti	09 Nodi da N-Est	05 Nodi da Ovest	04 nodi da N-Ovest
	Temperature	-03 °C	-01 °C	+01 °C
	Temp.percepita	-8 °C	-4 °C	-1 °C
3000	Venti	06 Nodi da Ovest	09 nodi da N-Ovest	08 Nodi da Ovest
	Temperature	-06 °C	-07 °C	-07 °C
	Temp.percepita	-11 °C	-13 °C	-13 °C
Zero termico		1300-1500 m.	1800-2000 m.	2000-2200 m.
Fenomeno			—	—
Stato del cielo				

LEGENDA FENOMENI

— Assenza Fenomeni · Nebbia · Foschia · Pioggia debole · Pioggia moderata · Pioggia forte · Temporali

Nevicata debole · Nevicata moderata · Nevicata forte

STATO DEL CIELO

Sereno · Poco nuvoloso · Nuvoloso · Molto nuvoloso · Coperto

Parametri meteonivometrici registrati presso i campi di rilevamento il 05/02/2026.

Località	Comune	Quota (m.s.l.m.)	Altezza neve (cm)	Neve caduta nelle 24 ore (cm)	Temp. Min (°C)	Temp. Max (°C)	Condizioni del tempo
PASSO PRADARENA	Ventasso (RE)	1585	60	9	-2	0	Assenza di precipitazioni
RIFUGIO CAVONE	Lizzano in Belvedere (BO)	1416	52	3	0	+1	Assenza di precipitazioni
LAGO DELLA NINFA	Sestola (MO)	1550	59	13	-1	0	Assenza di precipitazioni
PIANCAVALLARO	Riolunato (MO)	1840	120	38	N.P.	N.P.	Assenza di precipitazioni
FEBBIO 2000 *	Villa Minozzo (RE)	2000	270	N.P.	N.P.	N.P.	Assenza di precipitazioni

(*) Rilievi fuori campo

L'INFORMAZIONE E' PREVENZIONE - LEGGI L'ATTUALE GRADO DI PERICOLO VALANGHE!

IL CAPO DEL CENTRO NAZIONALE METEOMONT
(Ten. Col. RFI Emanuela Gini)
FIRMA AUTOGRAFA OMESSA AI SENSI
DELL'ART.3 DEL D.LGS N.39/1993

Bollettino realizzato su scala sinottica-regionale (standard EAWS). La sua valutazione non può escludere in alcun modo la necessità di una seria e capace valutazione locale del pericolo (singolo pendio) che può essere anche sensibilmente diverso. Le previsioni meteorologiche sono relative all'orario UTC (per l'Italia +1 in inverno e +2 in estate).