MINISTERO DELLA DIFESA

meteomont Servizio Nazionale di previsione neve e valanghe

EAWS EUROPEAN AVALANCHE WARNING SERVICES

CARABINIERI

ALPI APUANE - APPENNINO TOSCANO SETTENTRIONALE

Bollettino Valanghe N. 248/2026 del 04/02/2026 ore 14.00
Validità 48 ore prossima emissione 05/02/2026

A cura del Servizio METEOMONT dell'ARMA dei CARABINIERI
In collaborazione con Servizio Meteorologico dell'Aeronautica militare

SITUAZIONE alle 14:00 del 04/02/2026

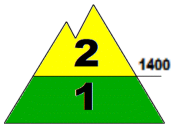

SITUAZIONE TIPO: strato debole persistente basale.



SITUAZIONE TIPO: situazione primaverile.

Quota neve (mslm)	Nord	Sud
	1200 - 1400	1300 - 1400

Altezza Neve (cm)	Neve al suolo	Neve Fresca	Quota (mslm)
	060	017	1625
	047	007	1340

VALANGHE OSSERVATE: Nessuna valanga.

PREVISIONI 05/02/2026

GRADO DI PERICOLO: MODERATO 2

SITUAZIONE TIPO: nevicata dopo un lungo periodo di freddo.

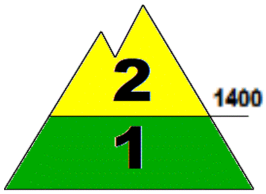

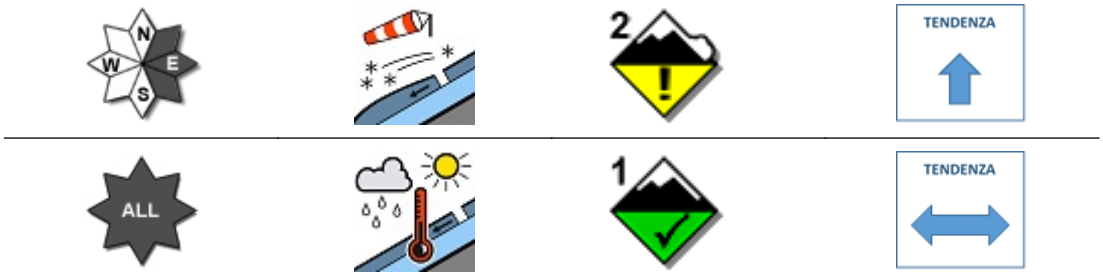

SITUAZIONE TIPO: situazione primaverile.

MANTO NEVOSO: La stabilità del manto nevoso è discreta su alcuni punti (aree) per versanti orientali al di sopra di 1400 mslm, possibili valanghe di dimensioni medie.
La stabilità del manto nevoso è buona su pochi punti (aree) per tutte le esposizioni al di sotto di 1400 mslm, possibili valanghe di dimensioni medie.

AVVERTENZE

In considerazione delle avverse condizioni meteorologiche in atto, le attività al di fuori delle piste battute e segnalate sono limitate. Se effettuate, richiedono ottime capacità di valutazione del pericolo locale.

SCALA EUROPEA DEL GRADO DI PERICOLO VALANGHE

5 - MOLTO FORTE | 4 - FORTE | 3 - MARCATO | 2 - MODERATO | 1 - DEBOLE | NO NEVE | NO INFO

LEGENDA PROBLEMA

NEVE FRESCA | LASTRONI DA VENTO | STRATI DEBOLI PERSISTENTI | NEVE BAGNATA | SLITTAMENTO | CORNICI | NESSUN PROBLEMA VALANGHIVO EVIDENTE | NO_INFO

Bollettino realizzato su scala sinottica-regionale (standard EAWS). La sua valutazione non può escludere in alcun modo la necessità di una seria e capace valutazione locale del pericolo (singolo pendio) che può essere anche sensibilmente diverso. Le previsioni meteorologiche sono relative all'orario UTC (per l'Italia +1 in inverno e +2 in estate).

MINISTERO DELLA DIFESA

meteomont
Servizio Nazionale di previsione neve e valanghe

EAWS EUROPEAN AVALANCHE WARNING SERVICES

CARABINIERI

ALPI APUANE - APPENNINO TOSCANO SETTENTRIONALE

PREVISIONE METEO

Quota		05/02/2026 h6:00	05/02/2026 h12:00	05/02/2026 h18:00
1000	Venti	02 Nodi da Ovest	03 Nodi da S-Ovest	04 Nodi da Sud
	Temperature	+01 °C	+02 °C	+02 °C
	Temp.percepita	1 °C	0 °C	-0 °C
2000	Venti	06 nodi da Ovest	07 Nodi da S-Ovest	10 Nodi da S-Ovest
	Temperature	-03 °C	-03 °C	+00 °C
	Temp.percepita	-7 °C	-8 °C	-5 °C
3000	Venti	09 nodi da N-Ovest	07 Nodi da Ovest	11 nodi da Ovest
	Temperature	-06 °C	-07 °C	-05 °C
	Temp.percepita	-12 °C	-13 °C	-12 °C
Zero termico		1400-1600 m.	1600-1800 m.	2100-2300 m.
Fenomeno		—	—	—
Stato del cielo				

LEGENDA FENOMENI

— Assenza Fenomeni · Nebbia · Foschia · Pioggia debole · Pioggia moderata · Pioggia forte · Temporali

Nevicata debole · Nevicata moderata · Nevicata forte

STATO DEL CIELO

Sereno · Poco nuvoloso · Nuvoloso · Molto nuvoloso · Coperto

Parametri meteonivometrici registrati presso i campi di rilevamento il 04/02/2026.

Località	Comune	Quota (m.s.l.m.)	Altezza neve (cm)	Neve caduta nelle 24 ore (cm)	Temp. Min (°C)	Temp. Max (°C)	Condizioni del tempo
PONTE ALLE LIME	Abetone Cutigliano (PT)	1340	47	7	N.P.	N.P.	Nevicata moderata
ORECCHIELLA	San Romano in Garfagnana (LU)	1240	0	0	+2	+8	Pioggia debole continua
ALPE DI SAN PELLEGRINO	Castiglione di Garfagnana (LU)	1651	46	12	-1	+2	Nevicata moderata
RIFUGIO ROSSI *	Molazzana (LU)	1625	60	17	N.P.	N.P.	Nevicata moderata
PRATI DELLA PANIA *	Molazzana (LU)	1522	34	3	N.P.	N.P.	Nevicata moderata

(*) Rilievi fuori campo

L'INFORMAZIONE E' PREVENZIONE - LEGGI L'ATTUALE GRADO DI PERICOLO VALANGHE!

IL CAPO DEL CENTRO NAZIONALE METEOMONT
(Ten. Col. RFI Emanuela Gini)
FIRMA AUTOGRAFA OMESSA AI SENSI
DELL'ART.3 DEL D.LGS N.39/1993

Bollettino realizzato su scala sinottica-regionale (standard EAWS). La sua valutazione non può escludere in alcun modo la necessità di una seria e capace valutazione locale del pericolo (singolo pendio) che può essere anche sensibilmente diverso. Le previsioni meteorologiche sono relative all'orario UTC (per l'Italia +1 in inverno e +2 in estate).