MINISTERO DELLA DIFESA

meteomont Servizio Nazionale di previsione neve e valanghe

EAWS EUROPEAN AVALANCHE WARNING SERVICES

CARABINIERI

ALPI APUANE - APPENNINO TOSCANO SETTENTRIONALE

Bollettino Valanghe N. 249/2026 del 05/02/2026 ore 14.00
Validità 48 ore prossima emissione 06/02/2026

A cura del Servizio METEOMONT dell'ARMA dei CARABINIERI
In collaborazione con Servizio Meteorologico dell'Aeronautica militare

SITUAZIONE alle 14:00 del 05/02/2026

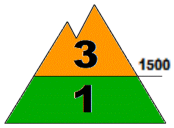

SITUAZIONE TIPO: strato debole persistente basale.



SITUAZIONE TIPO: situazione primaverile.

Quota neve (mslm)	Nord	Sud
	1200 - 1400	1300 - 1400

Altezza Neve (cm)	Neve al suolo	Neve Fresca	Quota (mslm)
	210	018	1858
	047	007	1340

VALANGHE OSSERVATE: Valanghe di piccole dimensioni, Valanghe di neve a debole coesione di superficie.

PREVISIONI 06/02/2026

GRADO DI PERICOLO: MARCATO 3

SITUAZIONE TIPO: nevicata dopo un lungo periodo di freddo.

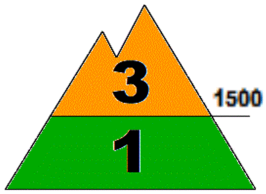

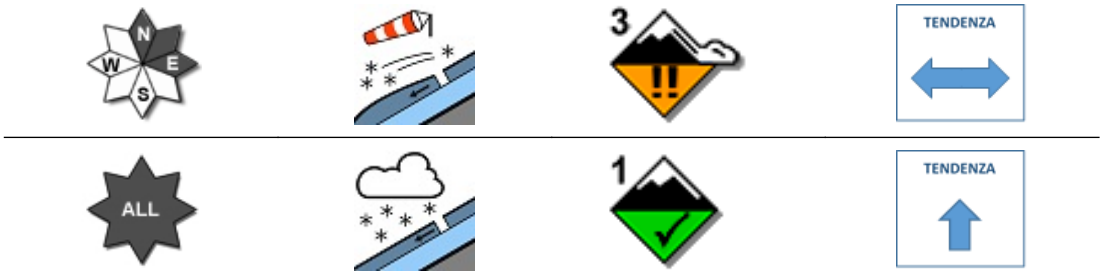

SITUAZIONE TIPO: strato debole persistente basale.

MANTO NEVOSO: La stabilità del manto nevoso è scarsa su molti punti (aree) per versanti nord orientali al di sopra di 1500 mslm, possibili valanghe di dimensioni medie.
La stabilità del manto nevoso è buona su pochi punti (aree) per tutte le esposizioni al di sotto di 1500 mslm, possibili valanghe di dimensioni medie.

AVVERTENZE

Viste le condizioni del manto nevoso, le attività al di fuori delle piste battute e segnalate richiedono buone capacità di valutazione del pericolo locale.

SCALA EUROPEA DEL GRADO DI PERICOLO VALANGHE

LEGENDA PROBLEMA

Bollettino realizzato su scala sinottica-regionale (standard EAWS). La sua valutazione non può escludere in alcun modo la necessità di una seria e capace valutazione locale del pericolo (singolo pendio) che può essere anche sensibilmente diverso. Le previsioni meteorologiche sono relative all'orario UTC (per l'Italia +1 in inverno e +2 in estate).

MINISTERO DELLA DIFESA

meteomont
Servizio Nazionale di previsione neve e valanghe

EAWS EUROPEAN AVALANCHE WARNING SERVICES

CARABINIERI

ALPI APUANE - APPENNINO TOSCANO SETTENTRIONALE

PREVISIONE METEO

Quota		06/02/2026 h6:00	06/02/2026 h12:00	06/02/2026 h18:00
1000	Venti	04 Nodi da Nord	01 Nodi da S-Ovest	02 Nodi da S-Ovest
	Temperature	+00 °C	+01 °C	+02 °C
	Temp.percepita	-3 °C	1 °C	2 °C
2000	Venti	11 Nodi da N-Est	04 nodi da Ovest	05 nodi da Ovest
	Temperature	-03 °C	-01 °C	+01 °C
	Temp.percepita	-9 °C	-4 °C	-2 °C
3000	Venti	08 Nodi da Ovest	10 nodi da N-Ovest	08 Nodi da Ovest
	Temperature	-05 °C	-07 °C	-06 °C
	Temp.percepita	-11 °C	-14 °C	-12 °C
Zero termico		1300-1500 m.	1700-1900 m.	2000-2200 m.
Fenomeno			—	—
Stato del cielo				

LEGENDA FENOMENI

— Assenza Fenomeni · Nebbia · Foschia · Pioggia debole · Pioggia moderata · Pioggia forte · Temporali

Nevicata debole · Nevicata moderata · Nevicata forte

STATO DEL CIELO

Sereno · Poco nuvoloso · Nuvoloso · Molto nuvoloso · Coperto

Parametri meteonivometrici registrati presso i campi di rilevamento il 05/02/2026.

Località	Comune	Quota (m.s.l.m.)	Altezza neve (cm)	Neve caduta nelle 24 ore (cm)	Temp. Min (°C)	Temp. Max (°C)	Condizioni del tempo
PONTE ALLE LIME	Abetone Cutigliano (PT)	1340	51	5	N.P.	N.P.	Assenza di precipitazioni
OTE GONITO *	Abetone Cutigliano (PT)	1746	140	15	N.P.	N.P.	Nevicata debole continua
ALPE TRE POTENZE *	Abetone Cutigliano (PT)	1858	210	18	N.P.	N.P.	Assenza di precipitazioni

(*) Rilievi fuori campo

L'INFORMAZIONE E' PREVENZIONE - LEGGI L'ATTUALE GRADO DI PERICOLO VALANGHE!

IL CAPO DEL CENTRO NAZIONALE METEOMONT
(Ten. Col. RFI Emanuela Gini)
FIRMA AUTOGRAFA OMESSA AI SENSI
DELL'ART.3 DEL D.LGS N.39/1993

Bollettino realizzato su scala sinottica-regionale (standard EAWS). La sua valutazione non può escludere in alcun modo la necessità di una seria e capace valutazione locale del pericolo (singolo pendio) che può essere anche sensibilmente diverso. Le previsioni meteorologiche sono relative all'orario UTC (per l'Italia +1 in inverno e +2 in estate).