MINISTERO DELLA DIFESA

meteomont
Servizio Nazionale di previsione neve e valanghe

EAWS EUROPEAN AVALANCHE WARNING SERVICES

CARABINIERI

AERONAUTICA MILITARE SERVIZIO METEOROLOGICO

MONTI SIMBRUINI E META

Bollettino Valanghe N. 271/2026 del 05/02/2026 ore 14.00
Validità 48 ore prossima emissione 06/02/2026

A cura del Servizio METEOMONT dell'ARMA dei CARABINIERI
In collaborazione con Servizio Meteorologico dell'Aeronautica militare

SITUAZIONE alle 14:00 del 05/02/2026

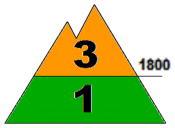

SITUAZIONE TIPO: neve a debole coesione e vento.

SITUAZIONE TIPO: pioggia su neve.

Quota neve (mslm)	Nord	Sud
	1400 - 1500	1600 - 1700

Altezza Neve (cm)	Neve al suolo	Neve Fresca	Quota (mslm)
	076	010	1790
	012	002	1430

VALANGHE OSSERVATE: Nessuna valanga.

PREVISIONI 06/02/2026

GRADO DI PERICOLO: MARCATO 3

SITUAZIONE TIPO: neve a debole coesione e vento.

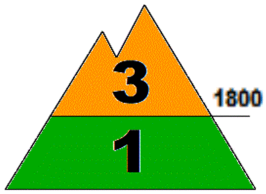

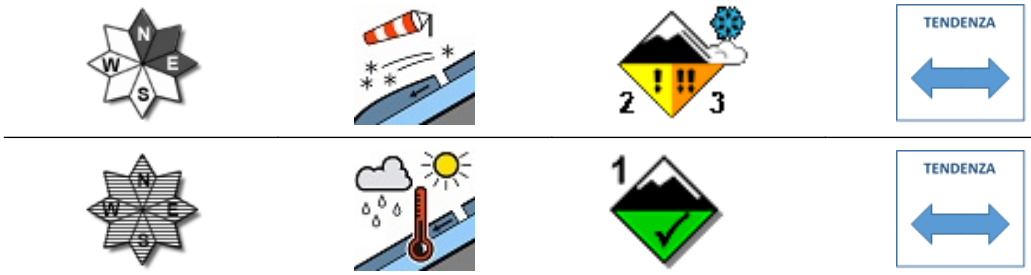

SITUAZIONE TIPO: pioggia su neve.

MANTO NEVOSO: La stabilità del manto nevoso è molto scarsa su alcuni punti (aree) per versanti nord orientali al di sopra di 1800 mslm, possibili valanghe di dimensioni grandi.
La stabilità del manto nevoso è discreta su alcuni punti (aree) per isolati pendii al di sotto di 1800 mslm, possibili valanghe di dimensioni piccole.

AVVERTENZE

In considerazione delle avverse condizioni meteorologiche in atto, le attività al di fuori delle piste battute e segnalate sono limitate. Se effettuate, richiedono ottime capacità di valutazione del pericolo locale.

SCALA EUROPEA DEL GRADO DI PERICOLO VALANGHE

LEGENDA PROBLEMA

Bollettino realizzato su scala sinottica-regionale (standard EAWS). La sua valutazione non può escludere in alcun modo la necessità di una seria e capace valutazione locale del pericolo (singolo pendio) che può essere anche sensibilmente diverso. Le previsioni meteorologiche sono relative all'orario UTC (per l'Italia +1 in inverno e +2 in estate).

MONTI SIMBRUINI E META

PREVISIONE METEO

Quota		06/02/2026 h6:00	06/02/2026 h12:00	06/02/2026 h18:00
1000	Venti	08 Nodi da S-Ovest	09 Nodi da Ovest	04 nodi da Ovest
	Temperature	+05 °C	+03 °C	+03 °C
	Temp.percepita	2 °C	-1 °C	1 °C
2000	Venti	21 Nodi da Ovest	25 nodi da Ovest	17 nodi da N-Ovest
	Temperature	+01 °C	-01 °C	-01 °C
	Temp.percepita	-6 °C	-9 °C	-8 °C
3000	Venti	22 Nodi da Ovest	25 Nodi da Ovest	19 Nodi da Ovest
	Temperature	-06 °C	-05 °C	-05 °C
	Temp.percepita	-15 °C	-15 °C	-14 °C
Zero termico		2100-2300 m.	1700-1900 m.	1700-1900 m.
Fenomeno			—	—
Stato del cielo				

LEGENDA FENOMENI

— Assenza Fenomeni · Nebbia · Foschia · Pioggia debole · Pioggia moderata · Pioggia forte · Temporali

Nevicata debole · Nevicata moderata · Nevicata forte

STATO DEL CIELO

Sereno · Poco nuvoloso · Nuvoloso · Molto nuvoloso · Coperto

Parametri meteonivometrici registrati presso i campi di rilevamento il 05/02/2026.

Località	Comune	Quota (m.s.l.m.)	Altezza neve (cm)	Neve caduta nelle 24 ore (cm)	Temp. Min (°C)	Temp. Max (°C)	Condizioni del tempo
PRATI DI MEZZO	Picinisco (FR)	1430	12	2 cm di neve fresca mista a pioggia	0	+2	Assenza di precipitazioni
CAMPO DELL'OSSO	Subiaco (RM)	1550	28	1	-1	+3	Assenza di precipitazioni
C.STAFFI	Filettino (FR)	1780	67	6	-2	0	Assenza di precipitazioni
CAMPO CATINO	Guarcino (FR)	1790	76	10	-2	+1	Assenza di precipitazioni

(*) Rilievi fuori campo

L'INFORMAZIONE E' PREVENZIONE - LEGGI L'ATTUALE GRADO DI PERICOLO VALANGHE!

IL CAPO DEL CENTRO NAZIONALE METEOMONT
(Ten. Col. RFI Emanuela Gini)
FIRMA AUTOGRAFA OMESSA AI SENSI
DELL'ART.3 DEL D.LGS N.39/1993

Bollettino realizzato su scala sinottica-regionale (standard EAWS). La sua valutazione non può escludere in alcun modo la necessità di una seria e capace valutazione locale del pericolo (singolo pendio) che può essere anche sensibilmente diverso. Le previsioni meteorologiche sono relative all'orario UTC (per l'Italia +1 in inverno e +2 in estate).