Bulletin d'estimation du risque d'avalanche

(valable en dehors des pistes balisées et ouvertes)

MASSIF : Beaufortain

Rédigé le jeudi 5 février 2026 à 16h

Estimation des risques pour le : VENDREDI 06 FÉVRIER

NOUVELLE CHUTE DE NEIGE VENANT APPORTER QUELQUES NOUVELLES INSTABILITÉS

3

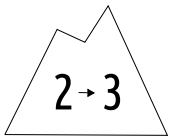

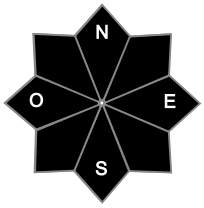

Indice de risque limité évoluant en marqué.

Départs spontanés : Dans les pentes les plus raides dès que le cumul de fraiche sera critique

Déclenchements provoqués : Petits départs en plaque friable au fur et à mesure des chutes dans la neige fraiche.

Indices de risque : 5 très fort - 4 fort - 3 marqué - 2 limité - 1 faible -- En noir : les pentes les plus dangereuses

Stabilité du manteau neigeux

Situation avalancheuse typique : neige fraîche

Déclenchements provoqués : Les quelques **nouvelles plaques friables d'aspect poudreux** qui vont se former au cours des chutes plus ou moins ventées attendues seront **très faciles à déclencher** par un seul skieur. Occasionnant généralement des **départs de petites tailles** cassure 30 le matin puis 50 cm en fin de journée. On pourra peu à peu en trouver dans les accumulations derrière les ruptures de pentes en **toutes orientations.**

Au dessus de 1800m et en versants froids (Est/Nord/Ouest) des couches fragiles persistantes enfouies profondément dans le manteau pourront être très localement réactivées par ces plaques de surface et alors **engendrer de plus grandes et larges avalanches taille 3**

Observables: neige fraiche un peu plus dense sur neige plus molle, fissures devant les skis

Départs spontanés : Nouvelles plaques en formation lors des chutes de neige ventées qui débutent ce jeudi soir (cumul attendu vendredi fin de journée 25/30cm localement 35 cm). Ces plaques taille 1 puis taille 2 rarement taille 3 si une plaque de surface engendre en cascade une plaque plus profonde posée sur les couches fragiles persistantes enfouies. Premiers petits départs possibles dans les pentes les plus raides dès que le cumul de fraiche atteindra les 15/20cm.
Sous 1500m possibles petites avalanches de neige humide au moment de la pluie.

Qualité de la neige

Enneigement : Un peu en dessous des normales de saison mais les chutes à venir (dans la semaine) devraient améliorer nettement l'enneigement

Limite skiable : Les versants froids voyant pas ou peu le soleil ont gardé de la neige à basse altitude, skiable sur l'herbe ou sur pistes forestières dès 700 à 900m. Sous bois skiables dès 1200m. En versant sud skiable dès 1300/1400m en prairies pas trop raides, 1600/1700m en Sud raide.

Qualité de la neige : Demain vendredi , la neige fraiche le plus souvent poudreuse viendra recouvrir peu à peu un manteau souvent travaillé par le vent, surtout à haute altitude et sur les moindres crêtes ou croupes. Sous 1500/1600m la neige fraiche pourra être humide voir collante.

Aperçu météo pour le vendredi 06 février

	nuit	matin	après-midi	soir
	Vent fort de sud à l'avant du front.	Bouché avec neige cette journée sous un vent modéré WNW	nuit de jeudi à vendredi, averses en	
Pluie-Neige	1 400 m	1 300 m	1 400 m	
Iso 0 °C	1 900 m	1 700 m	1 800 m	1 700 m
Vent 2000 m	↖ 25 km/h	→ 15 km/h	→ 20 km/h	↑ 10 km/h
Vent 3000 m	↑ 40 km/h	→ 35 km/h	→ 25 km/h	→ 20 km/h

Épaisseur de neige hors-piste

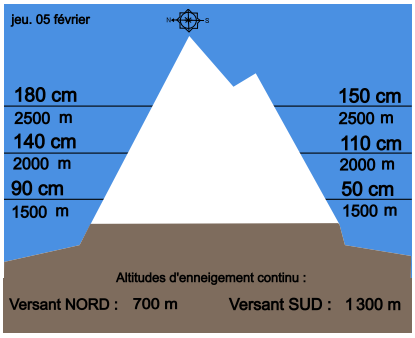

Précipitations à 1800 m

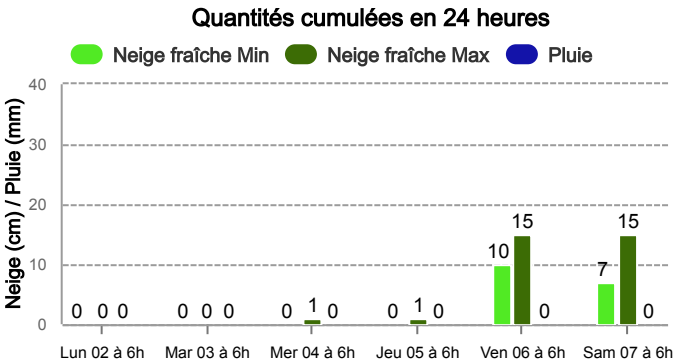

Tendance du samedi 07 février

3

Indice de risque marqué

Retour du beau temps voilé, attention au risque accidentel qui va rester considérable dans un certain nombre de pentes surtout en large secteur Nord d'altitude si les cumuls attendus ce vendredi sont bien au rendez vous.

Pour consulter la vigilance en cours, veuillez vous rendre sur le site https://vigilance.meteofrance.fr/fr

Météo-France - 73 avenue de Paris, 94165 Saint-Mandé cedex - Contact : contact@meteo.fr

Rédigé par Météo-France avec la contribution des observateurs du réseau nivo-météorologiques. Partenariat : ANMSM (Maires de Stations de Montagne), DSF (Domaines Skiables de France), ADSP (Directeurs de Pistes et de la Sécurité des Stations de Sports d'Hiver) et autres acteurs de la montagne.

Bulletin neige & avalanches par téléphone au
0 892 68 10 20 Service 0,35 € / min + prix appel

RÉPUBLIQUE FRANÇAISE
Liberté Égalité Fraternité

METEO FRANCE
À VOS CÔTÉS, DANS UN CLIMAT QUI CHANGE

Bulletin d'estimation du risque d'avalanche

(valable en dehors des pistes balisées et ouvertes)

MASSIF : Beaufortain

Rédigé le jeudi 5 février 2026 à 16h

Conditions nivo-météo des 7 derniers jours

	ven. 30/01				sam. 31/01				dim. 01/02				lun. 02/02				mar. 03/02				mer. 04/02				jeu. 05/02			
	03h	09h	15h	21h	03h	09h	15h	21h	03h	09h	15h	21h	03h	09h	15h	21h	03h	09h	15h	21h	03h	09h	15h	21h	03h	09h	15h	21h
Météo																												
Vent (km/h)	40	35	25	25	25	20	15	15	10	10	15	20	35	35	50	65	70	65	50	45	60	30	20	20	35	25	35	30
à 3000m	→	→	→	↗	↗	↑	↑	→	↘	↘	→	↗	→	↗	↗	↑	↑	↗	↗	↑	↑	↑	↑	↗	→	↗	↗	↑
Vent (km/h)	10	15	15	10	15	10	10	10	5	5	10	10	20	20	40	55	60	50	30	20	50	20	10	10	10	15	15	25
à 2000m	↗	↗	↗	↖	↖	←	→	↗	↑	↑	→	↑	↗	↖	↖	←	↖	↑	↖	↖	←	←	←	↖	←	↖	↖	↖

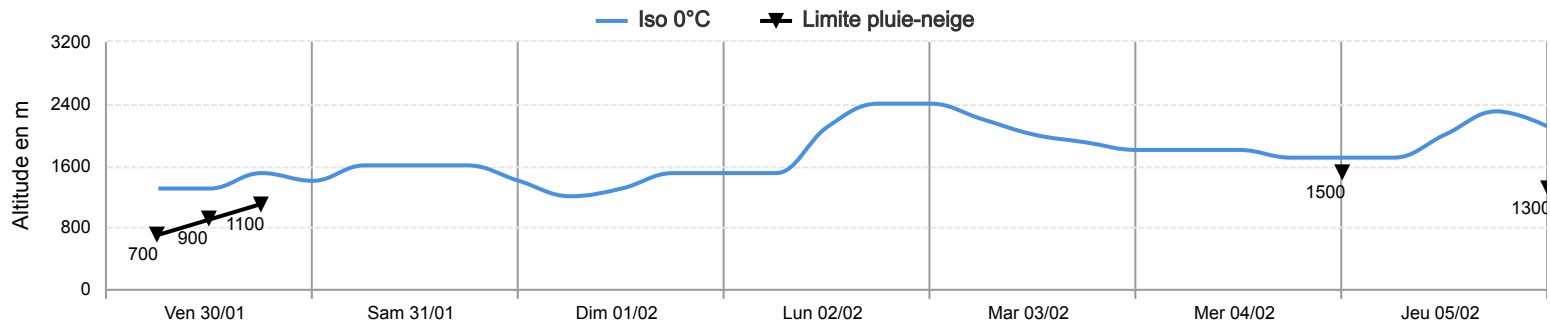

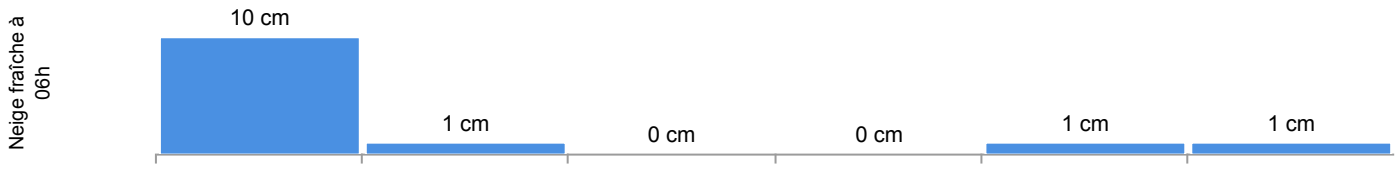

Risque d'avalanche	ven. 30/01	sam. 31/01	dim. 01/02	lun. 02/02	mar. 03/02	mer. 04/02	jeu. 05/02
	3	3	3	3	3	3	2

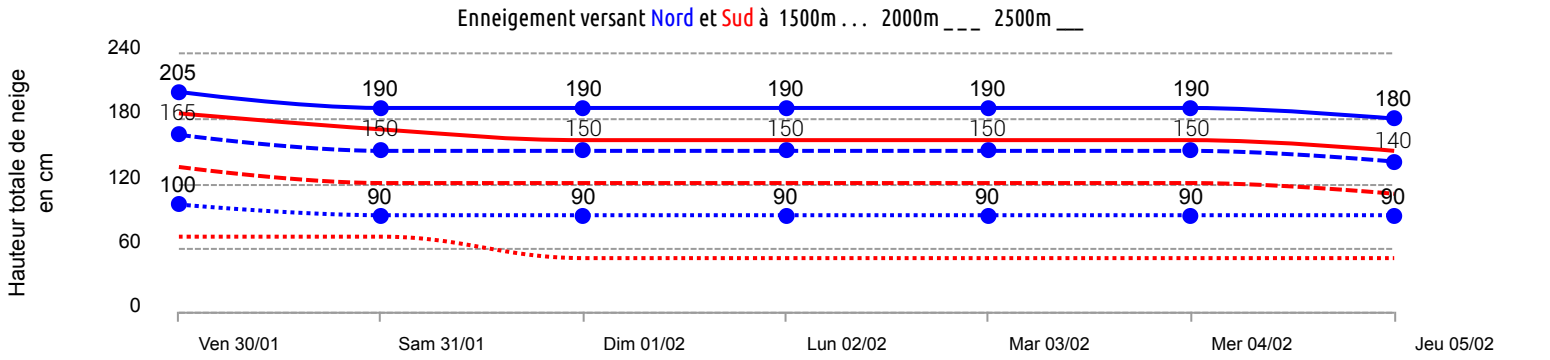

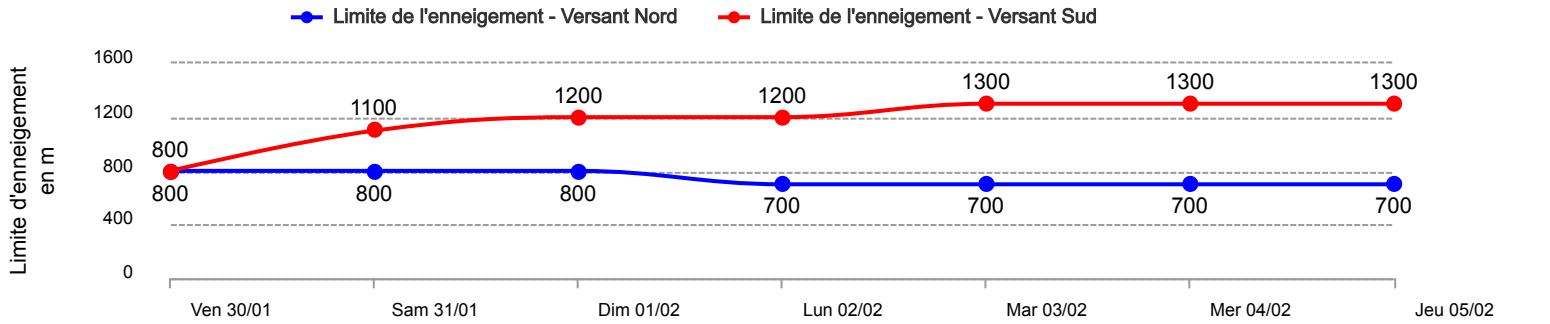

Pour consulter la vigilance en cours, veuillez vous rendre sur le site https://vigilance.meteofrance.fr/fr

Météo-France - 73 avenue de Paris, 94165 Saint-Mandé cedex - Contact : contact@meteo.fr

Bulletin neige & avalanches par téléphone au **0 892 68 10 20** Service 0,35 € / min + prix appel

Rédigé par Météo-France avec la contribution des observateurs du réseau nivo-météorologiques. Partenariat : ANMSM (Maires de Stations de Montagne), DSF (Domaines Skiables de France), ADSP (Directeurs de Pistes et de la Sécurité des Stations de Sports d'Hiver) et autres acteurs de la montagne.