Bulletin d'estimation du risque d'avalanche
(valable en dehors des pistes balisées et ouvertes)

MASSIF : Belledonne

Rédigé le jeudi 5 février 2026 à 16h

Estimation des risques pour le : VENDREDI 06 FÉVRIER

INSTABILITÉS DANS LA NEIGE DE SURFACE.

3

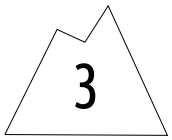

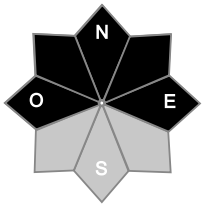

Indice de risque marqué.

Départs spontanés : Coulées de neige fraîche pendant la chute.

Déclenchements provoqués : Plaques friables faciles à déclencher.

Indices de risque : 5 très fort - 4 fort - 3 marqué - 2 limité - 1 faible -- En noir : les pentes les plus dangereuses

Stabilité du manteau neigeux

Situation avalancheuse typique : neige fraîche neige ventée

Déclenchements provoqués : ils concerneront surtout la petite couche de neige prévue jusqu'en milieu de nuit de jeudi à vendredi et accompagnée d'un vent de sud soutenu. Les plaques d'aspect poudreux ainsi formées seront probablement faciles à déclencher vendredi, en particulier près des ruptures de pente, mais ne dépasseront pas la taille 2. Dans un nombre de cas restreint, le déclenchement d'une de ces plaques pourrait provoquer un départ plus important (taille 3 avec cassure atteignant jusqu'à 1 m) si les couches fragiles enfouies dans le manteau neigeux venaient à être sollicitées.

Départs spontanés : petites coulées de neige fraîche possibles dans les pentes le plus raides pendant les chutes. Quelques purges de taille modeste en journée de vendredi à la faveur des trouées de soleil, plutôt localisées près des rochers.

Qualité de la neige

Qualification de l'enneigement : l'enneigement est bon pour la saison, sauf aux altitudes les plus basses.

Limites skiables : vers 1100/1400 m.

Qualité de la neige vendredi : Petite couche de neige fraîche, parfois soufflée, surmontant un manteau neigeux très irrégulier.

Aperçu météo pour le vendredi 06 février

	nuit	matin	après-midi	soir
Pluie-Neige	1 500 m	1 400 m	1 400 m	
Iso 0 °C	2 000 m	1 700 m	1 800 m	1 700 m
Vent 2000 m	25 km/h	25 km/h	20 km/h	10 km/h
Vent 3000 m	40 km/h	30 km/h	25 km/h	20 km/h

Épaisseur de neige hors-piste

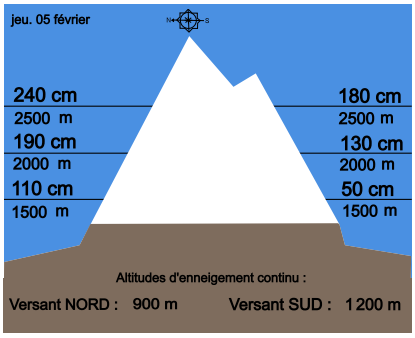

Précipitations à 1800 m

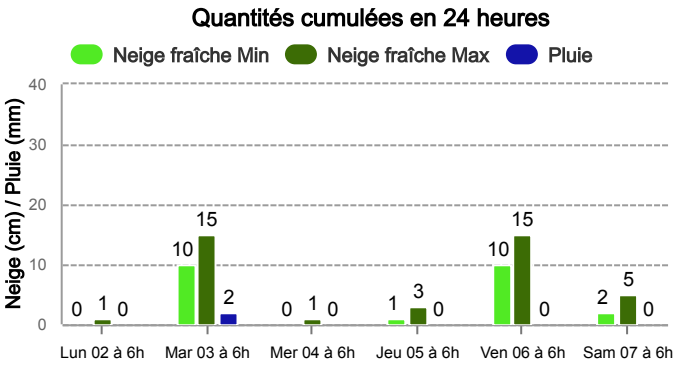

Tendance du samedi 07 février

3

Indice de risque marqué

Samedi, manteau neigeux en cours de stabilisation. Risque naturel en baisse, par contre les déclenchements resteront faciles..

Pour consulter la vigilance en cours, veuillez vous rendre sur le site https://vigilance.meteofrance.fr/fr

Météo-France - 73 avenue de Paris, 94165 Saint-Mandé cedex - Contact : contact@meteo.fr

Rédigé par Météo-France avec la contribution des observateurs du réseau nivo-météorologiques. Partenariat : ANMSM (Maires de Stations de Montagne), DSF (Domaines Skiables de France), ADSP (Directeurs de Pistes et de la Sécurité des Stations de Sports d'Hiver) et autres acteurs de la montagne.

Bulletin neige & avalanches par téléphone au
0 892 68 10 20 Service 0,35 € / min + prix appel

Bulletin d'estimation du risque d'avalanche

(valable en dehors des pistes balisées et ouvertes)

MASSIF : Belledonne

Rédigé le jeudi 5 février 2026 à 16h

Conditions nivo-météo des 7 derniers jours

	ven. 30/01				sam. 31/01				dim. 01/02				lun. 02/02				mar. 03/02				mer. 04/02				jeu. 05/02			
	03h	09h	15h	21h	03h	09h	15h	21h	03h	09h	15h	21h	03h	09h	15h	21h	03h	09h	15h	21h	03h	09h	15h	21h	03h	09h	15h	21h
Météo																												
Vent (km/h)	40	35	25	20	25	15	15	20	20	20	30	25	30	40	70	110	100	85	75	65	50	45	20	35	35	30	45	40
à 3000m																												
Vent (km/h)	15	20	15	15	15	10	10	10	10	10	15	15	15	20	60	100	85	65	55	40	35	30	20	15	15	15	30	20
à 2000m																												

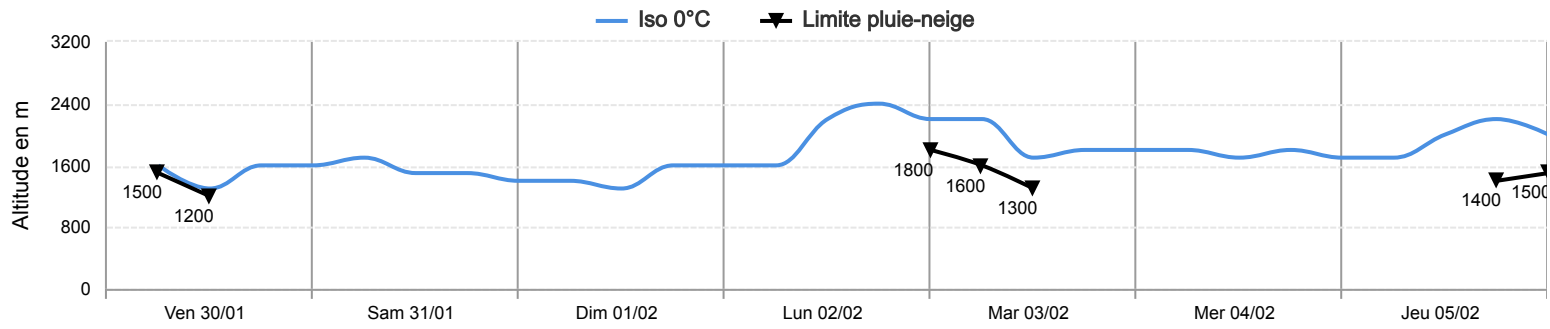

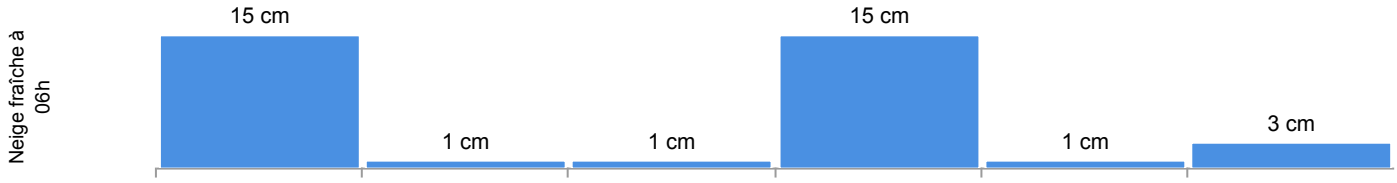

Risque d'avalanche	ven. 30/01	sam. 31/01	dim. 01/02	lun. 02/02	mar. 03/02	mer. 04/02	jeu. 05/02
	3	3	3	3	3	3	3

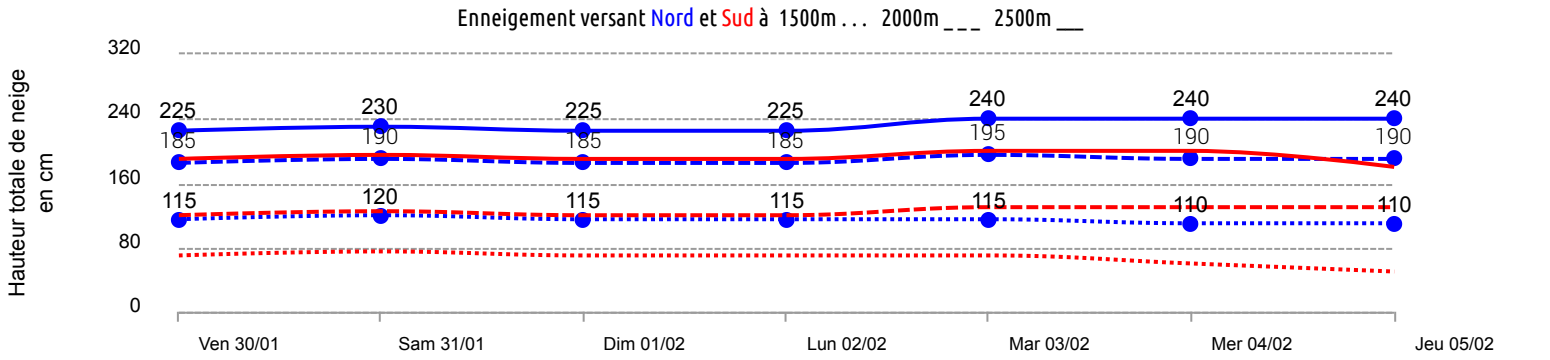

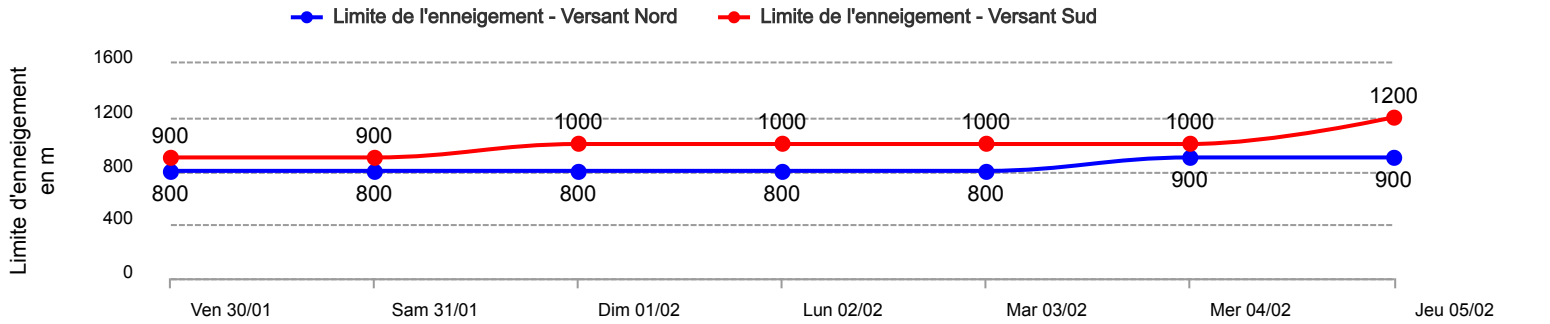

Pour consulter la vigilance en cours, veuillez vous rendre sur le site https://vigilance.meteofrance.fr/fr

Météo-France - 73 avenue de Paris, 94165 Saint-Mandé cedex - Contact : contact@meteo.fr

Bulletin neige & avalanches par téléphone au

0 892 68 10 20 Service 0,35 € / min + prix appel

Rédigé par Météo-France avec la contribution des observateurs du réseau nivo-météorologiques. Partenariat : ANMSM (Maires de Stations de Montagne), DSF (Domaines Skiables de France), ADSP (Directeurs de Pistes et de la Sécurité des Stations de Sports d'Hiver) et autres acteurs de la montagne.