Bulletin d'estimation du risque d'avalanche
(valable en dehors des pistes balisées et ouvertes)
MASSIF : Chablais

Rédigé le jeudi 5 février 2026 à 16h

Estimation des risques pour le : VENDREDI 06 FÉVRIER

INSTABILITÉ DANS LA NEIGE FRAICHE.

3

2→3

N O E S

Indice de risque limité évoluant en marqué.

Départs spontanés : purges dans la neige fraiche

Déclenchements provoqués : plaques dans la neige fraiche

Indices de risque : 5 très fort - 4 fort - 3 marqué - 2 limité - 1 faible -- En noir : les pentes les plus dangereuses

Stabilité du manteau neigeux

Situation avalancheuse typique : neige ventée — couche fragile persistante

Déclenchements provoqués :

* **Plaques dans la neige fraiche**. De plus en **plus nombreuses** et **épaisses au fil des chutes de neige**, des heures et en altitude. Taille 1 puis 2 (petite puis moyenne).
* Encore de vieille plaque à vent près des crêtes dans les **accumulations en ubacs**. Formées par le vent de S/SW. Taille 1
* Facteur aggravant : Une couche fragile persistante est enfouie dans les ubacs au-dessus de 1800/2000 m. Difficilement déclenchable par un skieur, mais dans une configuration d'**avalanche en cascade** (liée à une plaque à vent, une rupture de corniche, ...), elle pourrait céder et entraîner le manteau neigeux sur 70/90 cm d'épaisseur. Taille 3 possible.

Départs spontanés :

* Petites purges dans la neige fraiche au cours des chutes de neige. Taille 1 rarement 2 (petite rarement moyenne)

Qualité de la neige

Enneigement : Pour la saison, l'enneigement est déficitaire en dessous de 1600 m et correct au-dessus.
On peut chausser les skis vers 1000 m. Pas de sous-couche sous 1400 m ou sur les crêtes, des cailloux sont cachés sous la neige récente.

Qualité de la neige vendredi :
Fine couche de neige fraîche qui s'épaissit en cours de journées : de 7 à 15 cm en dessous de 1 800 m, 10/20 cm au-dessus.
En dessous de 2 000 m : cette neige fraîche repose sur un fond gelé en adret, plus souple ou ventée en ubacs.
Au-dessus de 2 000 m : le fond est souvent dur/ventée et parfois plus souple dans les secteurs à l'abri du vent de S.

Aperçu météo pour le vendredi 06 février

Averses de neige (limite pluie-neige 1300/1400 m), plus continue en matinée, plus intermitante l'après-midi.

	nuit	matin	après-midi	soir
Pluie-Neige	1 200 m	1 300 m	1 400 m	1 300 m
Iso 0 °C	1 900 m	1 700 m	1 700 m	1 600 m
Vent 2000 m	↗ 30 km/h	↗ 30 km/h	↗ 25 km/h	↗ 15 km/h
Vent 2500 m	→ 50 km/h	→ 45 km/h	→ 35 km/h	↗ 25 km/h

Épaisseur de neige hors-piste

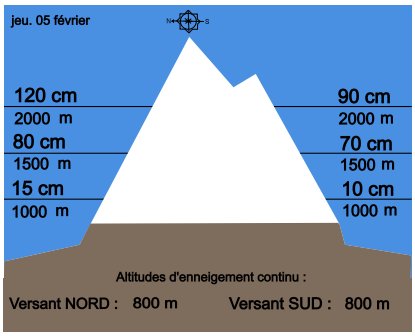

Précipitations à 1800 m

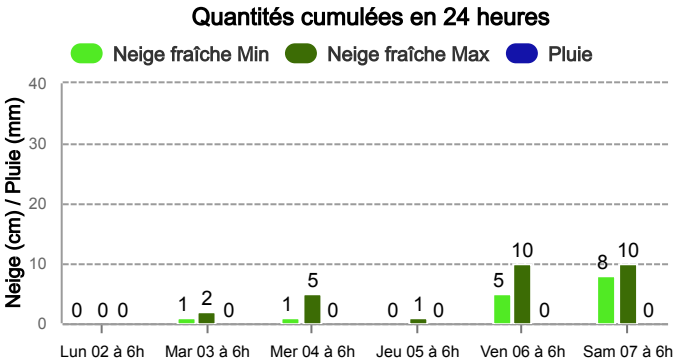

Tendance du samedi 07 février

3

Indice de risque marqué

Beau temps sur le massif. Risque stationnaire.

Pour consulter la vigilance en cours, veuillez vous rendre sur le site https://vigilance.meteofrance.fr/fr

Météo-France - 73 avenue de Paris, 94165 Saint-Mandé cedex - Contact : contact@meteo.fr

Rédigé par Météo-France avec la contribution des observateurs du réseau nivo-météorologiques. Partenariat : ANMSM (Maires de Stations de Montagne), DSF (Domaines Skiables de France), ADSP (Directeurs de Pistes et de la Sécurité des Stations de Sports d'Hiver) et autres acteurs de la montagne.

Bulletin neige & avalanches par téléphone au 0 892 68 10 20 Service 0,35 € / min + prix appel

RÉPUBLIQUE FRANÇAISE
Liberté Égalité Fraternité

METEO FRANCE
À VOS CÔTÉS, DANS UN CLIMAT QUI CHANGE

Bulletin d'estimation du risque d'avalanche

(valable en dehors des pistes balisées et ouvertes)

MASSIF : Chablais

Rédigé le jeudi 5 février 2026 à 16h

Conditions nivo-météo des 7 derniers jours

	ven. 30/01				sam. 31/01				dim. 01/02				lun. 02/02				mar. 03/02				mer. 04/02				jeu. 05/02			
	03h	09h	15h	21h	03h	09h	15h	21h	03h	09h	15h	21h	03h	09h	15h	21h	03h	09h	15h	21h	03h	09h	15h	21h	03h	09h	15h	21h
Météo																												
Vent (km/h)	35	40	30	30	30	15	10	10	10	15	30	40	45	50	55	55	55	70	50	40	20	15	10	20	30	35	45	40
à 2500m																												
Vent (km/h)	30	35	25	25	20	10	5	5	5	10	15	25	30	40	35	35	40	55	35	35	10	5	5	15	25	30	30	30
à 2000m																												

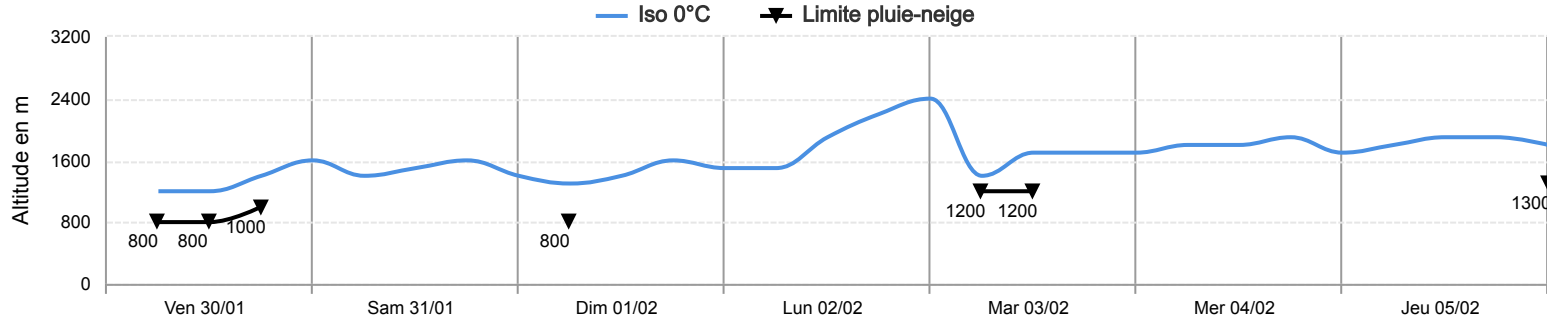

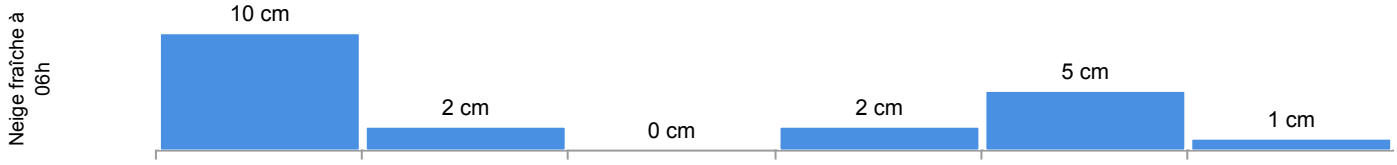

Risque d'avalanche	ven. 30/01	sam. 31/01	dim. 01/02	lun. 02/02	mar. 03/02	mer. 04/02	jeu. 05/02
	3	3	3	3	3	3	3

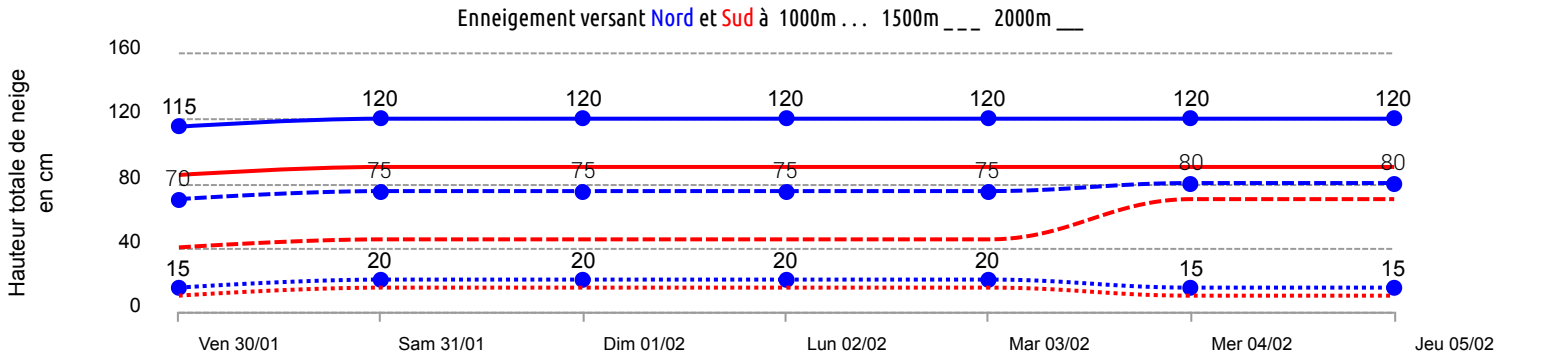

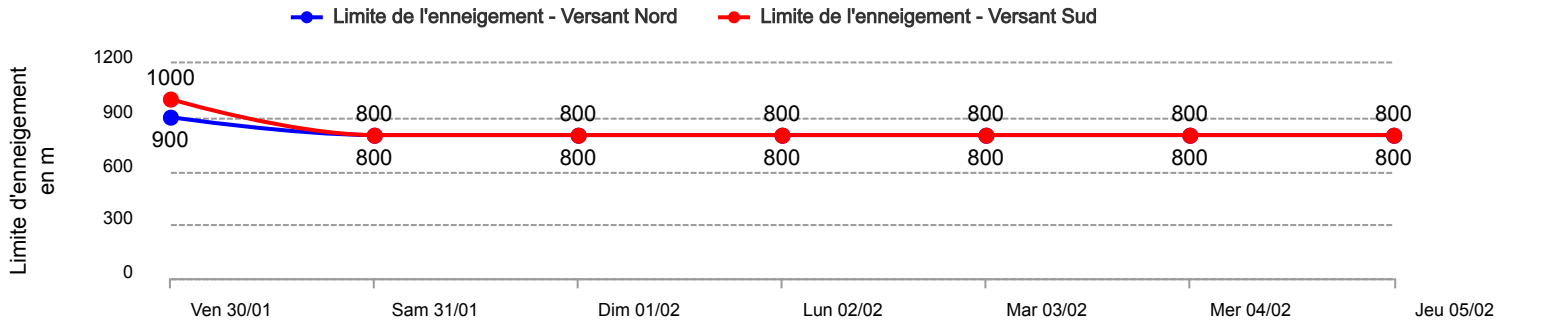

Pour consulter la vigilance en cours, veuillez vous rendre sur le site https://vigilance.meteofrance.fr/fr

Météo-France - 73 avenue de Paris, 94165 Saint-Mandé cedex - Contact : contact@meteo.fr

Rédigé par Météo-France avec la contribution des observateurs du réseau nivo-météorologiques. Partenariat : ANMSM (Maires de Stations de Montagne), DSF (Domaines Skiables de France), ADSP (Directeurs de Pistes et de la Sécurité des Stations de Sports d'Hiver) et autres acteurs de la montagne.

Bulletin neige & avalanches par téléphone au

0 892 68 10 20 Service 0,35 € / min + prix appel