# Bulletin d'estimation du risque d'avalanche

(valable en dehors des pistes balisées et ouvertes)

# MASSIF : Champsaur

Rédigé le jeudi 5 février 2026 à 16h

## Estimation des risques pour le : VENDREDI 06 FÉVRIER

**NOUVELLE CHUTE DE NEIGE SUR UN MANTEAU ÉPAIS ET ENCORE PEU STABILISÉ : SITUATION DÉFAVORABLE**

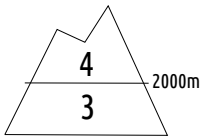


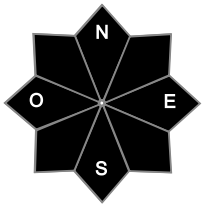


Au-dessus de 2000m indice de risque fort, plus bas indice marqué.

**Départs spontanés :** nombreux pendant les chutes de neige dans la nuit de jeudi à vendredi, occasionnellement de très grande taille

**Déclenchements provoqués :** nombreuses instabilités, facilement déclenchables et très volumineuses

Indices de risque : 5 très fort - 4 fort - 3 marqué - 2 limité - 1 faible -- En noir : les pentes les plus dangereuses

## Stabilité du manteau neigeux

**Situation avalancheuse typique :** neige fraîche couche fragile persistante

**Déclenchements provoqués :** le manteau neigeux est instable dans la plupart des pentes. Au-dessus de 2000 m, ces instabilités, sous forme de plaques souvent d'aspect poudreux, sont nombreuses et concernent toutes les orientations. Un seul skieur isolé peut facilement les déclencher, même à distance, et générer des avalanches de taille moyenne à grande, et possiblement de très grande taille en large secteur nord de haute altitude, si la topographie s'y prête. Ce danger concerne également les pentes a priori peu dangereuses comme celles auparavant skiées, ou en forêts.
La nouvelle chute de neige la nuit de jeudi à vendredi repose sur un manteau neigeux peu stabilisé, souvent constitué d'un empilement de couches fragiles jusqu'au fond, et non détectables depuis la surface ; éventuellement avec un test du bâton, on observe un brusque enfoncement près du sol. Les épaisseurs de cassure peuvent ainsi dépasser 100 cm en versants peu ensoleillés d'altitude.
Sous 2000 m d'altitude, ces instabilités sont moins volumineuses et moins sensibles, mais un seul skieur peut encore les déclencher et générer des avalanches de taille moyenne.

**Départs spontanés** : activité marquée la nuit de jeudi à vendredi pendant les chutes ou peu après. Nombreuses avalanches de neige fraîche ventée, en départs linéaires, avec aérosol, atteignant des dimensions de taille moyenne à grande. Une avalanche de très grande taille n'est pas exclue en versant froid de haute altitude. Ces avalanches pourraient approcher certains secteurs routiers d'altitude, sans toutefois les atteindre.
En journée, activité limitée en neige humide, départs restants ponctuels et de taille petite à moyenne en adrets raides.

## Qualité de la neige

**L'enneigement** est désormais excédentaire pour un début février.
Données observées jeudi : 34 cm au hameau des Portes dans le Valgaudemar à 1270 m, 90 cm à la Nivôse d'Orcières à 2280 m, et 137 cm au-dessus de Prapic à 2480 m.

**Limite d'enneigement skiable :** la plupart des itinéraires sont skiables dès les fonds de vallées vendredi matin.

**État de la neige de surface** : vendredi matin, on trouve partout de la neige fraîche : 5/10 cm humides à 1200 m, 15 à 30 cm vers 1500 m, jusqu'à 40 cm en altitude. Elle est souvent légère et poudreuse, localement densifiée par le vent près des crêtes d'altitude. Cette neige fraîche s'alourdit en adrets raides sous les éclaircies jusque 1800/2000 m environ.

## Aperçu météo pour le vendredi 06 février

| | nuit | matin | après-midi | soir |
|---|---|---|---|---|
| | | | | |
| | Variable, nuageux et rares averses de neige après la chute de la nuit. Frais en altitude, 0°C à 2000 m, -6 à 3000. | | | |
| **Pluie-Neige** | 1 500 m | 1 300 m | 1 400 m | |
| **Iso 0 °C** | 2 000 m | 1 800 m | 1 900 m | 1 800 m |
| **Vent 2000 m** | ↘ 30 km/h | → 40 km/h | → 30 km/h | ↓ 20 km/h |
| **Vent 3000 m** | ↘ 50 km/h | ↘ 50 km/h | ↘ 50 km/h | ↘ 30 km/h |

## Épaisseur de neige hors-piste

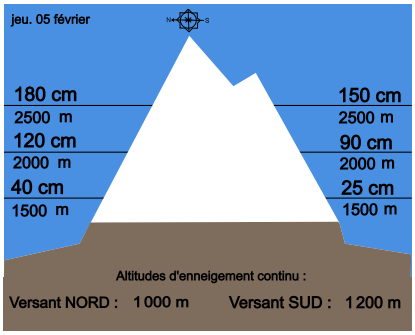


## Précipitations à 1800 m

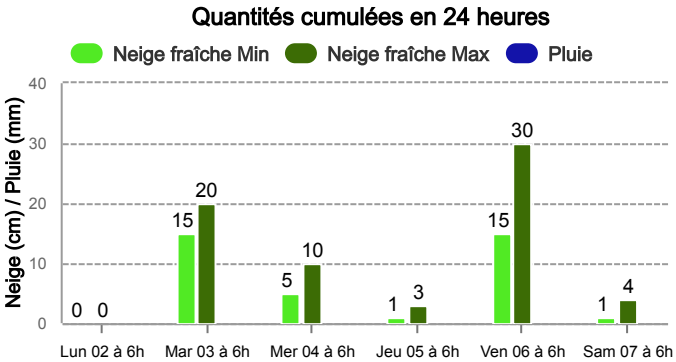


## Tendance du samedi 07 février

**Indice de risque fort**

Persistance de nombreuses instabilités, encore faciles à déclencher et volumineuses. Risque fort.

Pour consulter la vigilance en cours, veuillez vous rendre sur le site https://vigilance.meteofrance.fr/fr

Météo-France - 73 avenue de Paris, 94165 Saint-Mandé cedex - Contact : contact@meteo.fr

Rédigé par Météo-France avec la contribution des observateurs du réseau nivo-météorologiques. Partenariat : ANMSM (Maires de Stations de Montagne), DSF (Domaines Skiables de France), ADSP (Directeurs de Pistes et de la Sécurité des Stations de Sports d'Hiver) et autres acteurs de la montagne.

Bulletin neige & avalanches par téléphone au **0 892 68 10 20** Service 0,35 € / min + prix appel

RÉPUBLIQUE FRANÇAISE
*Liberté Égalité Fraternité*

METEO FRANCE
À VOS CÔTÉS, DANS UN CLIMAT QUI CHANGE

# Bulletin d'estimation du risque d'avalanche

## (valable en dehors des pistes balisées et ouvertes)

# MASSIF : Champsaur

Rédigé le jeudi 5 février 2026 à 16h

## Conditions nivo-météo des 7 derniers jours

| | ven. 30/01 | | | | sam. 31/01 | | | | dim. 01/02 | | | | lun. 02/02 | | | | mar. 03/02 | | | | mer. 04/02 | | | | jeu. 05/02 | | | |
|---|---|---|---|---|---|---|---|---|---|---|---|---|---|---|---|---|---|---|---|---|---|---|---|---|---|---|---|---|
| | 03h | 09h | 15h | 21h | 03h | 09h | 15h | 21h | 03h | 09h | 15h | 21h | 03h | 09h | 15h | 21h | 03h | 09h | 15h | 21h | 03h | 09h | 15h | 21h | 03h | 09h | 15h | 21h |
| Météo | | | | | | | | | | | | | | | | | | | | | | | | | | | | |
| Vent (km/h) | 20 | 30 | 40 | 25 | 20 | 20 | 10 | 10 | 10 | 10 | 25 | 45 | 35 | 25 | 50 | 80 | 100 | 70 | 50 | 35 | 35 | 30 | 20 | 15 | 35 | 30 | 60 | 20 |
| à 3000m | | | | | | | | | | | | | | | | | | | | | | | | | | | | |
| Vent (km/h) | 10 | 20 | 25 | 15 | 10 | 10 | 10 | 10 | 10 | 10 | 15 | 20 | 20 | 10 | 20 | 35 | 50 | 35 | 20 | 15 | 20 | 20 | 15 | 10 | 10 | 10 | 20 | 5 |
| à 2000m | | | | | | | | | | | | | | | | | | | | | | | | | | | | |

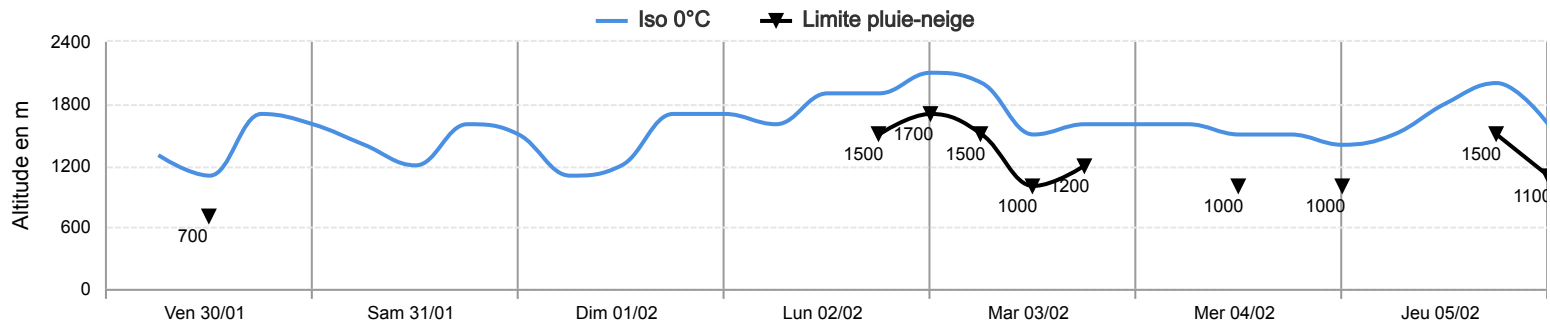


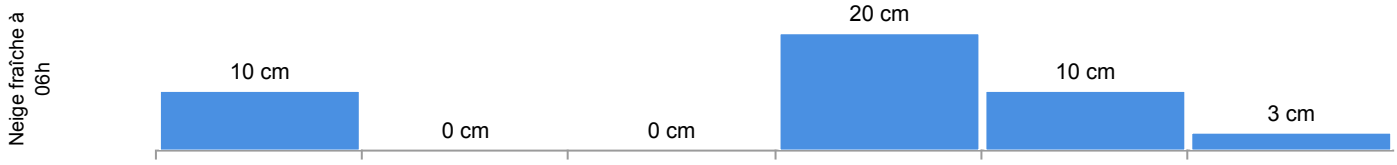


| Risque d'avalanche | | | | | | | |
|---|---|---|---|---|---|---|---|
| | ven. 30/01 | sam. 31/01 | dim. 01/02 | lun. 02/02 | mar. 03/02 | mer. 04/02 | jeu. 05/02 |

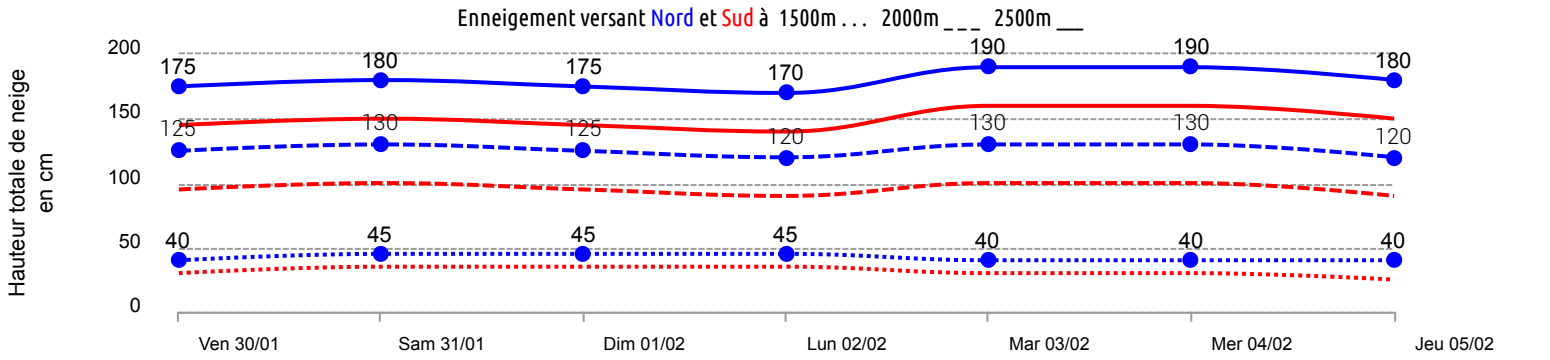


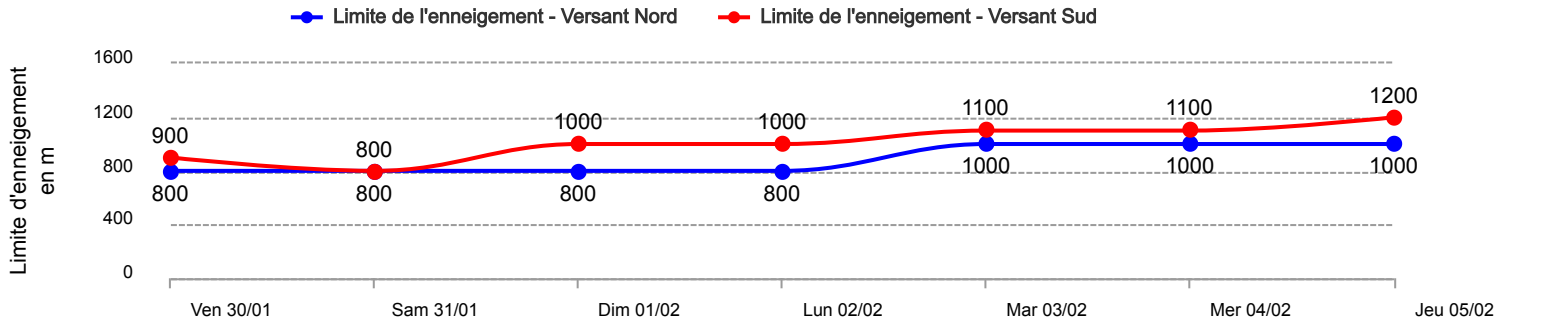


Pour consulter la vigilance en cours, veuillez vous rendre sur le site https://vigilance.meteofrance.fr/fr


Météo-France - 73 avenue de Paris, 94165 Saint-Mandé cedex - Contact : contact@meteo.fr


Bulletin neige & avalanches par téléphone au

0 892 68 10 20 Service 0,35 € / min + prix appel


Rédigé par Météo-France avec la contribution des observateurs du réseau nivo-météorologiques. Partenariat : ANMSM (Maires de Stations de Montagne), DSF (Domaines Skiables de France), ADSP (Directeurs de Pistes et de la Sécurité des Stations de Sports d'Hiver) et autres acteurs de la montagne.