Bulletin d'estimation du risque d'avalanche

(valable en dehors des pistes balisées et ouvertes)

MASSIF : Devoluy

Rédigé le jeudi 5 février 2026 à 16h

Estimation des risques pour le : VENDREDI 06 FÉVRIER

NOUVELLE CHUTE DE NEIGE SUR UN MANTEAU ÉPAIS ET ENCORE PEU STABILISÉ : SITUATION DÉFAVORABLE

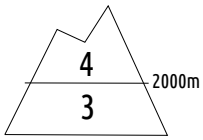

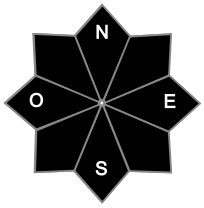

Au-dessus de 2000m indice de risque fort, plus bas indice marqué.

Départs spontanés : nombreux pendant les chutes de neige dans la nuit de jeudi à vendredi, taille moyenne à grande

Déclenchements provoqués : nombreuses instabilités, facilement déclenchables et très volumineuses

Indices de risque : 5 très fort - 4 fort - 3 marqué - 2 limité - 1 faible -- En noir : les pentes les plus dangereuses

Stabilité du manteau neigeux

Situation avalancheuse typique : neige fraîche couche fragile persistante

Déclenchements provoqués : le manteau neigeux est instable dans la plupart des pentes. Au-dessus de 2000 m, ces instabilités, sous forme de plaques souvent d'aspect poudreux, sont nombreuses et concernent toutes les orientations. Un seul skieur isolé peut facilement les déclencher, éventuellement à distance, et générer des avalanches de taille moyenne à grande. Ce danger concerne également les pentes a priori peu dangereuses comme celles auparavant skiées, ou en forêts.
La nouvelle chute de neige la nuit de jeudi à vendredi repose sur un manteau neigeux peu stabilisé, constitué de couches fragiles au fond du manteau, et non détectables depuis la surface ; éventuellement avec un test du bâton, on observe un brusque enfoncement près du sol. Les épaisseurs de cassure peuvent ainsi atteindre 100 cm en versants peu ensoleillés d'altitude.
Sous 2000 m d'altitude, ces instabilités sont moins volumineuses et moins sensibles, mais un seul skieur peut encore les déclencher et générer des avalanches de taille moyenne.

Départs spontanés : activité marquée la nuit de jeudi à vendredi pendant les chutes ou peu après. Nombreuses avalanches de neige fraîche ventée, en départs linéaires, avec aérosol, atteignant des dimensions de taille moyenne à grande.
En journée, activité limitée en neige humide, départs restants ponctuels et de taille petite à moyenne en adrets raides.

Qualité de la neige

L'enneigement est plutôt excédentaire pour un début février.

Limite d'enneigement skiable : vers 1000/1200 m sur la plupart des itinéraires

État de la neige de surface : vendredi matin, on trouve partout de la neige fraîche : 5/10 cm humides à 1200 m, 15 à 30 cm vers 1500 m, jusqu'à 40 cm en altitude. Encore parfois légère et poudreuse, elle est rapidement densifiée par le vent. Cette neige fraîche s'alourdit en adrets raides sous les éclaircies jusque 2000/2200 m environ.

Aperçu météo pour le vendredi 06 février

	nuit	matin	après-midi	soir

Variable, nuageux, averses de neige (plus fréquentes vers le Trièves) après la chute de la nuit. Foid en altitude, -1°C à 2000 m, -5 à 2500.

Pluie-Neige	1 400 m	1 300 m	1 500 m	
Iso 0 °C	1 900 m	1 700 m	1 800 m	1 800 m
Vent 2000 m	↘ 25 km/h	↘ 25 km/h	↘ 25 km/h	↓ 15 km/h
Vent 3000 m	↘ 40 km/h	↘ 45 km/h	↘ 35 km/h	↘ 20 km/h

Épaisseur de neige hors-piste

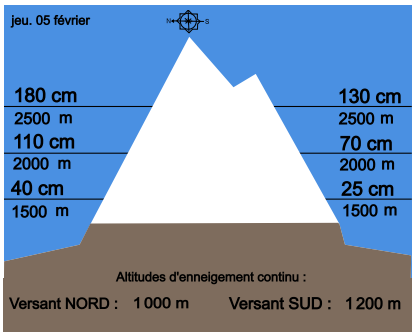

Précipitations à 1800 m

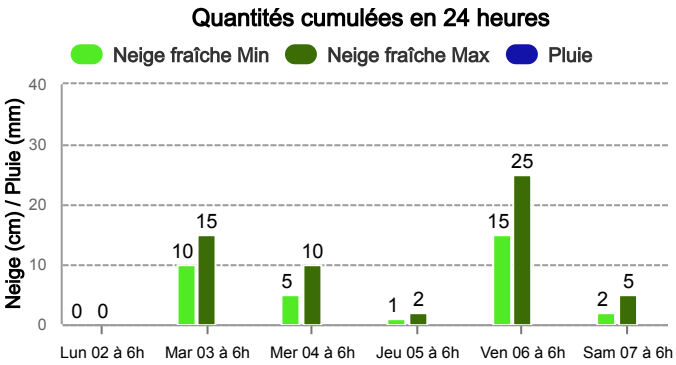

Tendance du samedi 07 février

Indice de risque marqué

Instabilités encore faciles à déclencher et volumineuses. Risque marqué

Pour consulter la vigilance en cours, veuillez vous rendre sur le site https://vigilance.meteofrance.fr/fr

Météo-France - 73 avenue de Paris, 94165 Saint-Mandé cedex - Contact : contact@meteo.fr

Rédigé par Météo-France avec la contribution des observateurs du réseau nivo-météorologiques. Partenariat : ANMSM (Maires de Stations de Montagne), DSF (Domaines Skiables de France), ADSP (Directeurs de Pistes et de la Sécurité des Stations de Sports d'Hiver) et autres acteurs de la montagne.

Bulletin neige & avalanches par téléphone au **0 892 68 10 20** Service 0,35 € / min + prix appel

RÉPUBLIQUE FRANÇAISE
Liberté Égalité Fraternité

METEO FRANCE
À VOS CÔTÉS, DANS UN CLIMAT QUI CHANGE

Bulletin d'estimation du risque d'avalanche
(valable en dehors des pistes balisées et ouvertes)

MASSIF : Devoluy

Rédigé le jeudi 5 février 2026 à 16h

Conditions nivo-météo des 7 derniers jours

	ven. 30/01				sam. 31/01				dim. 01/02				lun. 02/02				mar. 03/02				mer. 04/02				jeu. 05/02			
	03h	09h	15h	21h	03h	09h	15h	21h	03h	09h	15h	21h	03h	09h	15h	21h	03h	09h	15h	21h	03h	09h	15h	21h	03h	09h	15h	21h
Météo																												
Vent (km/h)	35	40	40	25	25	5	5	10	20	20	40	30	35	50	70	100	120	60	50	40	40	40	30	15	30	15	60	40
à 3000m																												
Vent (km/h)	15	30	25	15	15	15	15	10	20	20	15	10	10	25	45	80	70	45	35	35	35	30	20	5	10	20	60	10
à 2000m																												

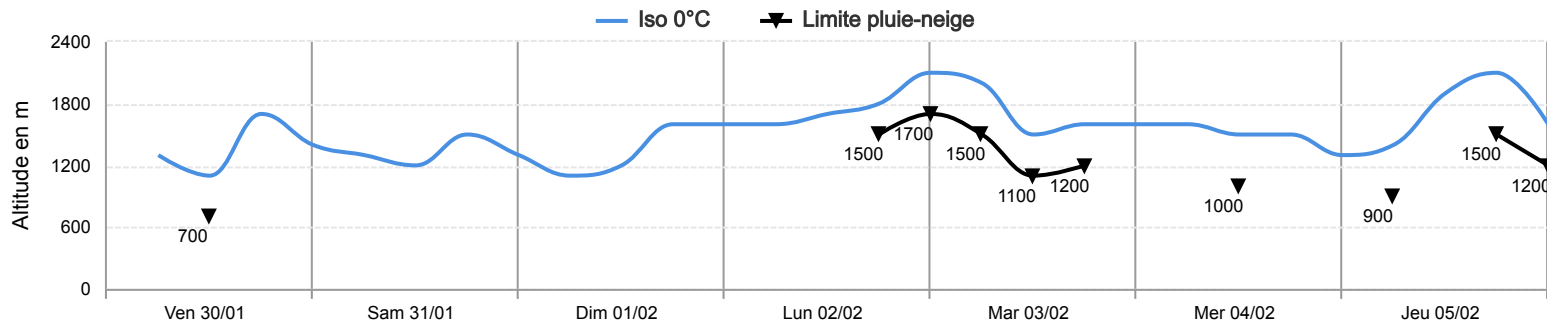

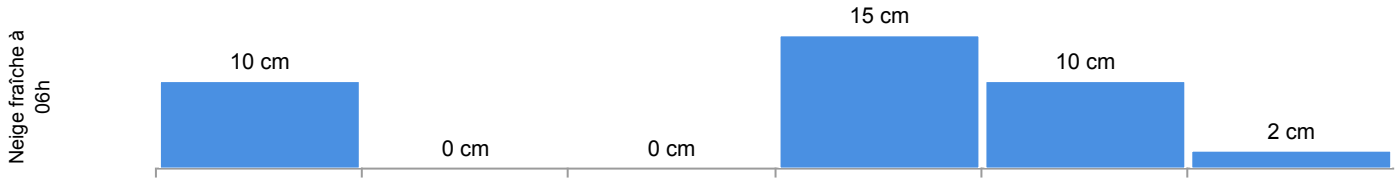

Risque d'avalanche	ven. 30/01	sam. 31/01	dim. 01/02	lun. 02/02	mar. 03/02	mer. 04/02	jeu. 05/02
	4	3	3	3	4	3	3

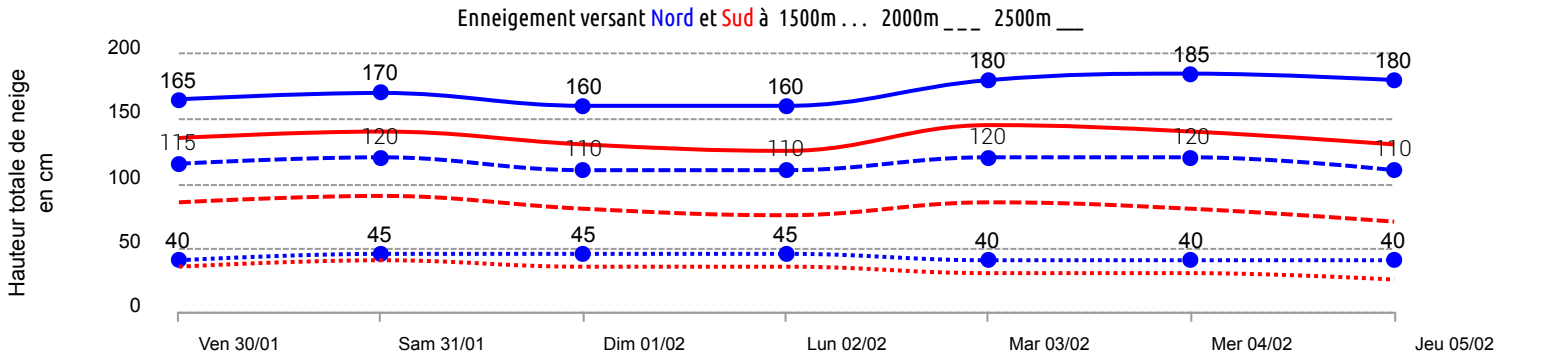

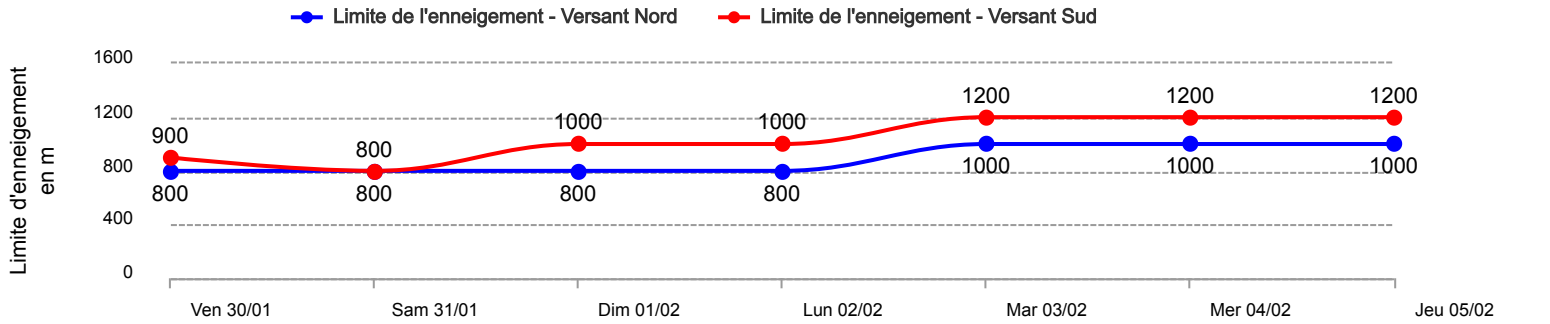

Pour consulter la vigilance en cours, veuillez vous rendre sur le site https://vigilance.meteofrance.fr/fr

Météo-France - 73 avenue de Paris, 94165 Saint-Mandé cedex - Contact : contact@meteo.fr

Bulletin neige & avalanches par téléphone au **0 892 68 10 20** Service 0,35 € / min + prix appel

Rédigé par Météo-France avec la contribution des observateurs du réseau nivo-météorologiques. Partenariat : ANMSM (Maires de Stations de Montagne), DSF (Domaines Skiables de France), ADSP (Directeurs de Pistes et de la Sécurité des Stations de Sports d'Hiver) et autres acteurs de la montagne.