Bulletin d'estimation du risque d'avalanche
(valable en dehors des pistes balisées et ouvertes)

MASSIF : Haute-Maurienne

Rédigé le jeudi 5 février 2026 à 16h

Estimation des risques pour le : VENDREDI 06 FÉVRIER

QUELQUES PLAQUES FRIABLES REPOSANT SUR UN MANTEAU ENCORE GLOBALEMENT INSTABLE.

3

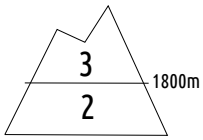

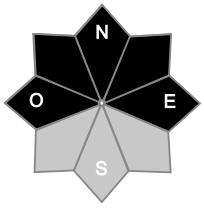

Au-dessus de 1800m indice de risque marqué, plus bas indice limité.

Départs spontanés : rares petits départs de neige fraiche dans les pentes raides

Déclenchements provoqués : quelques plaques dans la neige ventée. Couche fragile persistante dans de nombreuses pentes.

Indices de risque : 5 très fort - 4 fort - 3 marqué - 2 limité - 1 faible -- En noir : les pentes les plus dangereuses

Stabilité du manteau neigeux

Situation avalancheuse typique : couche fragile persistante neige ventée

Déclenchements provoqués :
(1) **Quelques plaques généralement friables** encore en place suite au fort vent de sud des derniers jours. Elles vont se réactiver avec le vent et les petites chutes attendues . On les trouve en tous versants, **plutôt en pied et milieu de pentes**. Tailles 2 (moyennes) avec des cassures très variables, pour une moyenne **de 40-60 cm** d'épaisseur. *Observables : indices de transport, accumulation ferme sous les skis.*
(2) La **couche fragile persistante** (**grains anguleux** semblables à du gros sel)**, enfouie** depuis plusieurs semaine, reste **généralisée dès 1800 m**, dans les pentes **Nord**, **Est** et **Ouest** mais **aussi en Sud à haute altitude**. Elle vient former une épaisse structure de plaque qui, en cas de déclenchement, entraîne l'ensemble du manteau neigeux. Déclenchements de plus en plus rares , provoquant des avalanches de taille 3 (grandes), avec des cassures s'approchant d'1m. *Observables : woumfs, tests CT/ECT pour identifier la couche fragile.*
A fortiori, une première avalanche dans la neige ventée (1) pourrait mobiliser en cascade la couche fragile enfouie (2).

Départs spontanés : Rares petits départs de neige fraiche dans les pentes raides au moment des chutes de neige attendues (5/10 localement 15 cm max de cumul vendredi soir)

Qualité de la neige

Enneigement : tout à fait correct pour la saison.

Limite skiable : à basse altitude sur l'herbe. Sur terrain rocheux, gare à l'absence de sous-couche en dessous de 1500 m en N, 2000 m en Sud.

Qualité de la neige : manteau neigeux partiellement travaillé par le vent. On trouve encore de la neige poudreuse légère dans les secteurs à l'abri, tandis que la neige est souvent raffermie voire durcie par le vent ailleurs. Petit saupoudrage sur croute de regel à basse altitude en versant Sud.

Aperçu météo pour le vendredi 06 février

	nuit	matin	après-midi	soir

Vent fort de sud ce soir. Faible neige cette nuit de jeudi à vendredi, très rares averses en journée avec éclaircies. Vent fort de NW l'après-midi sur frontière

Pluie-Neige	1 400 m	1 400 m		
Iso 0 °C	1 800 m	1 800 m	1 900 m	1 700 m
Vent 2500 m	↘ 20 km/h	→ 30 km/h	↘ 35 km/h	↘ 20 km/h
Vent 3500 m	↑ 30 km/h	↘ 45 km/h	↘ 60 km/h	↘ 45 km/h

Épaisseur de neige hors-piste

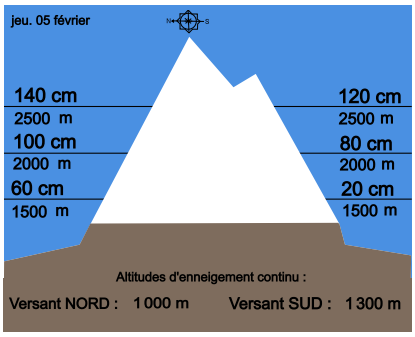

Précipitations à 1800 m

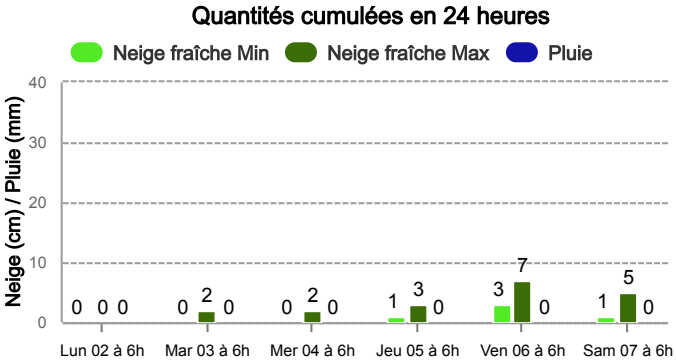

Tendance du samedi 07 février

3 **Indice de risque marqué**

Retour du beau temps voilé, attention au risque accidentel qui va rester marqué dans un certain nombre de pentes surtout en large secteur Nord .

Pour consulter la vigilance en cours, veuillez vous rendre sur le site https://vigilance.meteofrance.fr/fr

Météo-France - 73 avenue de Paris, 94165 Saint-Mandé cedex - Contact : contact@meteo.fr

Rédigé par Météo-France avec la contribution des observateurs du réseau nivo-météorologiques. Partenariat : ANMSM (Maires de Stations de Montagne), DSF (Domaines Skiables de France), ADSP (Directeurs de Pistes et de la Sécurité des Stations de Sports d'Hiver) et autres acteurs de la montagne.

Bulletin neige & avalanches par téléphone au **0 892 68 10 20** Service 0,35 € / min + prix appel

Bulletin d'estimation du risque d'avalanche

(valable en dehors des pistes balisées et ouvertes)

MASSIF : Haute-Maurienne

Rédigé le jeudi 5 février 2026 à 16h

Conditions nivo-météo des 7 derniers jours

	ven. 30/01				sam. 31/01				dim. 01/02				lun. 02/02				mar. 03/02				mer. 04/02				jeu. 05/02			
	03h	09h	15h	21h	03h	09h	15h	21h	03h	09h	15h	21h	03h	09h	15h	21h	03h	09h	15h	21h	03h	09h	15h	21h	03h	09h	15h	21h
Météo																												
Vent (km/h)	35	30	35	20	20	20	20	20	20	20	20	30	30	30	40	50	55	50	40	30	30	30	20	20	20	25	25	20
à 3500m																												
Vent (km/h)	15	20	25	10	10	10	10	10	10	10	10	20	20	20	30	40	45	40	30	20	20	20	10	10	10	15	20	20
à 2500m																												

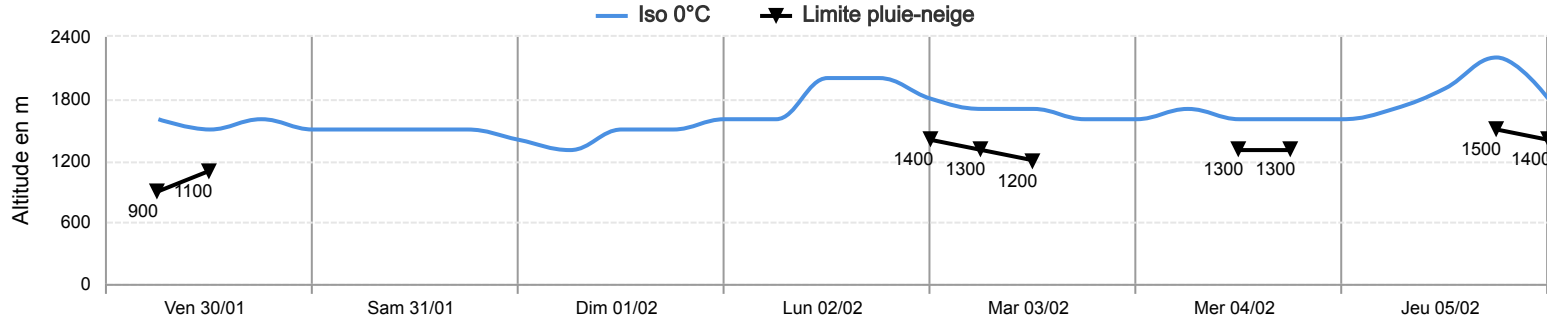

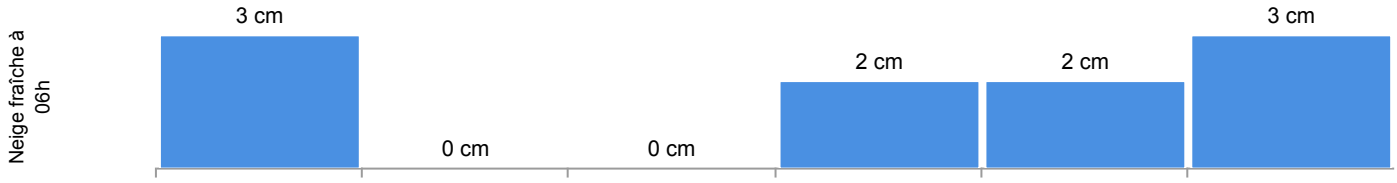

Risque d'avalanche	ven. 30/01	sam. 31/01	dim. 01/02	lun. 02/02	mar. 03/02	mer. 04/02	jeu. 05/02
	3	3	3	3	3	3	3

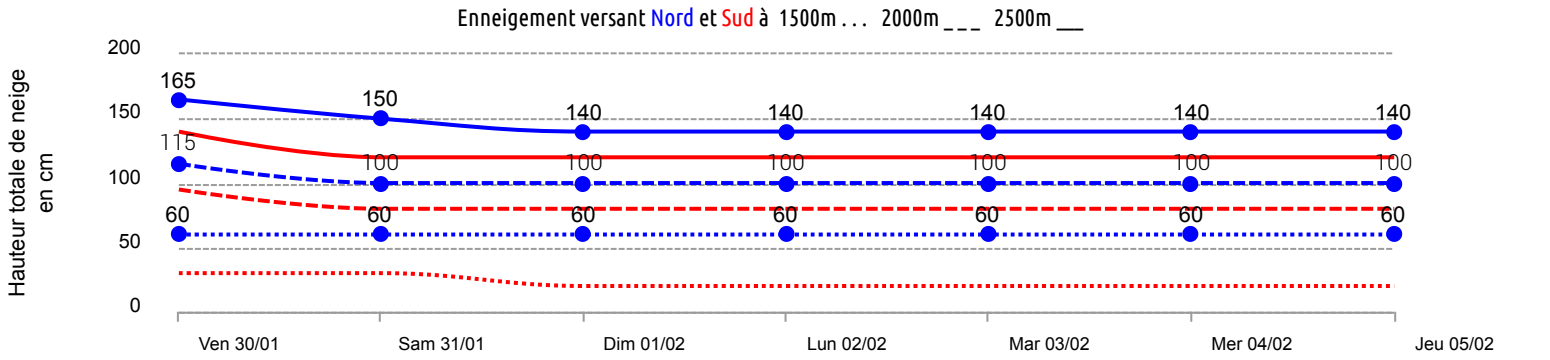

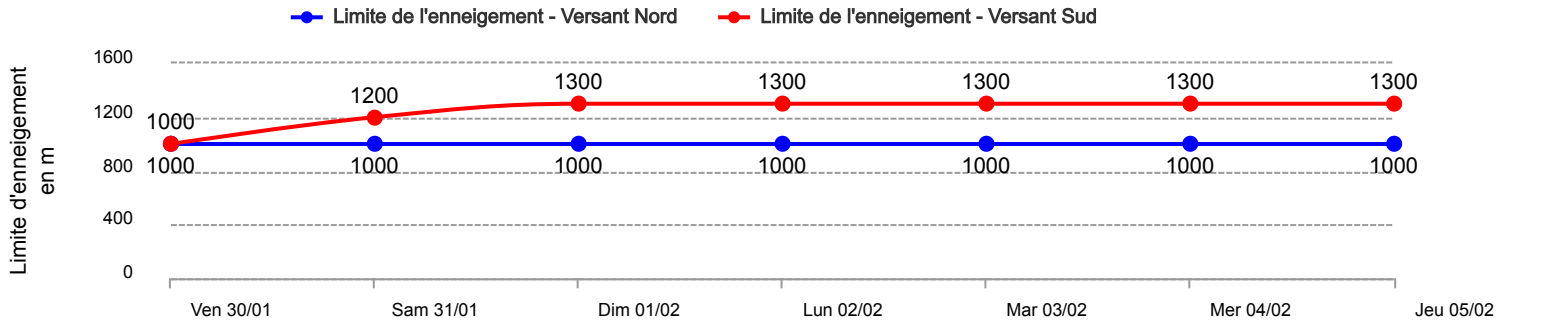

Pour consulter la vigilance en cours, veuillez vous rendre sur le site https://vigilance.meteofrance.fr/fr

Météo-France - 73 avenue de Paris, 94165 Saint-Mandé cedex - Contact : contact@meteo.fr

Rédigé par Météo-France avec la contribution des observateurs du réseau nivo-météorologiques. Partenariat : ANMSM (Maires de Stations de Montagne), DSF (Domaines Skiables de France), ADSP (Directeurs de Pistes et de la Sécurité des Stations de Sports d'Hiver) et autres acteurs de la montagne.

Bulletin neige & avalanches par téléphone au 0 892 68 10 20 Service 0,35 € / min + prix appel