Bulletin d'estimation du risque d'avalanche
(valable en dehors des pistes balisées et ouvertes)

MASSIF : Luchonnais

Rédigé le jeudi 5 février 2026 à 16h

Estimation des risques pour le : VENDREDI 06 FÉVRIER

NEIGE VENTEE EN ALTITUDE, HUMIDIFICATION LENTE PLUS BAS.

3

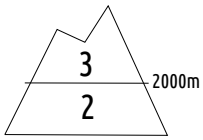

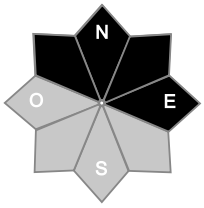

Neige ventée

Au-dessus de 2000m indice de risque marqué, plus bas indice limité.

Départs spontanés : Ponctuels en neige humide, cassures linéaires en neige ventée.

Déclenchements provoqués : Plaques instables au-dessus de 2000m en nord à est.

Indices de risque : 5 très fort - 4 fort - 3 marqué - 2 limité - 1 faible -- En noir : les pentes les plus dangereuses

Stabilité du manteau neigeux

Situation avalancheuse typique : neige ventée neige humide

Déclenchements provoqués : Plaques **formées loin des crêtes, cols et sommets** dans les secteurs déventés Nord-à Est, déclenchables par **faible sollicitation sur le haut du massif. Avalanches possibles de taille 1, très localement de taille 2**.
Mais en secteur frontalier : **Avalanche de taille 3 possible :** si déclenchement d'une plaque initiant une avalanche de taille 2, celle-ci peut entraîner des couches épaisses et anciennes plus difficilement déclenchables en contrebas et **abonder l'avalanche initiale**.
Dans tous les autres secteurs et sous 2000 m, neige moins travaillée par le vent, quelques plaques s'humidifiant en journée, devenant plus difficilement déclenchables.
Manteau humidifié jusqu'à 1900 m jeudi puis quelques plaques formées au-dessus de 1600 m en après-midi en secteurs Nord à Est.

Départs spontanés : départs **peu fréquents et en pentes raides**, se répartissant comme suit :
- **en neige sèche dans les versants Nord à Est** : départs **ponctuels en coulées au-dessus de 1900 à 2100 m**, quelques **cassures linéaires par déclenchement des plaques** décrites ci-dessus par **surcharge avec parfois l'apport supplémentaire de neige transportée par le vent de sud-ouest**, souvent de **petite taille (1)**, mais **quelques-unes de tailles moyennes** en secteurs nord à nord-est déventés en secteur frontalier.
- **en neige humide** : sous 1900/2000m d'altitude et dans tous les autres versants, l'humidification est à l'origine de départs ponctuels de neige alourdie ou d'avalanche de fond de taille 1, rarement 2.

Observables : Plaques moins faciles à identifer en versants Nord à Est.

Qualité de la neige

Enneigement : assez correct pour la saison, mais les crêtes, cols et sommets sont souvent pelés par le vent dans les expositions ouest. Le manteau neigeux s'humidifie en journée sous 2000 m.
Limites skiables : manteau neigeux skiable à partir de 1500 /1600 m avec sous couche portante.
État de la neige : neige récente peu portante, se tassant par le vent en altitude, par l'humidification en journée vendredi sous 2000 m ou au soleil, très frittée près des cols, crêtes et sommets de haute montagne. Peu d'évolution en journée du manteau neigeux en ombrée au-dessus de 2000 m. Partout ailleurs, la neige ramollit et s'humidifie lentement en surface.

Aperçu météo pour le vendredi 06 février

	nuit	matin	après-midi	soir
Pluie-Neige	1 600 m			
Iso 0 °C	2 200 m	1 900 m	2 200 m	2 000 m
Vent 2000 m	50 km/h	55 km/h	45 km/h	30 km/h
Vent 3000 m	70 km/h	70 km/h	60 km/h	50 km/h

Les nuages accrochent le frontalier en matinée, plus dégagé/éclaircies ensuite, quelques flocons en soirée sous des nuages qui reviennent.

Épaisseur de neige hors-piste

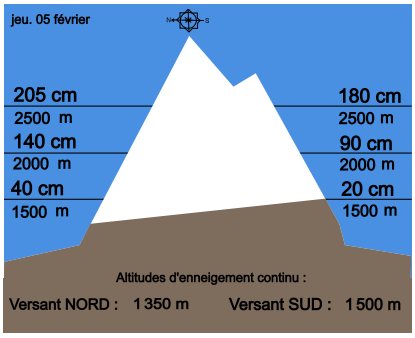

Précipitations à 1800 m

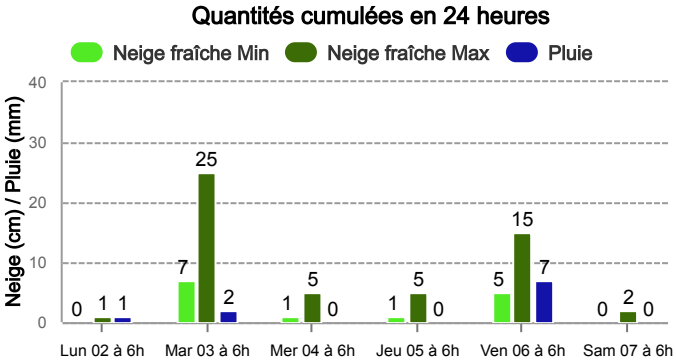

Tendance du samedi 07 février

Indice de risque limité

Humidification des plaques en secteurs ensoleillés, tassement.

Pour consulter la vigilance en cours, veuillez vous rendre sur le site https://vigilance.meteofrance.fr/fr

Météo-France - 73 avenue de Paris, 94165 Saint-Mandé cedex - Contact : contact@meteo.fr

Rédigé par Météo-France avec la contribution des observateurs du réseau nivo-météorologiques. Partenariat : ANMSM (Maires de Stations de Montagne), DSF (Domaines Skiables de France), ADSP (Directeurs de Pistes et de la Sécurité des Stations de Sports d'Hiver) et autres acteurs de la montagne.

Bulletin neige & avalanches par téléphone au **0 892 68 10 20** Service 0,35 € / min + prix appel

RÉPUBLIQUE FRANÇAISE
Liberté Égalité Fraternité

METEO FRANCE
À VOS CÔTÉS, DANS UN CLIMAT QUI CHANGE

Bulletin d'estimation du risque d'avalanche

(valable en dehors des pistes balisées et ouvertes)

MASSIF : Luchonnais

Rédigé le jeudi 5 février 2026 à 16h

Conditions nivo-météo des 7 derniers jours

	ven. 30/01				sam. 31/01				dim. 01/02				lun. 02/02				mar. 03/02				mer. 04/02				jeu. 05/02			
	03h	09h	15h	21h	03h	09h	15h	21h	03h	09h	15h	21h	03h	09h	15h	21h	03h	09h	15h	21h	03h	09h	15h	21h	03h	09h	15h	21h
Météo																												
Vent (km/h)	100	90	60	90	100	100	100	70	40	40	45	50	70	125	120	80	55	45	40	90	95	100	60	55	75	130	95	70
à 3000m																												
Vent (km/h)	45	35	15	40	60	60	70	40	20	20	20	35	50	95	95	50	35	40	30	60	70	55	25	25	55	100	75	55
à 2000m																												

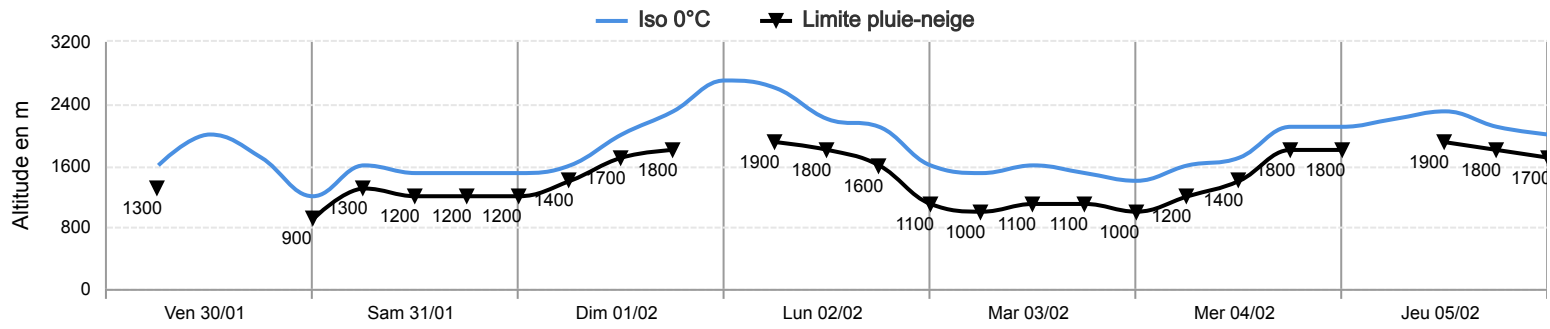

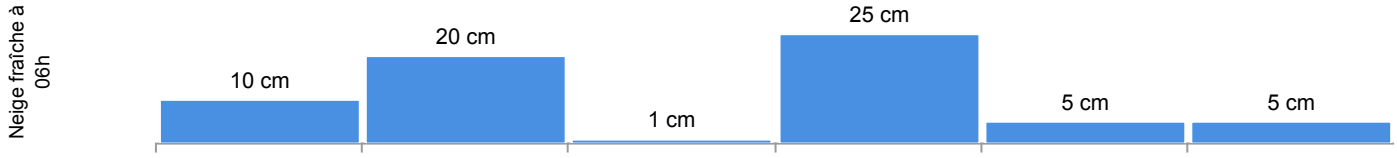

Risque d'avalanche	ven. 30/01	sam. 31/01	dim. 01/02	lun. 02/02	mar. 03/02	mer. 04/02	jeu. 05/02
	3	4	4	3	3	3	3

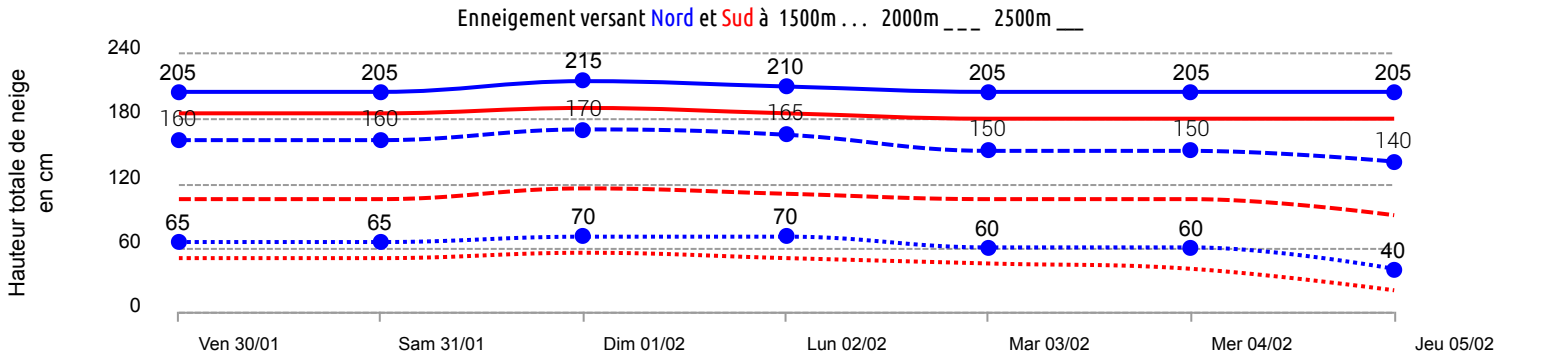

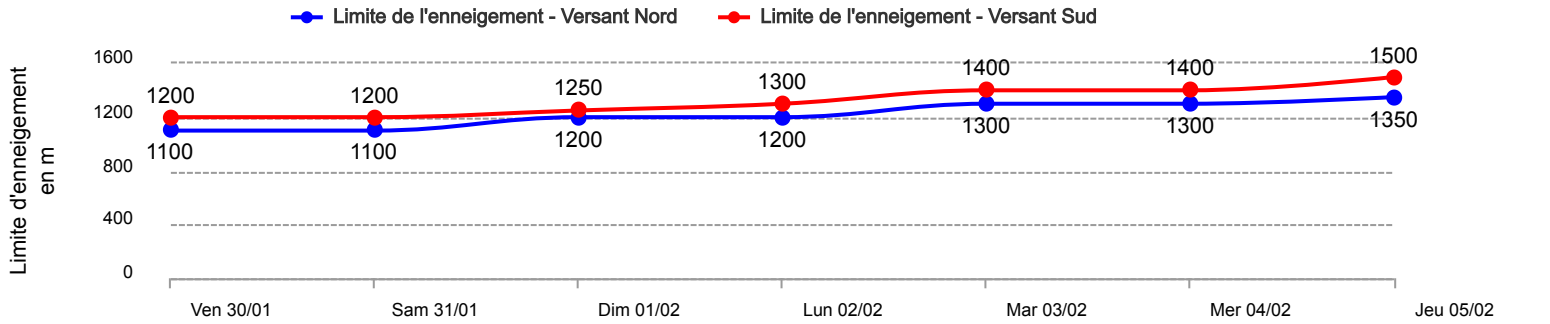

Pour consulter la vigilance en cours, veuillez vous rendre sur le site https://vigilance.meteofrance.fr/fr

Météo-France - 73 avenue de Paris, 94165 Saint-Mandé cedex - Contact : contact@meteo.fr

Rédigé par Météo-France avec la contribution des observateurs du réseau nivo-météorologiques. Partenariat : ANMSM (Maires de Stations de Montagne), DSF (Domaines Skiables de France), ADSP (Directeurs de Pistes et de la Sécurité des Stations de Sports d'Hiver) et autres acteurs de la montagne.

Bulletin neige & avalanches par téléphone au
0 892 68 10 20 Service 0,35 € / min + prix appel