Bulletin d'estimation du risque d'avalanche

(valable en dehors des pistes balisées et ouvertes)

MASSIF : Orlu St-Barthelemy

Rédigé le jeudi 5 février 2026 à 16h

Estimation des risques pour le : VENDREDI 06 FÉVRIER

PERSISTANCE DE QUELQUES INSTABILITÉS

2

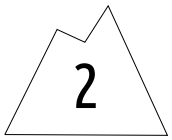

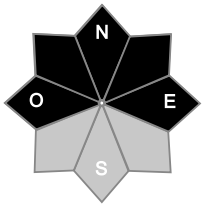

Indice de risque limité.

Départs spontanés : En neige humide

Déclenchements provoqués : plaques à vent secteurs expo au vent de sud, sous couches fragiles persistantes possibles localement en haute montagne

Indices de risque : 5 très fort - 4 fort - 3 marqué - 2 limité - 1 faible -- En noir : les pentes les plus dangereuses

Stabilité du manteau neigeux

Situation avalancheuse typique : couche fragile persistante neige humide

Déclenchements provoqués :

*En haute montagne, quelques anciennes structures de plaques avec sous-couches fragiles persistantes sont encore possible en secteurs ombragés (observables : neige sèche en surface, bruits d'effondrement au sein du manteau neigeux ou fissures au passage d'un randonneur). Elles sont néanmoins difficile à solliciter car profondément enfouies par les chutes de neige des dernières semaines, hormis éventuellement en abord de couloir ou de ruptures de pente. Elles pourront donner lieu à des avalanches de taille 2 à 3.

*Formation ponctuelle de plaques à vent dures sous le vent de sud ce jeudi près des crêtes d'Orlu/Bésines, dans une moindre mesure dans le massif de Tabe (observables : neige sèche ridée par le vent, accumulation récente).

Avalanches possibles de taille 1 ou 2 (moyenne), éventuellement 3 en haute montagne

*En dessous de 2000m, là où croûtes de regel et neige bien humidifiée prédominent en surface, le risque de départ accidentel est plus faible.

Départs spontanés :

Nouvelle humidification en journée dans les pentes raides/couloirs ensoleillés et en dessous de 2000m avec des départs linéaires ou ponctuels (Taille 1 à 2).

Avalanches de glissements possibles en pentes herbeuses ou sur des dalles rocheuses en toutes orientations (Taille 1 ou 2). (Observables : gueules de baleine, reptations)

Qualité de la neige

Enneigement :

Malgré le redoux, l'enneigement reste excellent et excédentaire pour la saison.

Limite d'enneigement skiable remontant toutefois vers 1200/1300 m dans les meilleures configurations.

La fonte va continuer à basse altitude en cours de journée.

État de la neige :

En matinée, neige dure ou croutée à basse et moyenne altitude. Neige encore sèche ou froide au-delà de 2000/2100, avec quelques cm tombés en fin de journée de jeudi. Neige souvent dure et regelée sur les crêtes.

Re-humidification jusque vers 2100/2200m en cours de journée, mais limitée aux versants raides ensoleillés.

Aperçu météo pour le vendredi 06 février

	nuit	matin	après-midi	soir
Belle journée ensoleillée				
Pluie-Neige	1 700 m			
Iso 0 °C	2 000 m	1 900 m	2 100 m	2 100 m
Vent 2000 m	35 km/h	15 km/h	15 km/h	25 km/h
Vent 3000 m	50 km/h	40 km/h	50 km/h	25 km/h

Épaisseur de neige hors-piste

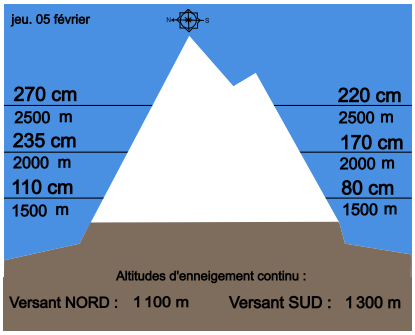

Précipitations à 1800 m

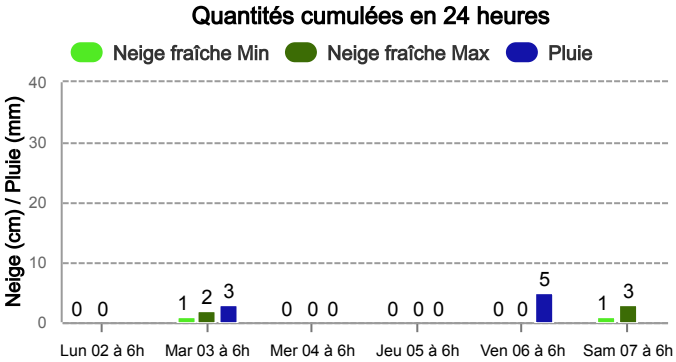

Tendance du samedi 07 février

2

Indice de risque limité

Maintien d'un risque limité, en attendant les prochaines précipitations significatives.

Pour consulter la vigilance en cours, veuillez vous rendre sur le site https://vigilance.meteofrance.fr/fr

Météo-France - 73 avenue de Paris, 94165 Saint-Mandé cedex - Contact : contact@meteo.fr

Rédigé par Météo-France avec la contribution des observateurs du réseau nivo-météorologiques. Partenariat : ANMSM (Maires de Stations de Montagne), DSF (Domaines Skiables de France), ADSP (Directeurs de Pistes et de la Sécurité des Stations de Sports d'Hiver) et autres acteurs de la montagne.

Bulletin neige & avalanches par téléphone au

0 892 68 10 20 Service 0,35 € / min + prix appel

RÉPUBLIQUE FRANÇAISE
Liberté Égalité Fraternité

METEO FRANCE
À VOS CÔTÉS, DANS UN CLIMAT QUI CHANGE

Bulletin d'estimation du risque d'avalanche

(valable en dehors des pistes balisées et ouvertes)

MASSIF : Orlu St-Barthelemy

Rédigé le jeudi 5 février 2026 à 16h

Conditions nivo-météo des 7 derniers jours

	ven. 30/01				sam. 31/01				dim. 01/02				lun. 02/02				mar. 03/02				mer. 04/02				jeu. 05/02			
	03h	09h	15h	21h	03h	09h	15h	21h	03h	09h	15h	21h	03h	09h	15h	21h	03h	09h	15h	21h	03h	09h	15h	21h	03h	09h	15h	21h
Météo																												
Vent (km/h)	80	70	60	40	65	75	80	70	60	40	30	30	45	70	100	70	60	35	40	30	40	65	55	45	50	55	60	55
à 3000m																												
Vent (km/h)	55	45	45	25	35	55	55	50	40	25	20	15	20	45	75	50	40	25	25	20	30	50	45	30	30	40	45	40
à 2000m																												

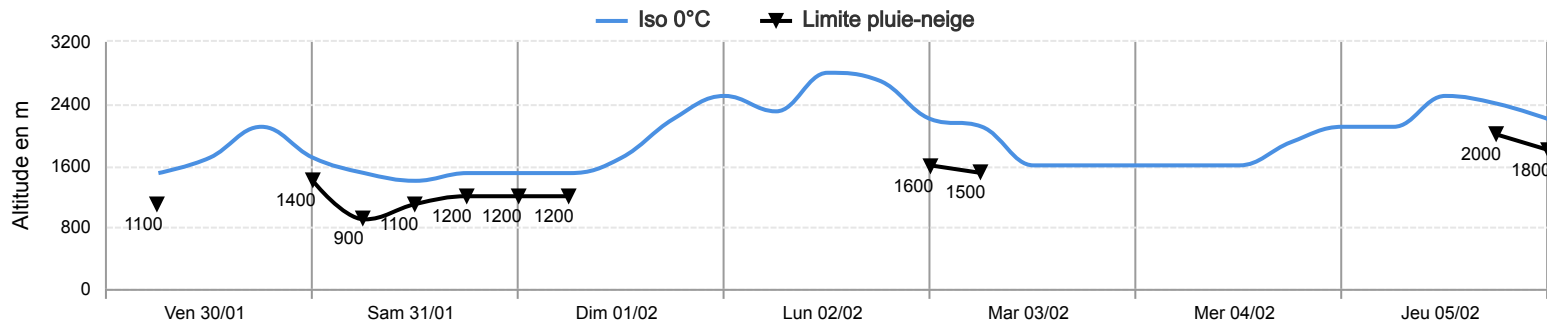

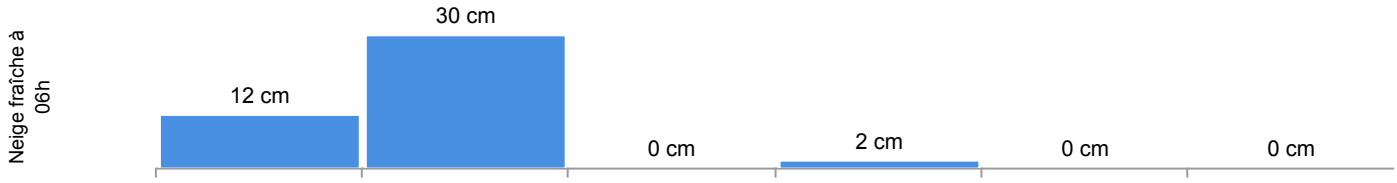

Risque d'avalanche	ven. 30/01	sam. 31/01	dim. 01/02	lun. 02/02	mar. 03/02	mer. 04/02	jeu. 05/02
	3	4	4	3	3	3	3

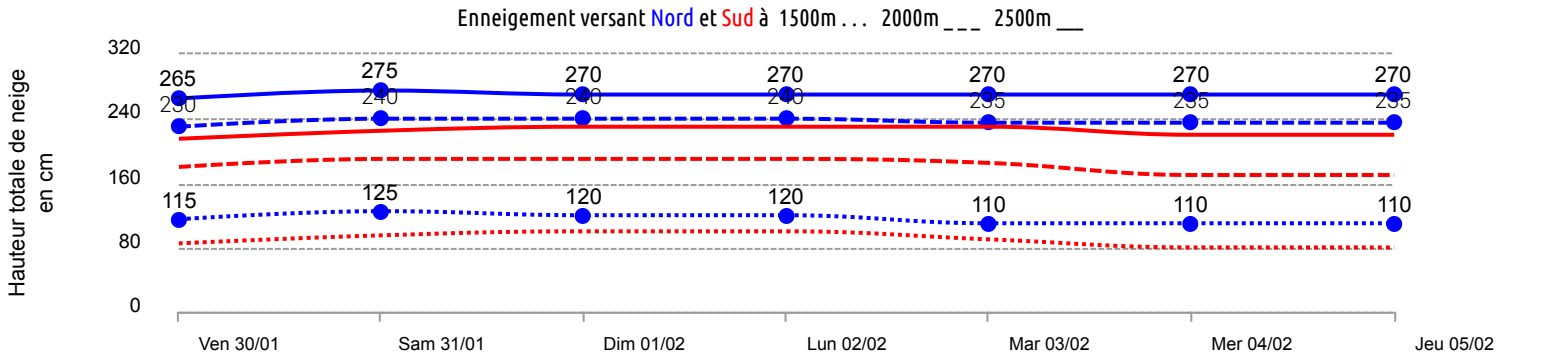

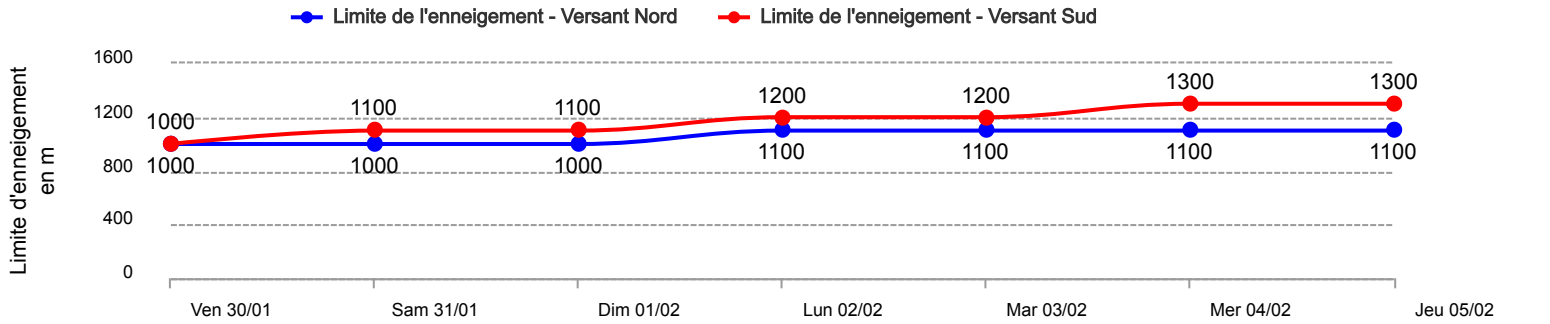

Pour consulter la vigilance en cours, veuillez vous rendre sur le site https://vigilance.meteofrance.fr/fr

Météo-France - 73 avenue de Paris, 94165 Saint-Mandé cedex - Contact : contact@meteo.fr

Rédigé par Météo-France avec la contribution des observateurs du réseau nivo-météorologiques. Partenariat : ANMSM (Maires de Stations de Montagne), DSF (Domaines Skiables de France), ADSP (Directeurs de Pistes et de la Sécurité des Stations de Sports d'Hiver) et autres acteurs de la montagne.

Bulletin neige & avalanches par téléphone au
0 892 68 10 20 Service 0,35 € / min + prix appel