Bulletin d'estimation du risque d'avalanche

(valable en dehors des pistes balisées et ouvertes)

MASSIF : Pays-Basque

Rédigé le jeudi 5 février 2026 à 16h

Estimation des risques pour le : VENDREDI 06 FÉVRIER

QUELQUES PLAQUES SUR MANTEAU HUMIDE

2

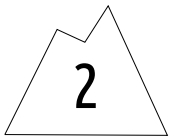

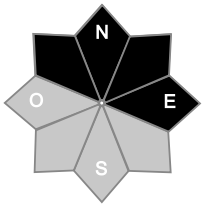

Indice de risque limité.

Départs spontanés : Ponctuels en neige humide, rares cassures linéaires en neige ventée.

Déclenchements provoqués : Plaques peu épaisses en nord à est au-dessus de 1700 m.

Indices de risque : 5 très fort - 4 fort - 3 marqué - 2 limité - 1 faible -- En noir : les pentes les plus dangereuses

Stabilité du manteau neigeux

Situation avalancheuse typique : neige ventée neige humide

Déclenchements provoqués : Manteau humidifié jusqu'à 2000 m puis quelques plaques formées au-dessus de 1600 m ce jeudi : Plaques déclenchables par **faible sollicitation dans les pentes nord à est sur le haut du massif**. Avec le vent fort, ces plaques se sont **formées loin des crêtes, cols et sommets** dans les secteurs déventés, **Avalanche possible de taille 1, très localement de taille 2**.
Dans tous les autres secteurs et plus bas, neige très travaillée par le vent, quelques plaques s'humidifiant en journée, devenant rapidement difficilement déclenchables.

Départs spontanés : **peu fréquents et en pentes raides**, se répartissant comme suit :
- **en neige sèche dans les versants nord à est** : départs **ponctuels de coulées ou petites avalanches partant d'une petite accumulation de neige sèche au plus haut du massif**, quelques **cassures linéaires par déclenchement des plaques** décrites ci-dessus par **surcharge avec l'apport supplémentaire de neige transportée par le vent**, souvent de **petite taille**, **très localement de taille moyenne en partant d'une accumulation un peu plus importante** en secteur Nord-à Est
- **en neige humide** : l'humidification est à l'origine de départs ponctuels de neige alourdie plus fréquents sous 2000 m, quelques avalanches de glissement sur l"herbe..

Qualité de la neige

Enneigement : assez bon pour la saison, mais les crêtes, cols et sommets sont souvent pelés par le vent dans les expositions ouest. La neige fraîche au sol s'humidifie en journée sous 2000 m.
Limites skiables : manteau neigeux skiable à partir de 1600 /1700 m avec sous-couche portante.
État de la neige : Neige non croutée au matin ou alors plaques non portantes. Neige ventée déposée sur un manteau humidifié et tassé, tendance à l'humidification de la neige récente en pentes ensoleillées ou en nord sous 2000 m.

Aperçu météo pour le vendredi 06 février

	nuit	matin	après-midi	soir

Les nuages accrochent le frontalier en matinée, plus dégagé/éclaircies ensuite, quelques flocons en soirée sous des nuages qui reviennent.

	nuit	matin	après-midi	soir
Pluie-Neige	1 600 m		1 500 m	1 500 m
Iso 0 °C	1 800 m	2 000 m	1 900 m	1 700 m
Vent 1000 m	↗ 55 km/h	↗ 55 km/h	↑ 45 km/h	↑ 50 km/h
Vent 2000 m	↗ 85 km/h	↗ 70 km/h	↗ 60 km/h	↗ 65 km/h

Épaisseur de neige hors-piste

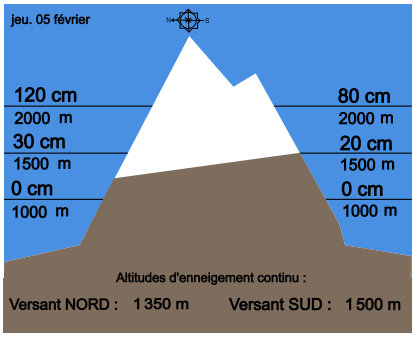

Précipitations à 1800 m

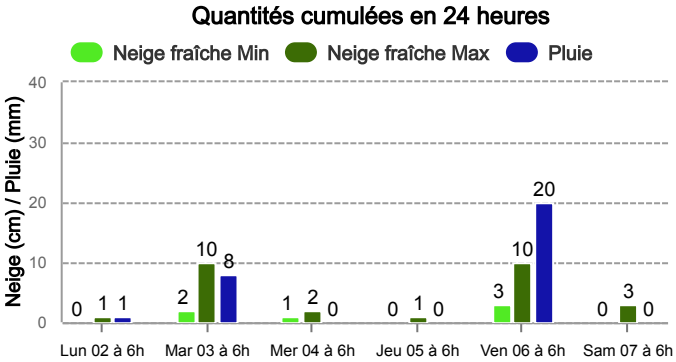

Tendance du samedi 07 février

2

Indice de risque limité

Stabilisation progressive par humidification.

Pour consulter la vigilance en cours, veuillez vous rendre sur le site https://vigilance.meteofrance.fr/fr

Météo-France - 73 avenue de Paris, 94165 Saint-Mandé cedex - Contact : contact@meteo.fr

Rédigé par Météo-France avec la contribution des observateurs du réseau nivo-météorologiques. Partenariat : ANMSM (Maires de Stations de Montagne), DSF (Domaines Skiables de France), ADSP (Directeurs de Pistes et de la Sécurité des Stations de Sports d'Hiver) et autres acteurs de la montagne.

Bulletin neige & avalanches par téléphone au **0 892 68 10 20** Service 0,35 € / min + prix appel

RÉPUBLIQUE FRANÇAISE
Liberté Égalité Fraternité

METEO FRANCE
À VOS CÔTÉS, DANS UN CLIMAT QUI CHANGE

Bulletin d'estimation du risque d'avalanche
(valable en dehors des pistes balisées et ouvertes)
MASSIF : Pays-Basque

Rédigé le jeudi 5 février 2026 à 16h

Conditions nivo-météo des 7 derniers jours

	ven. 30/01				sam. 31/01				dim. 01/02				lun. 02/02				mar. 03/02				mer. 04/02				jeu. 05/02			
	03h	09h	15h	21h	03h	09h	15h	21h	03h	09h	15h	21h	03h	09h	15h	21h	03h	09h	15h	21h	03h	09h	15h	21h	03h	09h	15h	21h
Météo																												
Vent (km/h)	80	95	65	80	70	90	90	60	70	45	50	80	95	120	120	80	80	80	65	80	100	85	65	70	90	130	90	80
à 2000m	↗	↗	↗	↗	↑	→	↘	↘	↘	↗	↗	↑	↑	↑	↑	↗	↗	↑	↑	↑	↑	↗	→	↗	↑	↑	↑	↗
Vent (km/h)	50	65	40	50	50	70	70	35	30	30	40	60	60	90	90	55	55	55	40	45	50	40	45	60	80	90	65	60
à 1000m	↗	↑	↑	→	→	→	→	→	→	↑	↑	↑	↑	↑	↑	↗	↑	↑	↑	↑	↑	↑	↑	↑	↑	↑	↗	↗

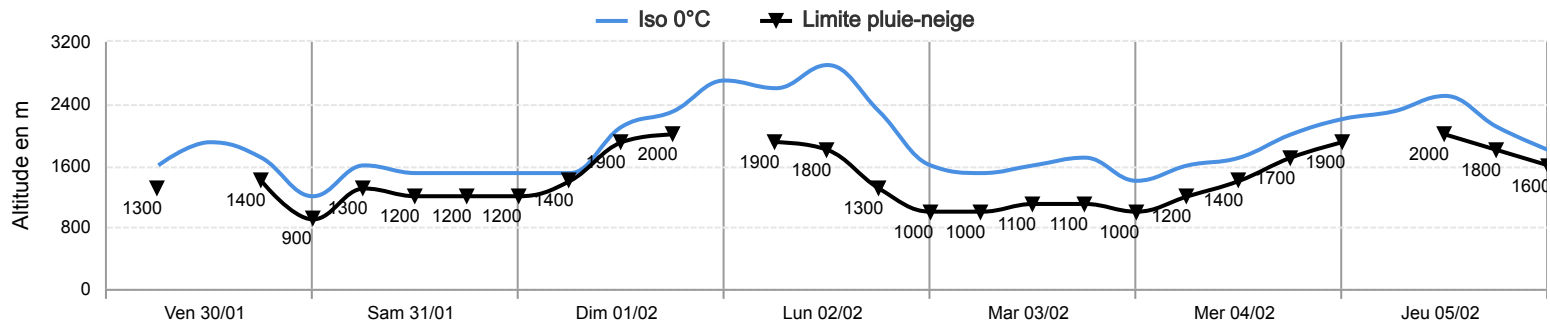

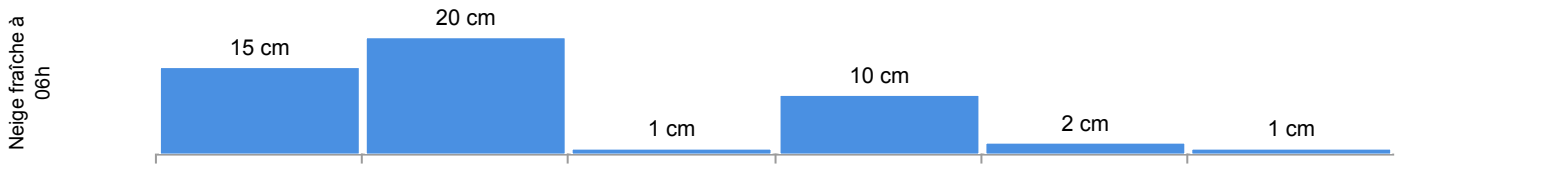

Risque d'avalanche	ven. 30/01	sam. 31/01	dim. 01/02	lun. 02/02	mar. 03/02	mer. 04/02	jeu. 05/02
	3	4	3	3	2	2	2

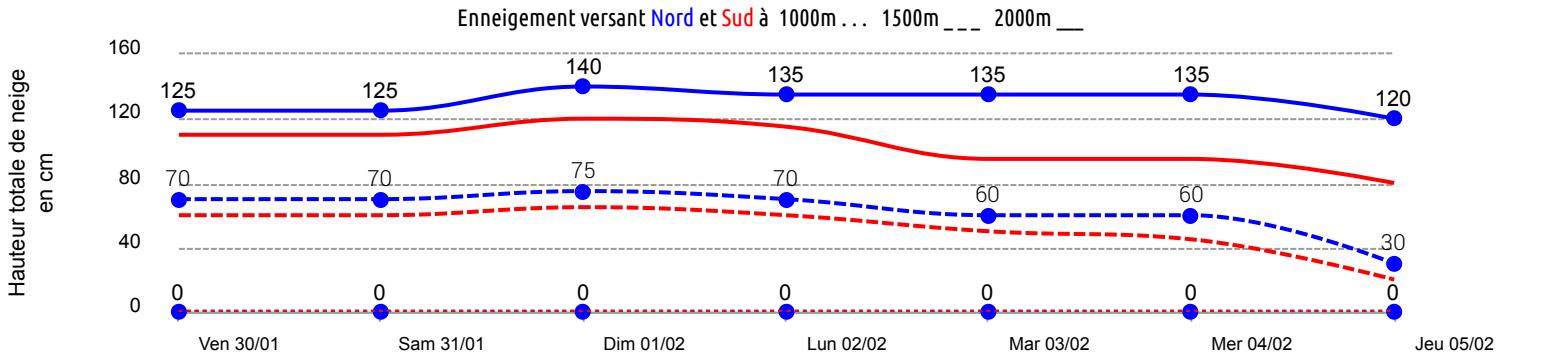

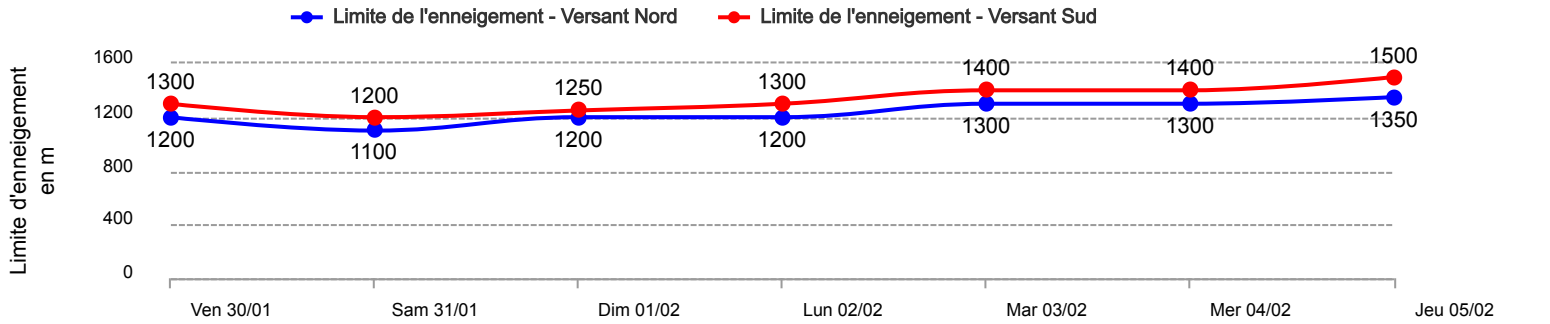

Pour consulter la vigilance en cours, veuillez vous rendre sur le site https://vigilance.meteofrance.fr/fr

Météo-France - 73 avenue de Paris, 94165 Saint-Mandé cedex - Contact : contact@meteo.fr

Rédigé par Météo-France avec la contribution des observateurs du réseau nivo-météorologiques. Partenariat : ANMSM (Maires de Stations de Montagne), DSF (Domaines Skiables de France), ADSP (Directeurs de Pistes et de la Sécurité des Stations de Sports d'Hiver) et autres acteurs de la montagne.

Bulletin neige & avalanches par téléphone au
0 892 68 10 20 Service 0,35 € / min + prix appel