Bulletin d'estimation du risque d'avalanche

(valable en dehors des pistes balisées et ouvertes)

MASSIF : Pelvoux

Rédigé le jeudi 5 février 2026 à 16h

Estimation des risques pour le : VENDREDI 06 FÉVRIER

NOUVELLE CHUTE DE NEIGE SUR UN MANTEAU A LA FOIS ÉPAIS ET FRAGILE : SITUATION TRÈS DÉFAVORABLE

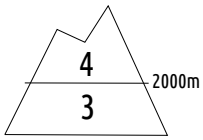

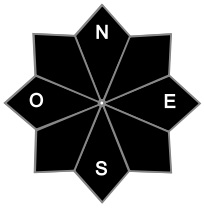

Au-dessus de 2000m indice de risque fort, plus bas indice marqué.

Départs spontanés : nombreux pendant les chutes de neige dans la nuit de jeudi à vendredi, occasionnellement de très grande taille

Déclenchements provoqués : très nombreuses instabilités, facilement déclenchables et très volumineuses

Indices de risque : 5 très fort - 4 fort - 3 marqué - 2 limité - 1 faible -- En noir : les pentes les plus dangereuses

Stabilité du manteau neigeux

Situation avalancheuse typique : neige fraîche couche fragile persistante

Déclenchements provoqués : le manteau neigeux est instable dans la plupart des pentes. Au-dessus de 2000 m, ces instabilités, sous forme de plaques d'aspect poudreux, sont très nombreuses et concernent toutes les orientations. Un seul skieur isolé peut facilement les déclencher, même à distance, et générer des avalanches de taille moyenne à grande, et possiblement de très grande taille en large secteur nord de haute altitude, si la topographie s'y prête. Ce danger concerne également les pentes a priori peu dangereuses comme celles auparavant skiées, ou en forêts.
La nouvelle chute de neige la nuit de jeudi à vendredi repose sur un manteau neigeux instable, constitué d'un empilement de couches fragiles jusqu'au fond, et non détectables depuis la surface. Les épaisseurs de cassure peuvent ainsi dépasser 100 cm en versants peu ensoleillés d'altitude.
Sous 2000 m d'altitude, ces instabilités sont moins volumineuses et moins sensibles, mais un seul skieur peut encore les déclencher et générer des avalanches de taille moyenne, rarement grande.

Départs spontanés : activité marquée la nuit de jeudi à vendredi pendant les chutes ou peu après. Nombreuses avalanches de neige fraîche ventée, en départs linéaires, avec aérosol, atteignant des dimensions de taille moyenne à grande. Une avalanche de très grande taille n'est pas exclue en versant froid de haute altitude. Ces avalanches pourraient approcher certains secteurs routiers d'altitude, sans toutefois les atteindre.
En journée, activité limitée en neige humide, départs restants ponctuels et de taille petite à moyenne en adrets raides.

Qualité de la neige

L'enneigement est désormais excédentaire pour un début février.
Données observées jeudi : 169 cm à la Nivôse de Écrins vers 3000 m, 169 cm au Pré de Madame Carle à 1900 m, 109 cm au hameau de Dormillouse à 1730 m.

Limite d'enneigement skiable : la plupart des itinéraires sont skiables dès les fonds de vallées vendredi matin.

État de la neige de surface : vendredi matin, on trouve partout de la neige fraîche : 15 à 30 cm en vallées, jusqu'à 40 cm en altitude. Elle est souvent légère et poudreuse, localement densifiée par le vent près des crêtes d'altitude. Cette neige fraîche s'alourdit en adrets raides sous les éclaircies jusque 2000/2200 m environ.

Aperçu météo pour le vendredi 06 février

	nuit	matin	après-midi	soir

Variable, nuageux et faibles averses de neige après la chute de la nuit. Frais en altitude, maxi 2°C à 2000 m, -6 à 3000.

Pluie-Neige	1 200 m	1 300 m		
Iso 0 °C	1 700 m	1 800 m	1 900 m	1 800 m
Vent 2000 m	↙ 5 km/h	↘ 10 km/h	→ 15 km/h	↘ 10 km/h
Vent 3000 m	↘ 25 km/h	→ 30 km/h	→ 25 km/h	↘ 20 km/h

Épaisseur de neige hors-piste

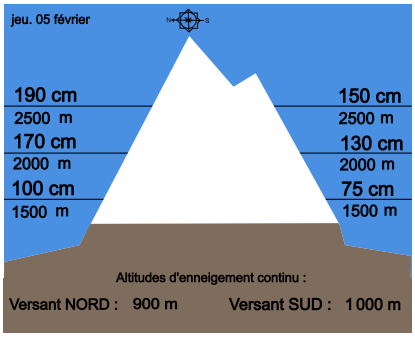

Précipitations à 1800 m

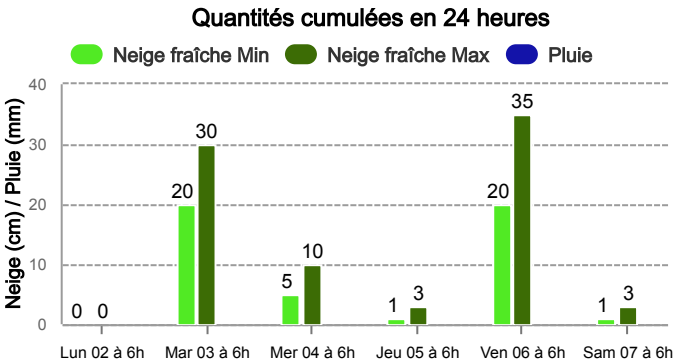

Tendance du samedi 07 février

Indice de risque fort

Persistance de nombreuses instabilités, encore faciles à déclencher et volumineuses. Risque fort.

Pour consulter la vigilance en cours, veuillez vous rendre sur le site https://vigilance.meteofrance.fr/fr

Météo-France - 73 avenue de Paris, 94165 Saint-Mandé cedex - Contact : contact@meteo.fr

Rédigé par Météo-France avec la contribution des observateurs du réseau nivo-météorologiques. Partenariat : ANMSM (Maires de Stations de Montagne), DSF (Domaines Skiables de France), ADSP (Directeurs de Pistes et de la Sécurité des Stations de Sports d'Hiver) et autres acteurs de la montagne.

Bulletin neige & avalanches par téléphone au **0 892 68 10 20** Service 0,35 € / min + prix appel

Bulletin d'estimation du risque d'avalanche

(valable en dehors des pistes balisées et ouvertes)

MASSIF : Pelvoux

Rédigé le jeudi 5 février 2026 à 16h

Conditions nivo-météo des 7 derniers jours

	ven. 30/01				sam. 31/01				dim. 01/02				lun. 02/02				mar. 03/02				mer. 04/02				jeu. 05/02			
	03h	09h	15h	21h	03h	09h	15h	21h	03h	09h	15h	21h	03h	09h	15h	21h	03h	09h	15h	21h	03h	09h	15h	21h	03h	09h	15h	21h
Météo																												
Vent (km/h)	20	25	30	10	15	15	5	10	10	10	15	15	20	25	40	60	100	70	40	30	30	30	20	15	15	30	45	15
à 3000m																												
Vent (km/h)	10	10	20	10	10	10	10	10	10	10	10	10	10	15	20	20	60	35	25	15	15	15	15	10	10	10	20	20
à 2000m																												

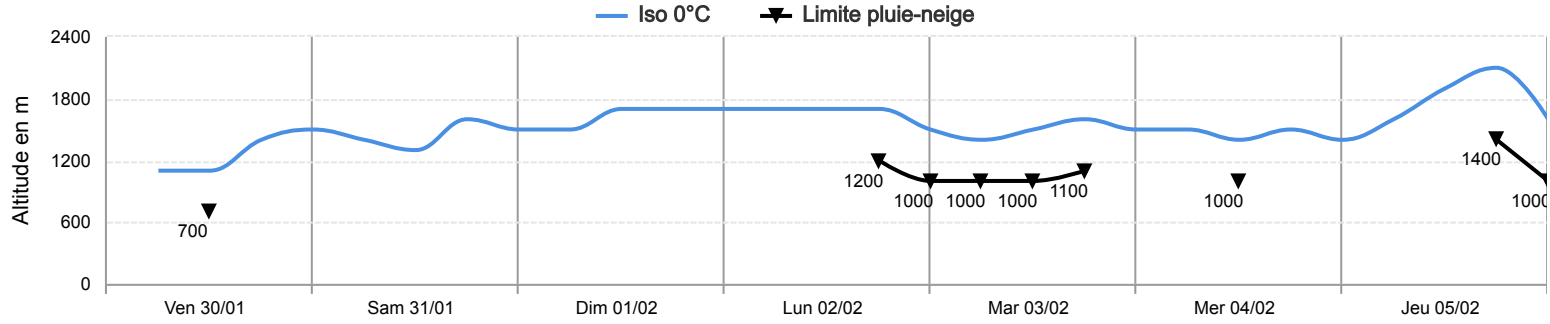

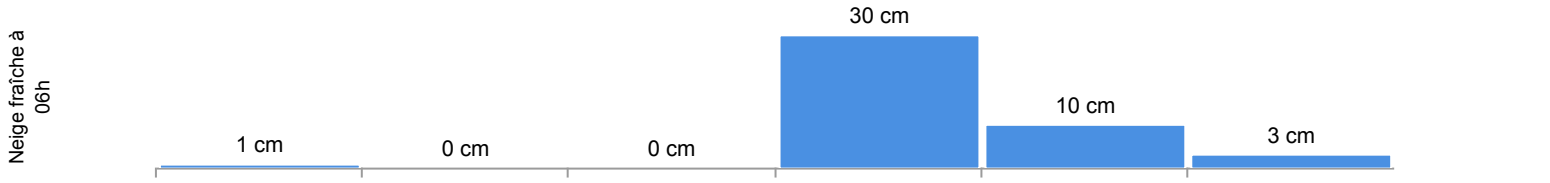

Risque d'avalanche	ven. 30/01	sam. 31/01	dim. 01/02	lun. 02/02	mar. 03/02	mer. 04/02	jeu. 05/02
	4	3	3	3	4	4	3

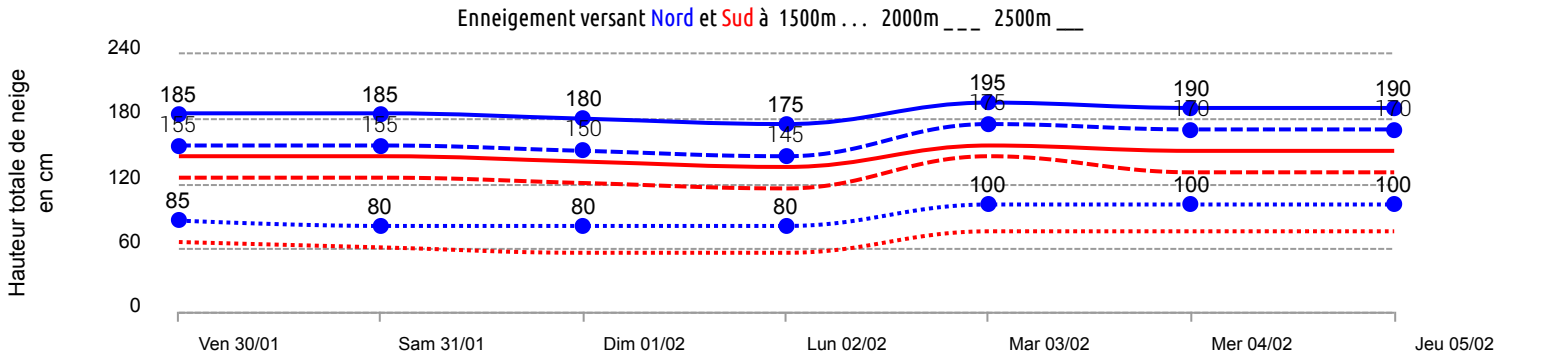

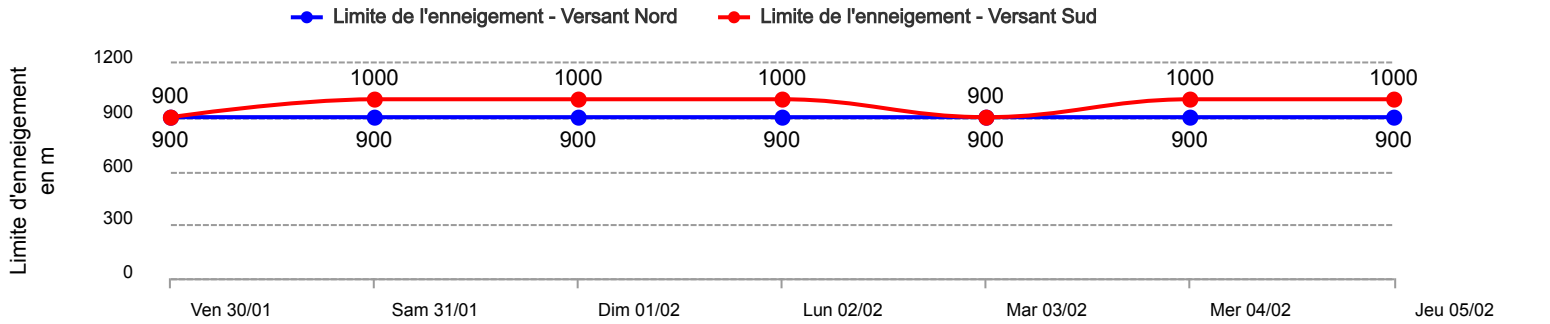

Pour consulter la vigilance en cours, veuillez vous rendre sur le site https://vigilance.meteofrance.fr/fr

Météo-France - 73 avenue de Paris, 94165 Saint-Mandé cedex - Contact : contact@meteo.fr

Bulletin neige & avalanches par téléphone au

0 892 68 10 20 Service 0,35 € / min + prix appel

Rédigé par Météo-France avec la contribution des observateurs du réseau nivo-météorologiques. Partenariat : ANMSM (Maires de Stations de Montagne), DSF (Domaines Skiables de France), ADSP (Directeurs de Pistes et de la Sécurité des Stations de Sports d'Hiver) et autres acteurs de la montagne.