Bulletin d'estimation du risque d'avalanche
(valable en dehors des pistes balisées et ouvertes)

MASSIF : Ubaye

Rédigé le jeudi 5 février 2026 à 16h

Estimation des risques pour le : VENDREDI 06 FÉVRIER

MANTEAU NEIGEUX INSTABLE. NOMBREUSES INSTABILITÉS, LOCALEMENT VOLUMINEUSES ET DÉCLENCHABLES À DISTANCE

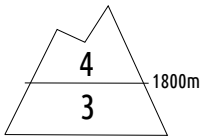

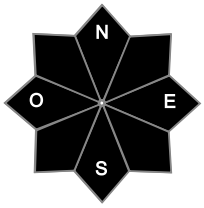

Au-dessus de 1800m indice de risque fort, plus bas indice marqué.

Départs spontanés : ponctuels ou avalanches de plaque, parfois de grande taille.

Déclenchements provoqués : nombreuses plaques. Faciles à déclencher, aussi à distance.

Indices de risque : 5 très fort - 4 fort - 3 marqué - 2 limité - 1 faible -- En noir : les pentes les plus dangereuses

Stabilité du manteau neigeux

Situation avalancheuse typique : neige fraîche — couche fragile persistante

Déclenchements provoqués : nombreuses plaques, en place ou en formation, possibles en toute orientation. Ces instabilités peuvent être difficiles à détecter car d'aspect poudreux, sinon durcies par le vent dans les secteurs exposés. Déclenchement facile par un skieur ou randonneur, même à distance, engendrant généralement une avalanche de taille petite à moyenne dans la neige fraiche/récente. En versants est, nord et ouest au-dessus de 1800/2000 m, possibles avalanches de taille moyenne à grande, très grande non exclue, emportant une grande partie du manteau neigeux, parfois sur de grandes distances. En effet, dans ces orientations, présence fréquente d'une couche fragile persistante encore insuffisamment enfouie et donc sollicitable.

Départs spontanés : des départs ponctuels ou des avalanches de plaque en neige sèche en altitude en pente raide. Taille petite à moyenne, possiblement grande en cas de plaque. En effet, avec les chutes de neige et le vent cette nuit, puis en fin de nuit et journée de vendredi avec le poids de la neige rapportée par le vent, l'activité avalancheuse spontanée peut être importante.
Par ailleurs, dans une éclaircie vendredi, possibles départs ponctuels superficiels au soleil en pente raide, près des rochers avec la neige qui s'humidifie superficiellement.

Qualité de la neige

Enneigement proche des normales pour un début février.
Données observées : 98 cm au-dessus de Larche à 2270 m, 13 cm à Barcelonnette à 1200 m.

Enneigement skiable dès 1300/1400 m en terrain favorable, mais peu de sous-couche sous 1600 m en général.

État de la neige en surface : neige humide sous 1300/1500 m. Sinon neige fraiche en quantité, plus ou moins travaillée par le vent, reposant sur de la neige plus dense/lourde sous 1800/2000 m environ, mais encore froide et souvent poudreuse au-dessus ou localement travaillée par le vent en altitude dans les secteurs exposés. Corniches et congères parfois volumineuses en place.

Aperçu météo pour le vendredi 06 février

	nuit	matin	après-midi	soir

Après les chutes de neige de la nuit (15 à 35 cm), les nuages dominent donnant par moments quelques flocons. Vent restant sensible.

Pluie-Neige	1 300 m			
Iso 0 °C	1 500 m	1 600 m	2 000 m	1 600 m
Vent 2000 m	↖ 20 km/h	↘ 20 km/h	↘ 25 km/h	↘ 10 km/h
Vent 3000 m	↖ 30 km/h	→ 35 km/h	→ 35 km/h	↘ 25 km/h

Épaisseur de neige hors-piste

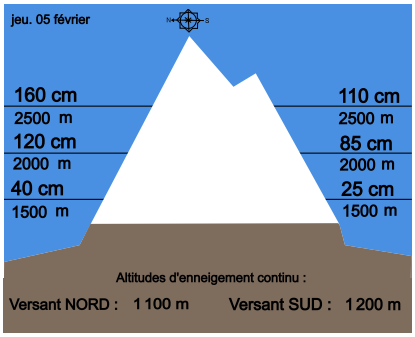

Précipitations à 1800 m

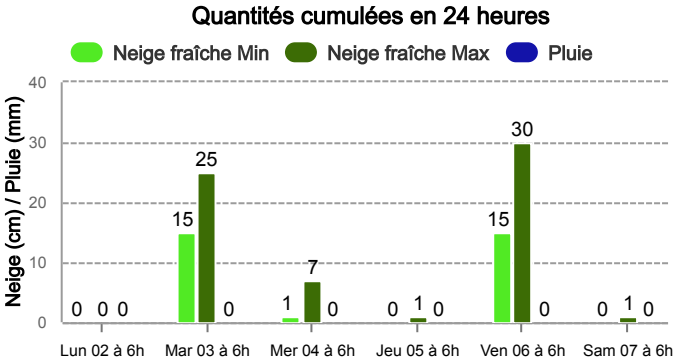

Tendance du samedi 07 février

Indice de risque fort

Risque stationnaire ou en baisse.
Nombreuses plaques en place encore faciles à déclencher.

Pour consulter la vigilance en cours, veuillez vous rendre sur le site https://vigilance.meteofrance.fr/fr

Météo-France - 73 avenue de Paris, 94165 Saint-Mandé cedex - Contact : contact@meteo.fr

Rédigé par Météo-France avec la contribution des observateurs du réseau nivo-météorologiques. Partenariat : ANMSM (Maires de Stations de Montagne), DSF (Domaines Skiables de France), ADSP (Directeurs de Pistes et de la Sécurité des Stations de Sports d'Hiver) et autres acteurs de la montagne.

Bulletin neige & avalanches par téléphone au **0 892 68 10 20** Service 0,35 € / min + prix appel

RÉPUBLIQUE FRANÇAISE
Liberté Égalité Fraternité

METEO FRANCE
À VOS CÔTÉS, DANS UN CLIMAT QUI CHANGE

Bulletin d'estimation du risque d'avalanche

(valable en dehors des pistes balisées et ouvertes)

MASSIF : Ubaye

Rédigé le jeudi 5 février 2026 à 16h

Conditions nivo-météo des 7 derniers jours

	ven. 30/01				sam. 31/01				dim. 01/02				lun. 02/02				mar. 03/02				mer. 04/02				jeu. 05/02			
	03h	09h	15h	21h	03h	09h	15h	21h	03h	09h	15h	21h	03h	09h	15h	21h	03h	09h	15h	21h	03h	09h	15h	21h	03h	09h	15h	21h
Météo																												
Vent (km/h)	30	40	30	20	25	15	20	15	15	15	15	20	20	25	35	55	70	45	35	25	25	25	20	20	25	30	40	40
à 3000m																												
Vent (km/h)	10	15	20	5	5	5	15	10	10	10	15	10	10	15	20	30	45	35	25	20	20	20	20	10	10	15	25	25
à 2000m																												

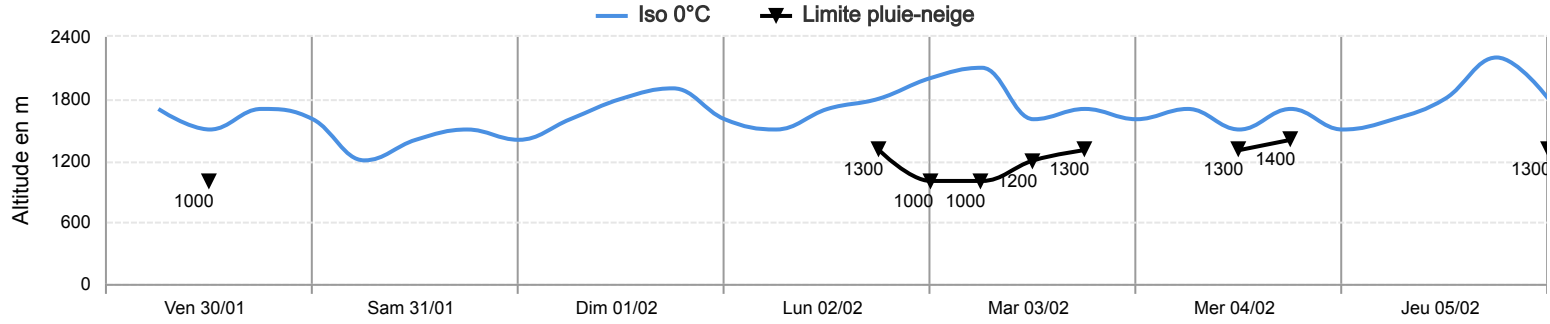

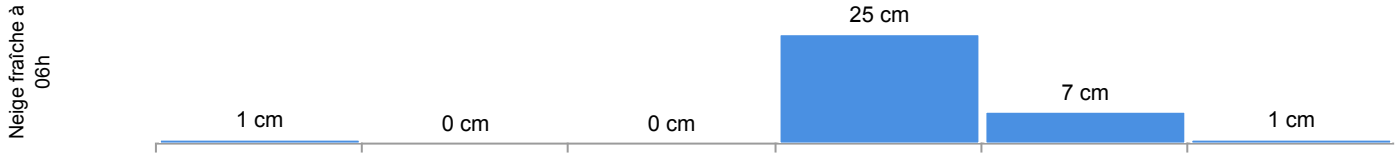

Risque d'avalanche	ven. 30/01	sam. 31/01	dim. 01/02	lun. 02/02	mar. 03/02	mer. 04/02	jeu. 05/02
	4	3	3	3	4	4	3

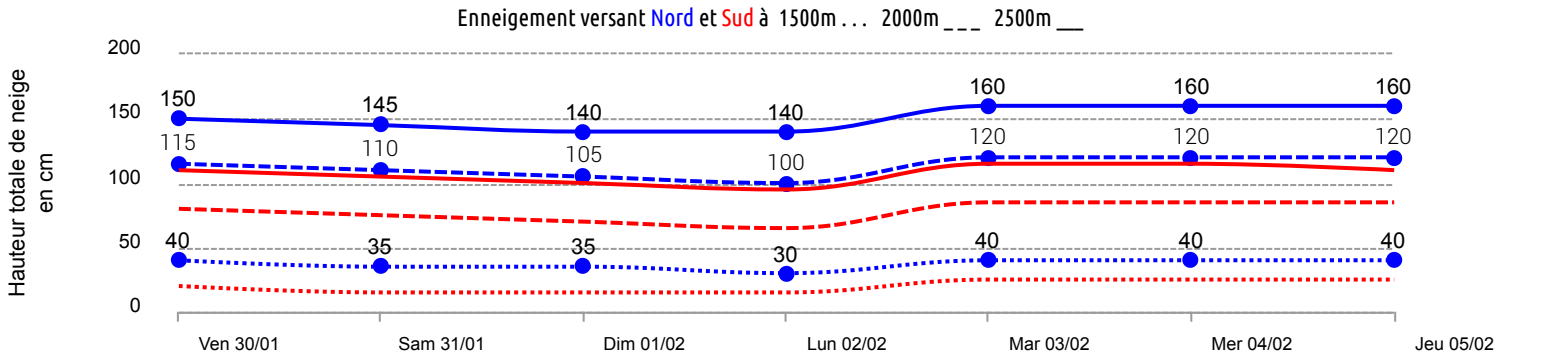

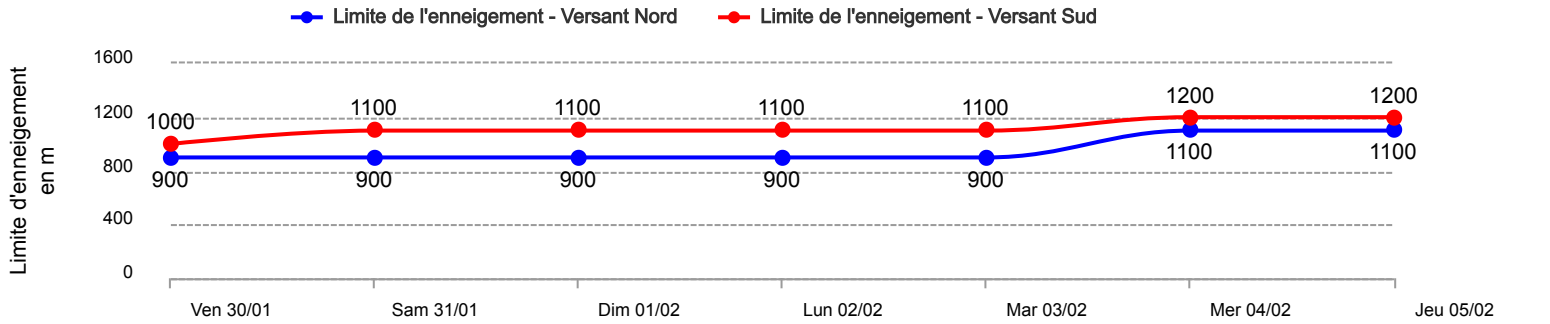

Pour consulter la vigilance en cours, veuillez vous rendre sur le site https://vigilance.meteofrance.fr/fr

Météo-France - 73 avenue de Paris, 94165 Saint-Mandé cedex - Contact : contact@meteo.fr

Bulletin neige & avalanches par téléphone au

0 892 68 10 20 Service 0,35 € / min + prix appel

Rédigé par Météo-France avec la contribution des observateurs du réseau nivo-météorologiques. Partenariat : ANMSM (Maires de Stations de Montagne), DSF (Domaines Skiables de France), ADSP (Directeurs de Pistes et de la Sécurité des Stations de Sports d'Hiver) et autres acteurs de la montagne.