GOBIERNO DE ESPAÑA
VICEPRESIDENCIA TERCERA DEL GOBIERNO
MINISTERIO PARA LA TRANSICIÓN ECOLÓGICA Y EL RETO DEMOGRÁFICO

Boletín de información nivológica y de peligro de aludes

Pirineo Navarro y Aragonés

aemet Agencia Estatal de Meteorología

viernes, 6 de febrero de 2026

Pronóstico hasta las 24 horas del sábado, día 7 de febrero

(Válido fuera de pistas de esquí balizadas y abiertas)

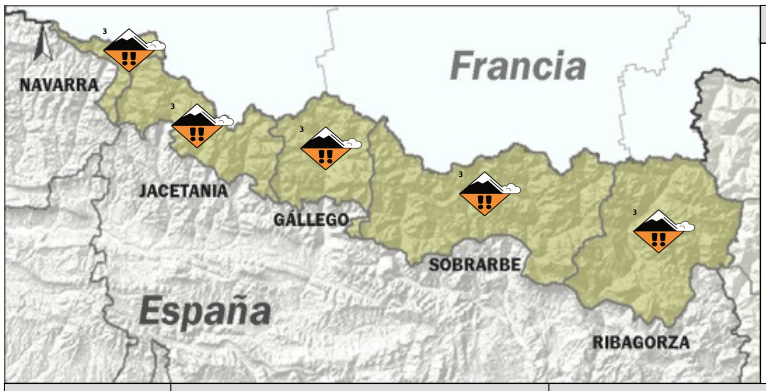

Problemas de aludes

Placas de viento

Nieve reciente

Macizo	Peligro	Problemas de aludes, cota, orientación, tamaño	Innivación observada (m)
Navarra	3 Notable	Placas de viento: 2100, N O E S, 3 Nieve reciente: N O E S, 2	2026-02-06 N S Cotas bajas
Jacetania	3 Notable	Placas de viento: 2100, N O E S, 3 Nieve reciente: N O E S, 2	2026-02-06 N S Cotas bajas
Gállego	3 Notable	Placas de viento: 2100, N O E S, 3 Nieve reciente: N O E S, 2	2026-02-06 N S Cotas bajas

AEMET. Se autoriza la reproducción de su contenido citando la fuente.

Boletín de información nivológica y de peligro de aludes

Pirineo Navarro y Aragonés

Sobrarbe	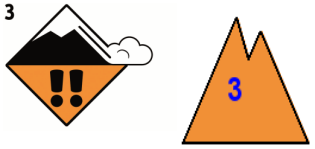 **Notable**	**Placas de viento** 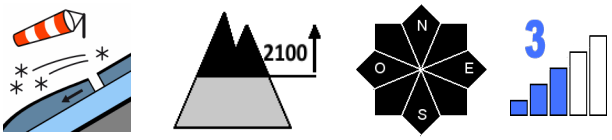 **Nieve reciente** 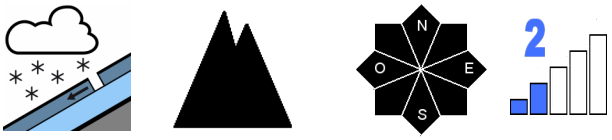	2026-02-06
Ribagorza	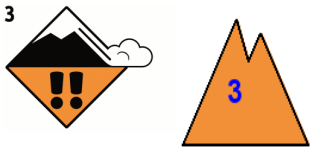 **Notable**	**Placas de viento** 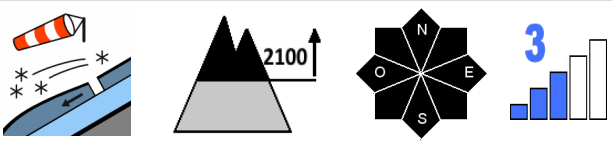 **Nieve reciente** 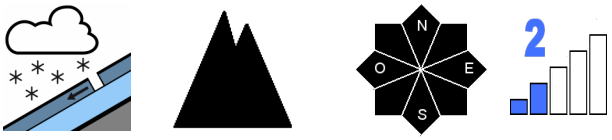	2026-02-06

Estado del manto y observaciones recientes

Sigue la sucesión de borrascas asociadas al chorro polar, dando lugar precipitaciones abundantes en la cordillera desde hace semanas. Durante las últimas 24 horas se han vuelto a registrar nevadas, con depósitos de nieve nueva entre 5 y 25 cm, por lo que el grosor del manto, ya de por sí importante, continúa en aumento, con espesores que por encima de 2.000 metros superan fácilmente los 200 a 220 cm, aún más en ventisqueros, hoyas u otras zonas propensas a la acumulación.

El perfil del manto consta de una capa superficial de nieve reciente de espesor variable y otras múltiples en el interior donde se van intercalando grano fino o redondo con costras de rehielo. En cotas altas la nieve se mantiene más seca, venteada y menos evolucionada, en particular en zonas de umbría, donde todavía pueden persistir estratos débiles.

Continúan las purgas de nieve reciente en los diferentes puntos de observación, que han sido, en general, de tamaño pequeño o mediano.

Evolución del manto y peligro de aludes para el sábado, día 7

Situación de nieve reciente, y de placas de viento en cotas altas.

Pocos cambios durante las próximas 24 horas, con nuevas precipitaciones en forma sólida que podrán depositar, en general, del orden de 10 a 20 cm adicionales sobre el manto previo. En consecuencia seguirán las purgas de nieve reciente en laderas suficientemente inclinadas de cualquier orientación, de tamaño pequeño o mediano, aunque no se descarta que en zonas donde las acumulaciones sean importantes puedan adquirir dimensiones aún mayores.

AEMET. Se autoriza la reproducción de su contenido citando la fuente.

Los fuertes vientos de componentes oeste y sur han formado placas en diferentes áreas de cotas altas, con preferencia en vertientes este y norte, que vienen a sumarse a las todavía existentes en otras orientaciones, correspondientes a episodios previos, y que han podido quedar enterradas por las nevadas de estos días, dificultando su localización. Todas estas estructuras permanecen frágiles y son susceptibles de fractura ante sobrecargas débiles, como es el paso de un esquiador, ocasionando aludes incluso de dimensiones grandes, tamaño suficiente como para enterrar a un grupo de personas.

También resaltar que en las umbrías de alta montaña pueden persistir estratos débiles en el interior del manto que siguen dando muestras de reactividad, especialmente en zonas de poco espesor, por lo que se recomienda extremar las precauciones si se va a transitar por la zona.

Predicción meteorológica para el sábado, día 7

Intervalos nubosos, aumentando a muy nuboso o cubierto al final del día, con algunas precipitaciones débiles de madrugada y a últimas horas, cuando podrán ser localmente moderadas. Cota de nieve: en torno a 800 metros ó 1.000 metros. Temperaturas en descenso, ligero en las máximas y moderado de las mínimas. Heladas débiles o moderadas, persistentes y localmente fuertes en la alta montaña. Soplarán vientos moderados de componente oeste, girando a sur por la tarde, siendo fuertes en cotas altas y zonas expuestas, donde habrá ventiscas.

Datos en la atmósfera libre:

Altitud de la isoterma de 0 ºC: 1.600 m
Altitud de la isoterma de -10 ºC: 3.200 m

Viento a 1500 m: W 30 km/h
Viento a 3000 m: W 30 km/h

Evolución para el domingo día 8

Nivel de peligro con pocos cambios.

(Información elaborada a partir de los datos recibidos de los refugios de Linza, Lizara, Panticosa, Bachimaña, Góriz, Estós, Angel Orús, La Renclusa, Cap de Llauset y Belagua y de las estaciones de esquí de Astún, Formigal y Panticosa (lagos))

Escala europea de peligro de aludes

Débil | Limitado | Notable | Fuerte | Muy Fuerte

Problemas de aludes

Nieve reciente | Placas de viento | Capas débiles persistentes | Nieve húmeda | Deslizamientos basales | Sin problema evidente

Nota1: Se recuerda que, siempre que haya nieve, la ausencia total de peligro no existe. Hay que tener presente que en circunstancias desfavorables, con aludes de tamaño 1 (alud pequeño o colada) y tamaño 2 (alud mediano), se pueden sufrir severos daños personales.

Nota2: Los BPA se elaboran en base a información meteorológica así como al estado del manto nivoso a través de sondeos puntuales. Se advierte a los usuarios de la variabilidad de esta información al extrapolarla a zonas extensas de montaña. Por ello, AEMET no se hace responsable de su uso para la toma de decisiones que conciernen a la seguridad personal, ni de los riesgos físicos o materiales de ellas derivadas.

AEMET. Se autoriza la reproducción de su contenido citando la fuente.