aineva.it

# Venerdì 06.02.2026

Aggiornato06.02.2026 alle ore 14:52

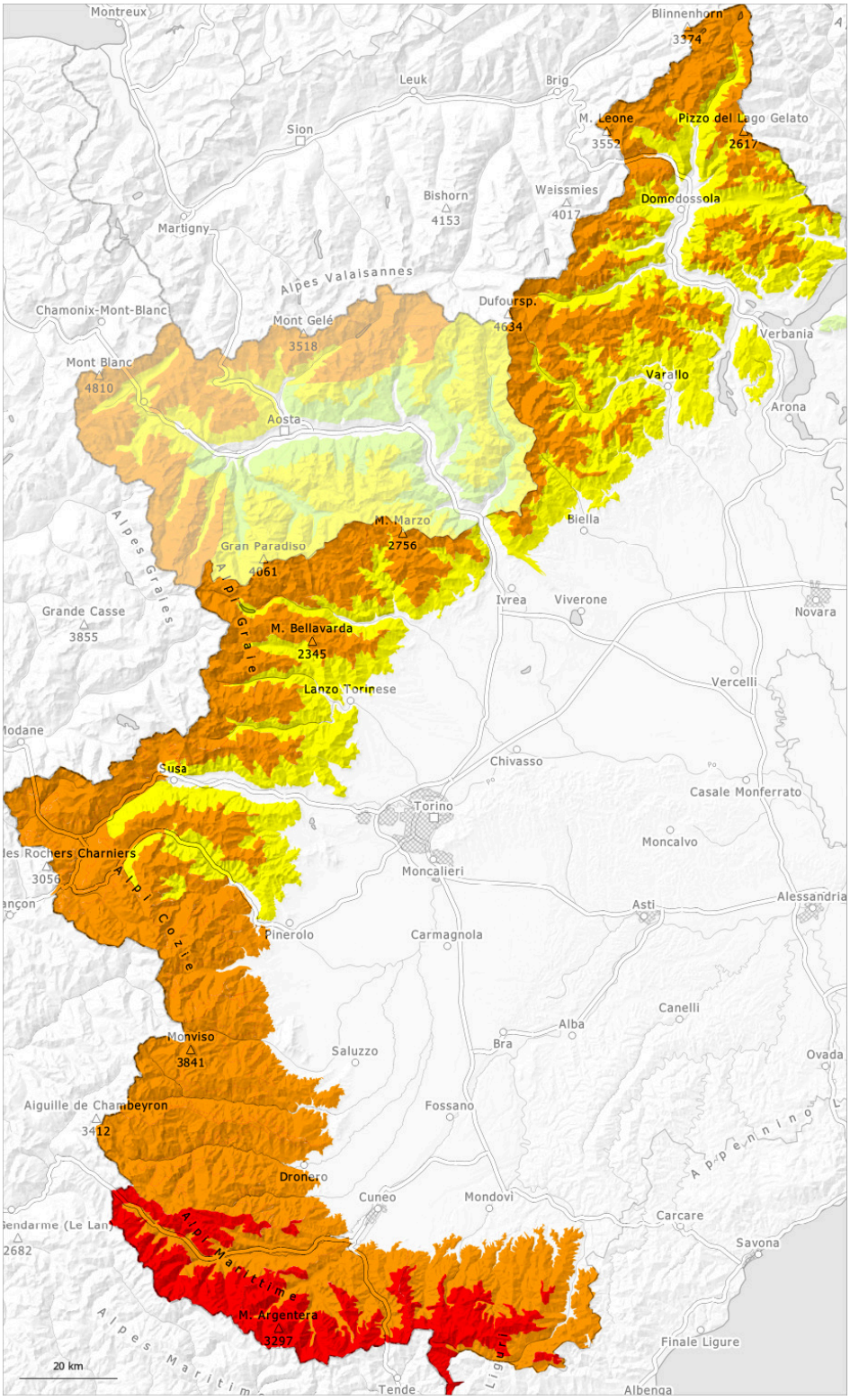


| 1 | 2 | 3 | 4 | 5 |
|---|---|---|---|---|
| debole | moderato | marcato | forte | molto forte |

## Grado di pericolo 4 - Forte

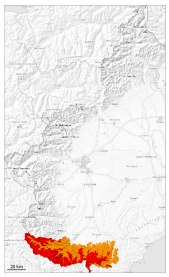

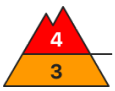


**Limite del bosco**

**Tendenza: pericolo valanghe in diminuzione**
per Sabato il 07.02.2026

Lastrone da vento

**Limite del bosco**

Neve bagnata

**2200m**

### Con la neve fresca e il rialzo termico, la situazione valanghiva è molto delicata. Per le escursioni al di fuori delle piste assicurate, le condizioni sono sfavorevoli.

Fino alla mattinata cadrà neve al di sopra dei 700 m circa. Con neve fresca e vento moderato si formeranno ulteriori accumuli di neve ventata. Essi possono distaccarsi facilmente e raggiungere dimensioni molto grandi. Spesso le valanghe possono subire un distacco nei vari strati di neve ventata. Ciò soprattutto sui pendii ripidi al di sopra del limite del bosco, come pure nelle conche, nei canaloni e dietro ai cambi di pendenza.
Con il rialzo termico e l'irradiazione solare, l'attività di valanghe spontanee aumenterà rapidamente, principalmente dai bacini di alimentazione ripidi soleggiati non ancora completamente scaricati.
Le escursioni richiedono una grande attenzione e la massima prudenza.

## Manto nevoso

**Situazione tipo** st.6: neve a debole coesione e vento | st.2: neve da slittamento

Fino alla mattinata cadranno sino a 30 cm di neve al di sopra dei 1500 m circa, localmente anche di più.
Con il vento moderato, si formeranno nuovi accumuli di neve ventata. In molti punti la neve fresca e quella ventata poggiano su strati soffici.
Il sole e il calore causeranno a partire dal mattino soprattutto sui pendii soleggiati ripidi alle quote di bassa e media montagna un rapido impregnamento del manto nevoso.
Al di sopra dei 1000 m circa è presente molta neve.

## Tendenza

Le condizioni meteo causeranno un graduale assestamento del manto nevoso.

## Grado di pericolo 3 - Marcato

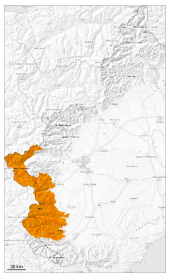

3

**Tendenza: pericolo valanghe stabile**
per Sabato il 07.02.2026

Lastrone da vento

**Limite del bosco**

Neve bagnata

**2200m**

### Marcato pericolo di valanghe. Neve ventata e neve bagnata sono la principale fonte di pericolo.

Fino alla mattinata cadrà un po' di neve. Con neve fresca e vento in parte moderato si formeranno accumuli di neve ventata in parte di grandi dimensioni. Gli accumuli di neve ventata possono distaccarsi già in seguito al passaggio di un singolo appassionato di sport invernali. Ciò soprattutto sui pendii ripidi, come pure nelle conche, nei canaloni e dietro ai cambi di pendenza anche alle quote di media montagna.
Le valanghe possono subire un distacco negli strati più profondi del manto nevoso specialmente sui pendii ripidi ombreggiati.
Con il rialzo termico e l'irradiazione solare diurni, sono possibili valanghe umide spontanee di medie e, a livello isolato, di grandi dimensioni, principalmente dai bacini di alimentazione ripidi soleggiati non ancora scaricati.
I punti pericolosi sono in parte innevati difficili da individuare. Si consiglia una prudente scelta dell'itinerario e di mantenere le distanze di scarico.

## Manto nevoso

**Situazione tipo** st.6: neve a debole coesione e vento | st.1: strato debole persistente basale

Fino alla mattinata cadranno diffusamente da 10 a 20 cm di neve. Con neve fresca e vento in parte moderato proveniente dai quadranti occidentali soprattutto al di sopra del limite del bosco si formeranno ulteriori accumuli di neve ventata. La neve fresca e la neve ventata poggiano su strati soffici sui pendii riparati dal vento ombreggiati.

Alle quote medie e alte: Soprattutto sui pendii ombreggiati molto ripidi, nella parte basale del manto nevoso si trovano, a livello isolato, strati fragili instabili.

## Grado di pericolo 3 - Marcato

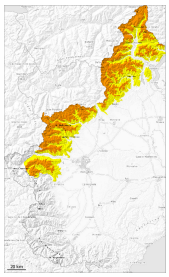

**Limite del bosco**

**Tendenza: pericolo valanghe stabile**
per Sabato il 07.02.2026

Lastrone da vento

**Limite del bosco**

Neve bagnata

**2100m**

### Alle quote medie e alte marcato pericolo di valanghe.

Fino alla mattinata cadrà un po' di neve. Con neve fresca e vento moderato proveniente dai quadranti nord occidentali si formeranno accumuli di neve ventata in parte di grandi dimensioni. Ciò soprattutto sui pendii ripidi, come pure nelle conche, nei canaloni e dietro ai cambi di pendenza al di sopra del limite del bosco. I nuovi accumuli di neve ventata possono distaccarsi con un debole sovraccarico. Le valanghe possono subire un distacco negli strati più profondi del manto nevoso specialmente sui pendii molto ripidi ombreggiati.

Con il rialzo termico e l'irradiazione solare diurni, sono possibili valanghe asciutte spontanee di dimensioni medio-grandi. Ciò soprattutto dai bacini di alimentazione molto ripidi soleggiati non ancora scaricati.

Si consiglia una prudente scelta dell'itinerario e di mantenere le distanze di scarico.

## Manto nevoso

**Situazione tipo** st.6: neve a debole coesione e vento | st.1: strato debole persistente basale

Fino alla mattinata cadranno diffusamente da 5 a 15 cm di neve. Con neve fresca e vento in parte moderato si formeranno ulteriori accumuli di neve ventata. La neve fresca e la neve ventata poggiano su strati soffici soprattutto sui pendii riparati dal vento ombreggiati.

Alle quote medie e alte: Soprattutto sui pendii ombreggiati molto ripidi, nella parte basale del manto nevoso si trovano, a livello isolato, strati fragili instabili.