Freitag 06.02.2026

Aktualisiert am 06.02.2026 um 14:52

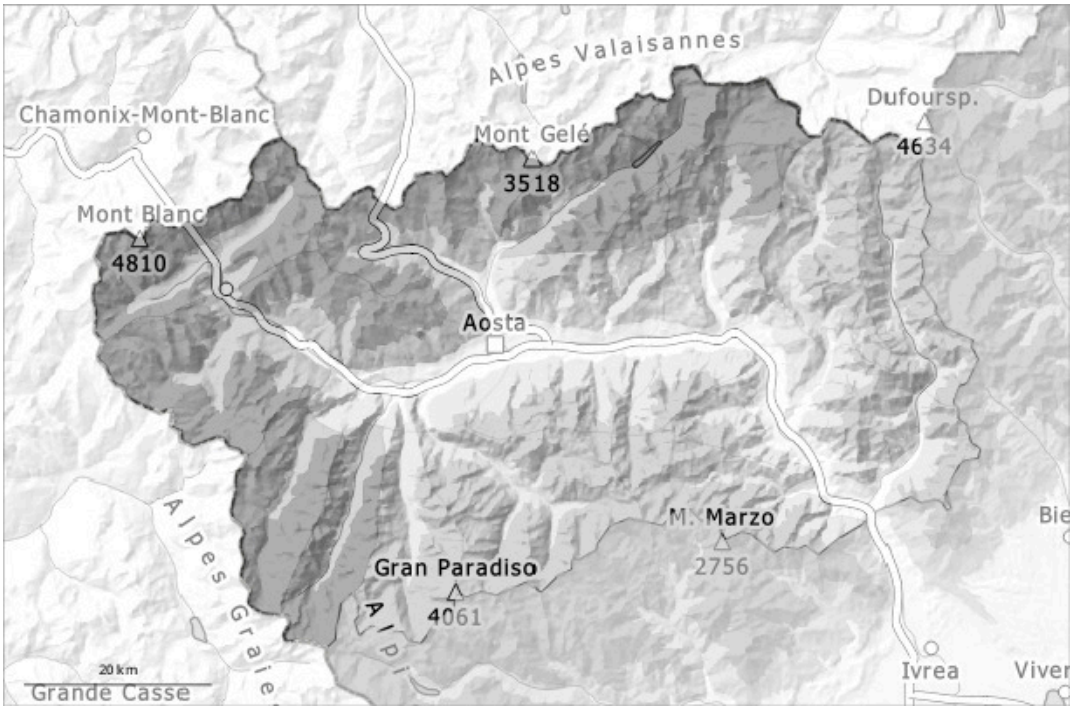

1	2	3	4	5
gering	mäßig	erheblich	groß	sehr groß

Gefahrenstufe 3 - Erheblich

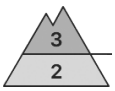

2200m

Tendenz: Lawinengefahr bleibt gleich
am Samstag, den 07.02.2026

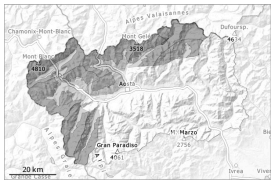

Triebschnee

2200m

Altschnee

2000m

Auf den Grenzkämmen Richtung Frankreich und Schweiz und je höher man steigt, desto häufiger werden die Gefahrenstellen.

Mit Neuschnee und mäßigem Wind aus wechselnden Richtungen entstehen am Vormittag vor allem in den Niederschlagsgebieten störanfällige Triebschneeansammlungen. Die Gefahr von trockenen Lawinen steigt bereits am Vormittag an.
Einzelne Wintersportler können Lawinen auslösen. Sie sind meist oberflächlich, Vorsicht vor allem in Kammlagen, Rinnen und Mulden und an sehr steilen Hängen vor allem oberhalb der Waldgrenze. Die Triebschneeansammlungen sind teilweise schlecht mit dem Altschnee verbunden. Die Gefahrenstellen sind kaum zu erkennen.
Die Lawinen können an sehr steilen Schattenhängen in tiefen Schichten ausgelöst werden. Besonders ungünstig sind in diesem Winter erst selten befahrene Hänge.
Eine vorsichtige Routenwahl und Entlastungsabstände werden empfohlen.
Die spontane Lawinenaktivität nimmt mit der Erwärmung zu, v.a. aus sehr steilen Einzugsgebieten.

Schneedecke

Gefahrenmuster gm.6: lockerer schnee und wind | gm.1: bodennahe schwachschicht

Freitag: Es fallen oberhalb von rund 1400 m 15 bis 25 cm Schnee, lokal auch mehr.
Mittwoch: Es fielen oberhalb von rund 1500 m 5 bis 10 cm Schnee, lokal auch weniger.
Dienstag: Es fielen oberhalb von rund 2000 m 5 bis 15 cm Schnee, lokal auch mehr.
Der Neuschnee und insbesondere die weichen und harten Triebschneeansammlungen bedecken eine schwache alte Schneedecke und teilweise auch Oberflächenfrost.
In der Altschneedecke sind v.a. an West-, Nord- und Osthängen kantig aufgebaute Schwachschichten vorhanden.
Seit Mittwoch gingen an sehr steilen Hängen mittlere und vereinzelt große Lawinen spontan ab, vor allem aus hohen Einzugsgebieten.

Tendenz

> Die Wetterbedingungen erlauben eine langsame Verfestigung der Schneedecke. Die Gefahr nimmt noch nicht ab.

Gefahrenstufe 2 - Mäßig

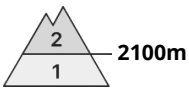

Tendenz: Lawinengefahr bleibt gleich
am Samstag, den 07.02.2026

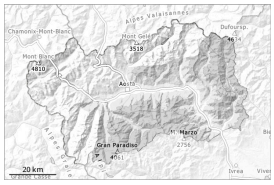

Triebschnee

Altschnee

In der Nähe der drei erheblichen Gefahrenzonen und mit zunehmender Höhe werden die Gefahrenstellen immer häufiger.

Mit Neuschnee und mäßigem Wind aus wechselnden Richtungen entstehen am Vormittag vor allem in Kammlagen meist dünne Triebschneeansammlungen. Die Gefahr von trockenen Lawinen steigt innerhalb der Gefahrenstufe an.
Einzelne Wintersportler können Lawinen auslösen, auch solche mittlerer Größe. Sie sind meist oberflächlich, Vorsicht vor allem in Kammlagen, Rinnen und Mulden und an sehr steilen Hängen vor allem oberhalb der Waldgrenze. Die Gefahrenstellen sind kaum zu erkennen.
Die Lawinen können an sehr steilen Schattenhängen in tiefen Schichten anreißen und recht groß werden. Besonders ungünstig sind in diesem Winter erst selten befahrene Hänge.
Entlastungsabstände werden empfohlen.
Die spontane Lawinenaktivität nimmt mit der Erwärmung langsam zu, v.a. aus sehr steilen Einzugsgebieten.

Schneedecke

Gefahrenmuster gm.6: lockerer schnee und wind | gm.1: bodennahe schwachschicht

Freitag: Es fallen oberhalb von rund 1600 m 10 bis 15 cm Schnee, lokal auch weniger.
Mittwoch: Es fielen oberhalb von rund 1500 m 5 bis 10 cm Schnee, lokal auch weniger.
Dienstag: Es fielen oberhalb von rund 2000 m 5 bis 15 cm Schnee, lokal auch mehr.
Der Neuschnee und insbesondere die weichen und harten Triebschneeansammlungen bedecken eine schwache alte Schneedecke und teilweise auch Oberflächenfrost.
In der Altschneedecke sind v.a. an West-, Nord- und Osthängen kantig aufgebaute Schwachschichten vorhanden.
Seit Mittwoch gingen an sehr steilen Hängen kleine und mittlere Lawinen spontan ab, vor allem aus hohen Einzugsgebieten.

Tendenz

> Die Wetterbedingungen erlauben eine langsame Verfestigung der Schneedecke. Die Gefahr bleibt bestehen.