aineva.it

Samedi 07.02.2026

Publié 06 02 2026, 17:00

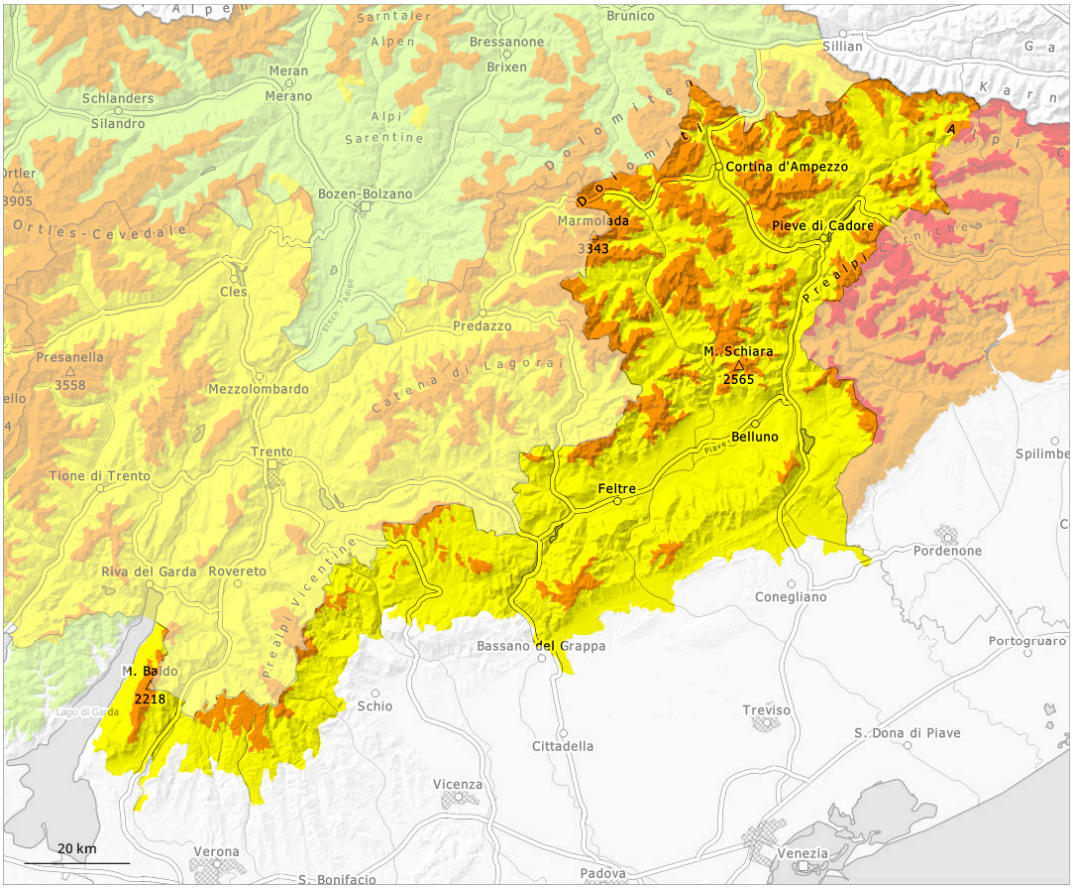

1	2	3	4	5
faible	limité	marqué	fort	très fort

Degré de danger 3 - Marqué

Limite de la forêt

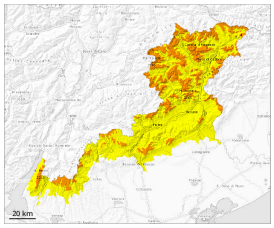

Neige soufflée (Neige ventée)

Limite de la forêt

Neige ancienne (Sous-couche fragile persistante)

Limite de la forêt

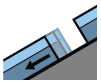

Avalanches de glissement (Avalanches de fond)

2000m

Les accumulations de neige soufflée de la semaine écoulée constituent le danger principal.

En général des accumulations de neige soufflée facilement déclenchables se sont formées. Les accumulations de neige soufflée se situent surtout à proximité des crêtes, dans les combes et couloirs. Les endroits dangereux se trouvent Surtout sur les pentes où s'est accumulée la neige soufflée à toutes les expositions au-dessus d'environ 1900 m ainsi qu'aux transitions entre les endroits faiblement et fortement enneigés.

Manteau neigeux

La neige fraîche de la semaine écoulée repose sur du givre de surface au-dessus de la limite de la forêt. Les profils de neige et les tests de stabilité ont confirmé la structure défavorable du manteau neigeux. Des couches fragiles profondes dans le manteau neigeux ne sont que difficilement identifiables. La partie inférieure du manteau neigeux a subi une métamorphose constructive à grains anguleux et est fragile. Des avalanches peuvent être déclenchées très facilement dans les couches plus profondes du manteau neigeux. Des avalanches de glissement isolées peuvent également se déclencher pendant la nuit ou le matin.