ICGC Institut Cartogràfic i Geològic de Catalunya

Servei Meteorològic de Catalunya meteo.cat

# Boletín de peligro de aludes para el Pirineo de Catalunya
# Del 06/02/2026 al 07/02/2026

(Válido fuera pistas de esquí y zonas no controladas)

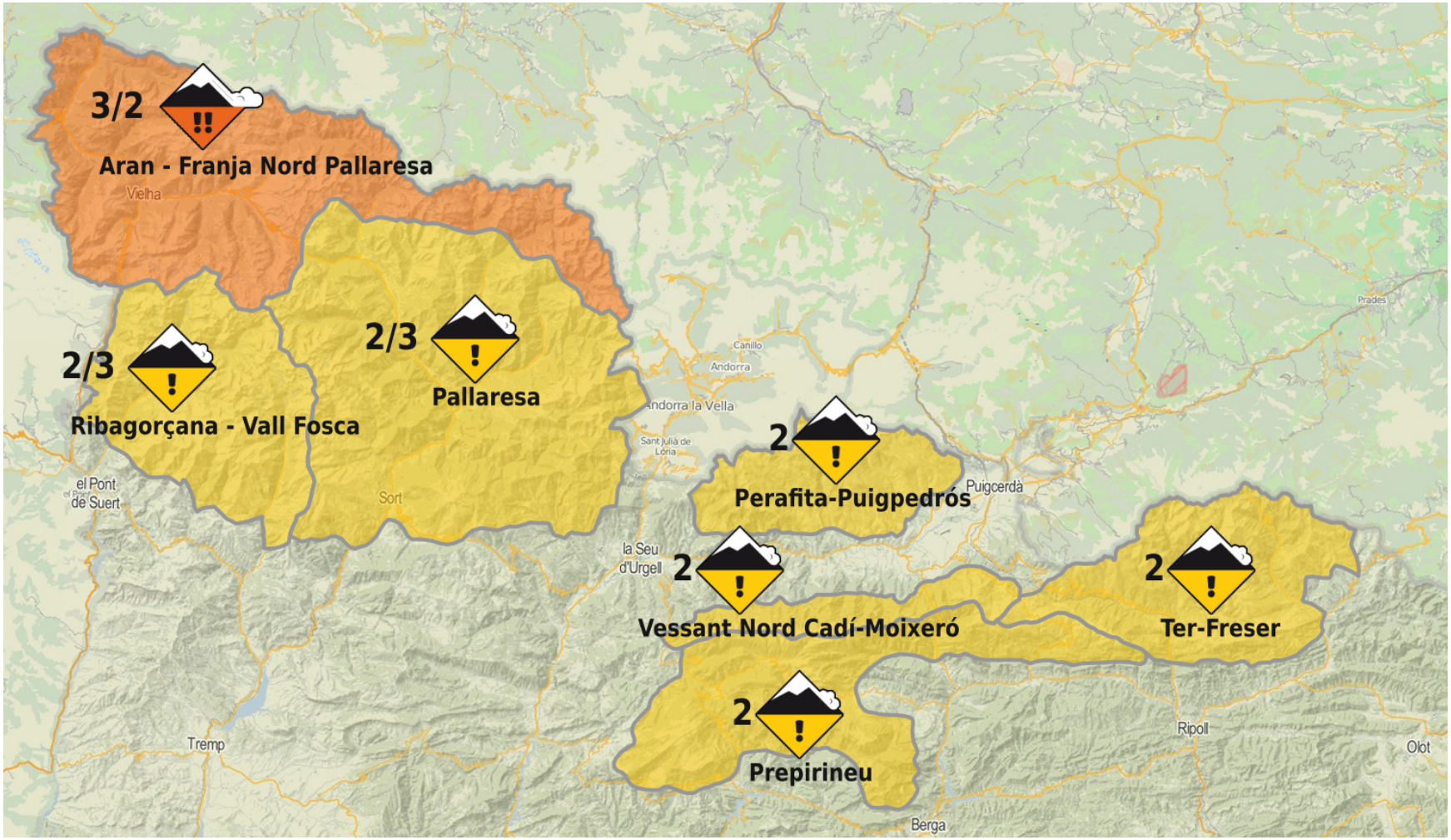


| | | | | |
|---|---|---|---|---|
| 5 MUY FUERTE | 4 FUERTE | 3 NOTABLE | 2 LIMITADO | 1 DÉBIL |

ICGC Institut Cartogràfic i Geològic de Catalunya

Servei Meteorològic de Catalunya meteo.cat

# Boletín de peligro de aludes Aran - Franja Nord Pallaresa Del 06/02/2026 al 07/02/2026

(Válido fuera pistas de esquí y zonas no controladas)

Notable (3), por encima de los 2.200 m. Limitado (2), en el resto.

## Situación primaria

**Nieve venteada**

**Distribución**

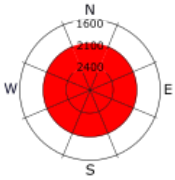


**Tamaño**

**Origen**

**Tendencia**

## Situación secundaria

**Nieve reciente**

**Distribución**

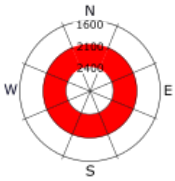


**Tamaño**

**Origen**

**Tendencia**

**Estado del manto nivoso**

Con la última nevada acompañada de viento del Sur y del Oeste se han formado nuevas placas que pueden desencadenarse fácilmente, al paso de un esquiador o de un montañero. Las placas las encontraremos sobre todo por encima del límite del bosque y en cualquier orientación, preferentemente, en Norte y Este. Pueden llegar hasta tamaño mediano (con capacidad de enterrar a una persona). Estas placas pueden quedar tapadas por nieve reciente. Por otro lado, además del problema de placa de viento, tenemos el problema de nieve reciente centrado sobre todo por debajo de los 2400 m. Estos aludes pueden caer de forma natural, en laderas con fuerte inclinación y serán de pequeño tamaño. Los deslizamientos basales han ido cayendo durante la semana, pero aún pueden existir en vertientes, que no se hayan purgado, de fuerte inclinación. Podrán ser por lo general de tamaño mediano.

**Distribución del manto nivoso**

Hay nieve en el suelo a 1.000 m. El manto es esquiable por encima de unos 1.500 m. Los espesores a unos 2.200 m rondan los 100-135 cm en el norte de Arán y 140-190 cm en la Franja Norte Pallaresa y en el sur de Aran, y son superiores a los normales por estas fechas.

**Tendencia para las próximas 48-72h**

En los próximos días volverá a nevar, con viento en altura. Las placas de viento se mantendrán todavía reactivas. Peligro ESTACIONARIO.

**El próximo boletín será emitido el día 2026-02-07**

| | | | | |
|---|---|---|---|---|
| 5 MUY FUERTE | 4 FUERTE | 3 NOTABLE | 2 LIMITADO | 1 DÉBIL |

EAWS EUROPEAN AVALANCHE WARNING SERVICES

ICGC Institut Cartogràfic i Geològic de Catalunya

Servei Meteorològic de Catalunya

# Boletín de peligro de aludes Ribagorçana - Vall Fosca Del 06/02/2026 al 07/02/2026

(Válido fuera pistas de esquí y zonas no controladas)

Limitado (2) por debajo de 2400 m, Notable (3) por encima

## Situación primaria

**Nieve venteada**

**Distribución**

**Tamaño**

**Origen**

**Tendencia**

## Situación secundaria

**Nieve reciente**

**Distribución**

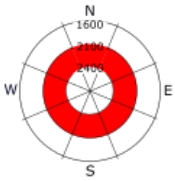


**Tamaño**

**Origen**

**Tendencia**

**Estado del manto nivoso**

Por debajo de los 2300-2400 m la nieve reciente de ayer jueves, se presenta pesada y húmeda. Son probables caídas de aludes de nieve reciente de forma natural. Estos aludes serán purgos (sin capacidad de enterrarnos) y se darán en pendientes fuertemente inclinadas. Por encima de los 2300-2400 m, el manto nivoso está constituido por placas que se desarrollaron ayer a sotavento del viento del oeste. Estas placas se formaron primero con nieve fría y después, con la subida de la cota de nieve, con nieve más pesada para acabar de taparse con nieve otra vez más fría. Pueden caer fácilmente a nuestro paso y alcanzar tamaño suficiente para enterrar a una persona. Se encuentran especialmente en ladera E, N y en algunas zonas S resguardadas del viento de W. La nieve que pueda caer de cara a mañana puede tapar las placas existentes no se descarta, que se forme alguna nueva muy pequeña. En ese caso sería susceptible de caer a nuestro paso por encima de los 2200 m.

**Distribución del manto nivoso**

Hay nieve en el suelo a 1.500 m. El manto es esquiable por encima de unos 1500-1600 m. Los grosores alcanzan los 130-160 cm. Estos valores son muy superiores a los normales en la época.

**Tendencia para las próximas 48-72h**

En los próximos días volverá a nevar, con viento en altura. Las placas de viento se mantendrán todavía reactivas. Peligro ESTACIONARIO.

**El próximo boletín será emitido el día 2026-02-07**

| | | | | |
|---|---|---|---|---|
| 5 MUY FUERTE | 4 FUERTE | 3 NOTABLE | 2 LIMITADO | 1 DÉBIL |

EAWS EUROPEAN AVALANCHE WARNING SERVICES

ICGC Institut Cartogràfic i Geològic de Catalunya

Servei Meteorològic de Catalunya

# Boletín de peligro de aludes Pallaresa
# Del 06/02/2026 al 07/02/2026

(Válido fuera pistas de esquí y zonas no controladas)

Limitado (2) por debajo de 2400 m, Notable (3) por encima

## Situación primaria

**Nieve venteada**

**Distribución**

**Tamaño**

**Origen**

**Tendencia**

## Situación secundaria

**Nieve reciente**

**Distribución**

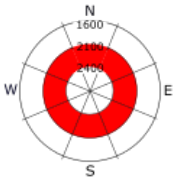


**Tamaño**

**Origen**

**Tendencia**

**Estado del manto nivoso**

Por debajo de los 2300-2400 m la nieve reciente de ayer jueves, se presenta pesada y húmeda. Son probables caídas de aludes de nieve reciente de forma natural. Estos aludes serán purgos (sin capacidad de enterrarnos) y se darán en pendientes fuertemente inclinadas. Por encima de los 2300-2400 m, el manto nivoso está constituido por placas que se desarrollaron ayer a sotavento del viento del oeste. Estas placas se formaron primero con nieve fría y después, con la subida de la cota de nieve, con nieve más pesada para acabar de taparse con nieve otra vez más fría. Pueden caer fácilmente a nuestro paso y alcanzar tamaño suficiente para enterrar a una persona. Se encuentran especialmente en ladera E, N y en algunas zonas S resguardadas del viento de W. La nieve que pueda caer de cara a mañana puede tapar las placas existentes no se descarta, que se forme alguna nueva muy pequeña. En ese caso sería susceptible de caer a nuestro paso por encima de los 2200 m.

**Distribución del manto nivoso**

Hay nieve desde 1500 m, esquiable a 1500-1600 m. Los espesores en cotas altas y medias superan los 140-150 cm. Estos valores son superiores a los normales para la época.

**Tendencia para las próximas 48-72h**

En los próximos días volverá a nevar, con viento en altura. Las placas de viento se mantendrán todavía reactivas. Peligro ESTACIONARIO.

**El próximo boletín será emitido el día 2026-02-07**

| | | | | |
|---|---|---|---|---|
| 5 MUY FUERTE | 4 FUERTE | 3 NOTABLE | 2 LIMITADO | 1 DÉBIL |

EAWS EUROPEAN AVALANCHE WARNING SERVICES

ICGC Institut Cartogràfic i Geològic de Catalunya

Servei Meteorològic de Catalunya meteo.cat

# Boletín de peligro de aludes Perafita-Puigpedrós Del 06/02/2026 al 07/02/2026

(Válido fuera pistas de esquí y zonas no controladas)

MIMITADO (2)

## Situación primaria

**Nieve venteada**

**Distribución**

**Tamaño**

**Origen**

**Tendencia**

**Estado del manto nivoso**

Por encima de los 2300-2400 m, el manto nivoso está constituido por placas que se desarrollaron ayer a sotavento del viento del oeste. Estas placas se formaron primero con nieve fría y después, con la subida de la cota de nieve, con nieve más pesada para acabar de taparse con nieve otra vez más fría. Pueden caer a nuestro paso y alcanzar tamaño suficiente para enterrar a una persona. Se encuentran especialmente en ladera E, N y en algunas zonas S resguardadas del viento de W. Por debajo de los 2300 m el manto nivoso se ha ido endureciendo. La nieve que pueda caer de cara a mañana puede tapar las placas existentes.

**Distribución del manto nivoso**

Hay nieve en el suelo por encima de 1.400-1500 m. Sin embargo, el manto es esquiable por encima de 1.500-1.600 m. Los grosores alcanzan los 130-150 cm a 2.200 m. Son grosores muy por encima de los habituales por la época.

**Tendencia para las próximas 48-72h**

En los próximos días puede volver a nevar, con viento en altura. Las placas de viento se mantendrán todavía reactivas. Peligro ESTACIONARIO.

**El próximo boletín será emitido el día 2026-02-07**

| | | | | |
|---|---|---|---|---|
| 5 MUY FUERTE | 4 FUERTE | 3 NOTABLE | 2 LIMITADO | 1 DÉBIL |

EAWS EUROPEAN AVALANCHE WARNING SERVICES

ICGC Institut Cartogràfic i Geològic de Catalunya

Servei Meteorològic de Catalunya meteo.cat

# Boletín de peligro de aludes
# Vessant Nord Cadí-Moixeró
# Del 06/02/2026 al 07/02/2026

(Válido fuera pistas de esquí y zonas no controladas)

LIMITADO (2)

## Situación primaria

**Nieve venteada**

**Distribución**

**Tamaño**

**Origen**

**Tendencia**

**Estado del manto nivoso**

Por encima de los 2300-2400 m, el manto nivoso está constituido por placas que se desarrollaron ayer a sotavento del viento del oeste. Estas placas se formaron primero con nieve fría y después, con la subida de la cota de nieve, con nieve más pesada para acabar de taparse con nieve otra vez más fría. Pueden caer a nuestro paso y alcanzar tamaño suficiente para enterrar a una persona. Se encuentran especialmente en ladera E, N y en algunas zonas S resguardadas del viento de W. Por debajo de los 2300 m el manto nivoso se ha ido endureciendo. La nieve que pueda caer de cara a mañana puede tapar las placas existentes

**Distribución del manto nivoso**

Hay nieve desde 1.200-1300 m. Norte y desde 1.400-1500 m. Sur, esquiable por encima de unos 1.600 m. Los grosores están alrededor de 150-160 cm a 2.200 m. Estos valores son muy excedentarios para la época del año.

**Tendencia para las próximas 48-72h**

En los próximos días puede volver a nevar, con viento en altura. Las placas de viento se mantendrán todavía reactivas. Peligro ESTACIONARIO.

**El próximo boletín será emitido el día 2026-02-07**

| | | | | |
|---|---|---|---|---|
| 5 MUY FUERTE | 4 FUERTE | 3 NOTABLE | 2 LIMITADO | 1 DÉBIL |

EAWS EUROPEAN AVALANCHE WARNING SERVICES

ICGC Institut Cartogràfic i Geològic de Catalunya

Servei Meteorològic de Catalunya

# Boletín de peligro de aludes Prepirineu
# Del 06/02/2026 al 07/02/2026

(Válido fuera pistas de esquí y zonas no controladas)

LIMITADO (2)

**Situación primaria**

**Nieve venteada**

**Distribución**

**Tamaño**

**Origen**

**Tendencia**

**Estado del manto nivoso**

Por encima de los 2300-2400 m, el manto nivoso está constituido por placas que se desarrollaron ayer a sotavento del viento del oeste. Estas placas se formaron primero con nieve fría y después, con la subida de la cota de nieve, con nieve más pesada para acabar de taparse con nieve otra vez más fría. Pueden caer a nuestro paso y alcanzar tamaño suficiente para enterrar a una persona. Se encuentran especialmente en ladera E, N y en algunas zonas S resguardadas del viento de W. Por debajo de los 2300 m el manto nivoso se ha ido endureciendo. La nieve que pueda caer de cara a mañana puede tapar las placas existentes

**Distribución del manto nivoso**

Hay nieve desde 1400-1500 m. El manto es esquiable a partir de 1600 m. Los grosores están alrededor de 110-130 cm a unos 2.200 my son superiores a los habituales.

**Tendencia para las próximas 48-72h**

En los próximos días puede volver a nevar, con viento en altura. Las placas de viento se mantendrán todavía reactivas. Peligro ESTACIONARIO.

**El próximo boletín será emitido el día 2026-02-07**

| | | | | |
|---|---|---|---|---|
| 5 MUY FUERTE | 4 FUERTE | 3 NOTABLE | 2 LIMITADO | 1 DÉBIL |

EAWS EUROPEAN AVALANCHE WARNING SERVICES

ICGC Institut Cartogràfic i Geològic de Catalunya

Servei Meteorològic de Catalunya meteo.cat

# Boletín de peligro de aludes Ter-Freser Del 06/02/2026 al 07/02/2026

(Válido fuera pistas de esquí y zonas no controladas)

Limitado (2)

## Situación primaria

**Nieve venteada**

**Distribución**

**Tamaño**

**Origen**

**Tendencia**

**Estado del manto nivoso**

Por encima de los 2300-2400 m, el manto nivoso está muy venteado. Aun así hay placas de viento que se desarrollaron ayer a sotavento del viento fuerte de componente oeste. Estas placas se formaron primero con nieve fría y después, con la subida de la cota de nieve, con nieve más pesada para acabar de taparse, en sectores muy resguardados del viento, con nieve otra vez más fría. Pueden caer a nuestro paso y alcanzar tamaño suficiente para enterrar a una persona. Se encuentran especialmente en ladera E, N y en algunas zonas S resguardadas del viento de W. Por debajo de los 2300 m el manto nivoso se ha endureciendo. La nieve que pueda caer de cara a mañana puede tapar las placas existentes

**Distribución del manto nivoso**

El manto nivoso presenta grosores muy excedentarios para la época del año. En lugares no afectados por el viento, los espesores oscilan entre 100-140 cm a unos 2.000 m, siendo esquiable a partir de unos 1.500 m.

**Tendencia para las próximas 48-72h**

En los próximos días puede volver a nevar, con viento en altura. Las placas de viento se mantendrán todavía reactivas. Peligro ESTACIONARIO.

**El próximo boletín será emitido el día 2026-02-07**

| | | | | |
|---|---|---|---|---|
| 5 MUY FUERTE | 4 FUERTE | 3 NOTABLE | 2 LIMITADO | 1 DÉBIL |

EAWS EUROPEAN AVALANCHE WARNING SERVICES